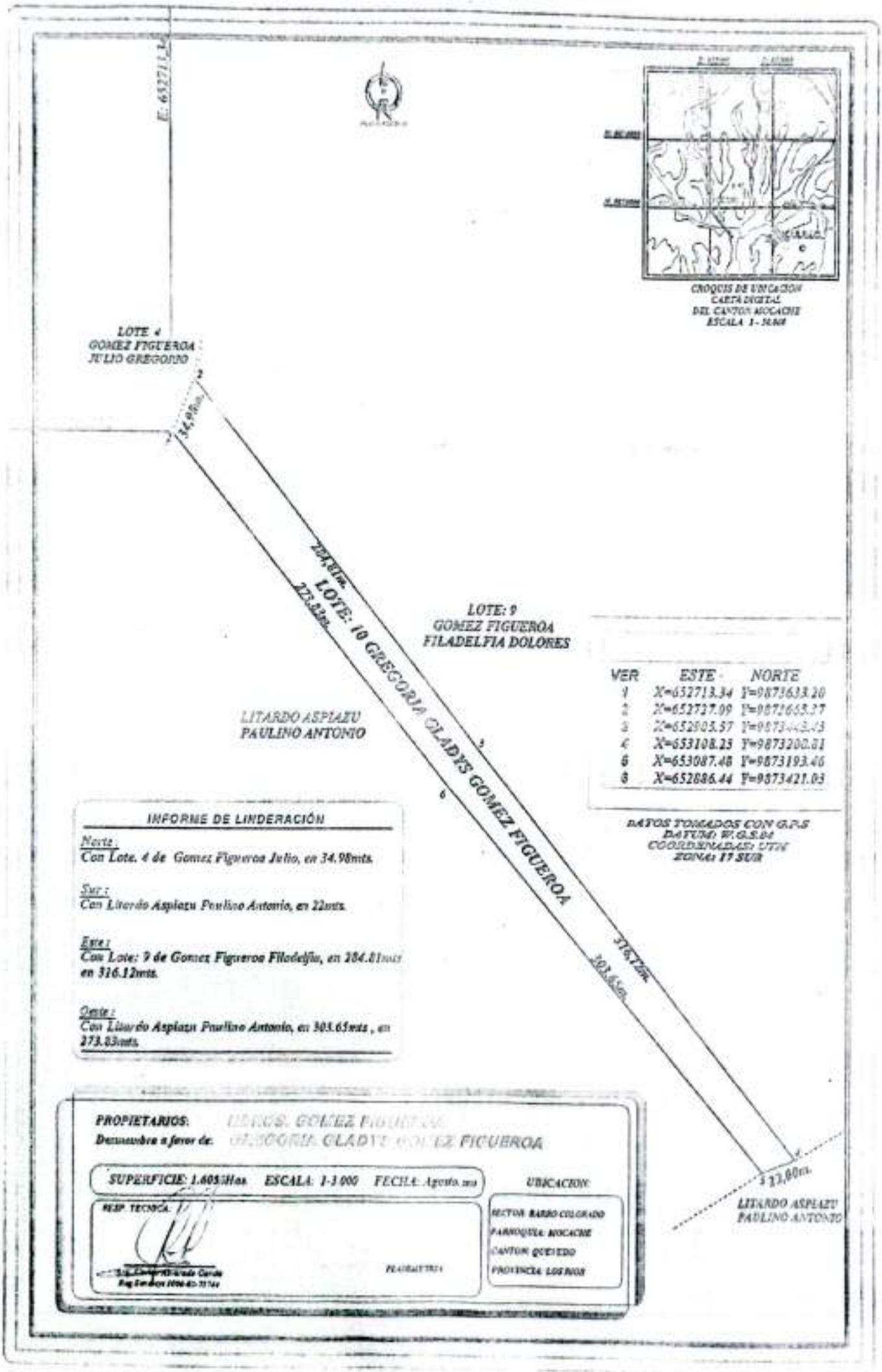

VER	ESTE	NORTE
1	X=652713.34	Y=9873633.20
2	X=652727.09	Y=9873665.37
3	X=652905.57	Y=9873443.43
4	X=653108.23	Y=9873200.81
5	X=653087.48	Y=9873193.46
6	X=652886.44	Y=9873421.03

DATOS TOMADOS CON G.P.S
DATUM: W.G.S.84
COORDENADAS: UTM
ZONA: 17 SUR

INFORME DE LINDERACIÓN

Norte:
Con Lote. 4 de Gomez Figueroa Julio, en 34.98mts.

Sur:
Con Litardo Aspiazu Paulino Antonio, en 22mts.

Este:
Con Lote: 9 de Gomez Figueroa Filadelfia, en 284.81mts en 316.12mts.

Oeste:
Con Litardo Aspiazu Paulino Antonio, en 303.65mts, en 273.83mts.

PROPIETARIOS: [illegible] GOMEZ FIGUEROA
Desmembra a favor de: GREGORIA GLADYS GOMEZ FIGUEROA

SUPERFICIE: 1.605 Has ESCALA: 1-3.000 FECHA: Agosto.mo

UBICACION:
SECTOR: BARRO COLORADO
PARROQUIA: MOCACHE
CANTON: QUEVEDO
PROVINCIA: LOS RIOS

RESP. TECNICA:
[illegible]
Reg. Senescyt 1006-[illegible]

FILADELFIA

Escaneado con CamScanner

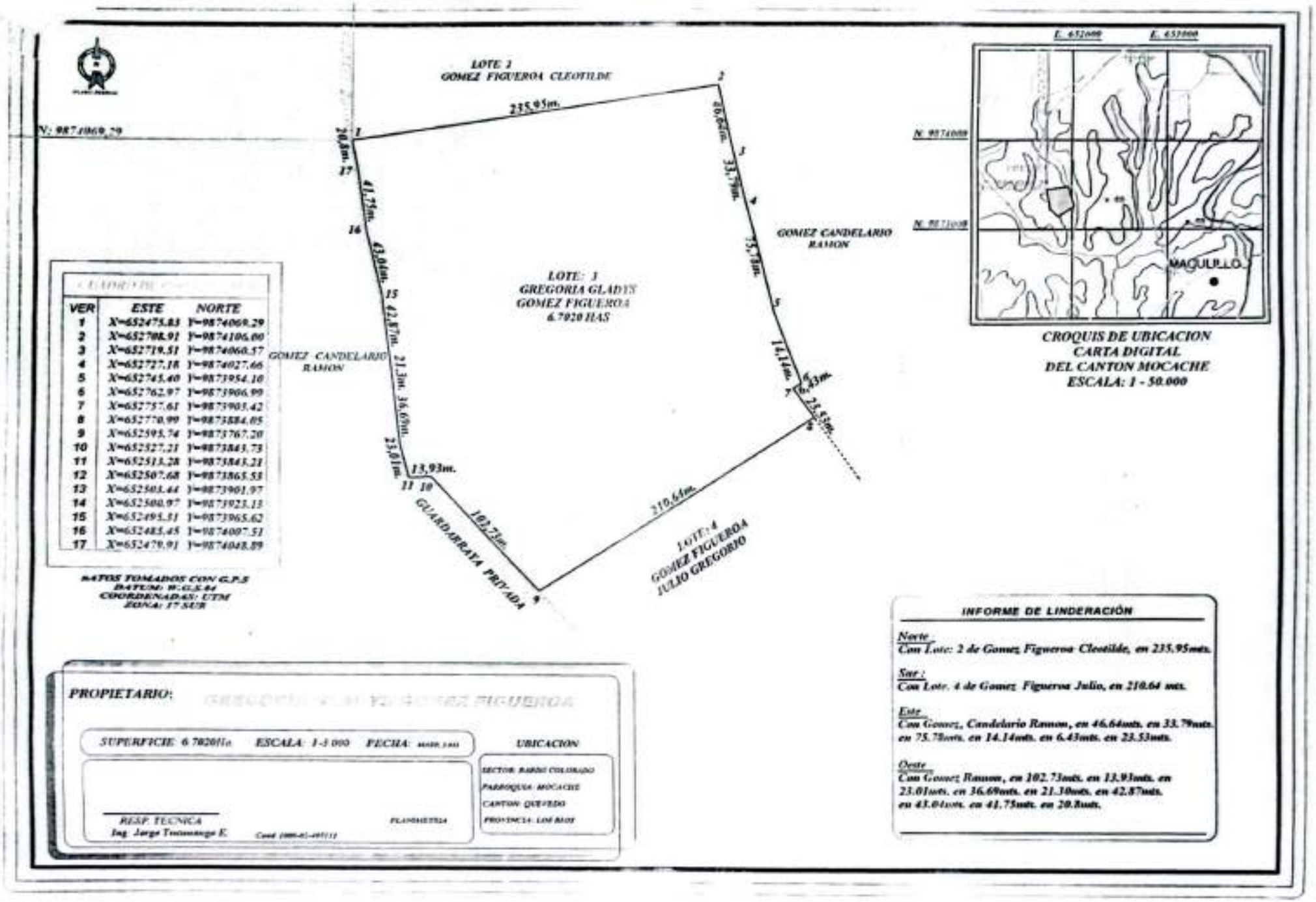

VER	ESTE	NORTE
1	X=652475.83	Y=9874069.29
2	X=652708.91	Y=9874106.00
3	X=652719.51	Y=9874060.57
4	X=652727.18	Y=9874027.66
5	X=652745.40	Y=9873954.10
6	X=652762.97	Y=9873906.99
7	X=652757.61	Y=9873903.42
8	X=652770.99	Y=9873884.05
9	X=652595.74	Y=9873767.20
10	X=652527.21	Y=9873843.73
11	X=652513.28	Y=9873843.21
12	X=652507.68	Y=9873865.53
13	X=652503.44	Y=9873901.97
14	X=652500.97	Y=9873923.13
15	X=652495.51	Y=9873965.62
16	X=652485.45	Y=9874007.51
17	X=652479.91	Y=9874048.89

Escaneado con CamScanner

REGISTRO MUNICIPAL DE LA PROPIEDAD Y MERCANTIL DEL CANTÓN MOCACHE

28 de mayo y bolivar esquina/

NUMERO DE REPERTORIO 88
FECHA DE REPERTORIO 23/01/2024

RAZÓN DE INSCRIPCIÓN

EL REGISTRO MUNICIPAL DE LA PROPIEDAD DEL CANTON MOCACHE, certifica que en esta fecha se inscribió(eron) el(los) siguiente(s) acto(s)

1.- Con fecha veintinueve de enero de dos mil veinticuatro queda inscrito el acto o contrato PARTICION EXTRAJUDICIAL en el Registro de PROPIEDADES No 105 en las fojas 544 a 560 del Tomo 2 celebrado entre ([GOMEZ FIGUEROA TERENCIA DE JESUS en calidad de HEREDERO], [GOMEZ FIGUEROA JULIO GREGORIO en calidad de HEREDERO], [GOMEZ FIGUEROA CLEOTILDE MERCEDES en calidad de HEREDERO], [GOMEZ FIGUEROA FILADELFIA DOLORES en calidad de HEREDERO], [GOMEZ CANDELARIO JULIO ALBERTO en calidad de CAUSANTE-PROPIETARIO], [GOMEZ FIGUEROA LUIS FRANCISCO en calidad de HEREDERO], [GOMEZ FIGUEROA GREGORIA GLADYS en calidad de HEREDERO])

2.- Con fecha veintinueve de enero de dos mil veinticuatro queda inscrito el acto o contrato ADJUDICACION en el Registro de PROPIEDADES No. 106 en las fojas 561 a 561 del Tomo 2 celebrado entre ([GOMEZ FIGUEROA TERENCIA DE JESUS en calidad de HEREDERO ADJUDICATARIO], [GOMEZ FIGUEROA JULIO GREGORIO en calidad de HEREDERO ADJUDICANTE], [GOMEZ FIGUEROA CLEOTILDE MERCEDES en calidad de HEREDERO ADJUDICANTE], [GOMEZ FIGUEROA FILADELFIA DOLORES en calidad de HEREDERO ADJUDICANTE], [GOMEZ FIGUEROA LUIS FRANCISCO en calidad de HEREDERO ADJUDICANTE], [GOMEZ FIGUEROA GREGORIA GLADYS en calidad de HEREDERO ADJUDICANTE])

3.- Con fecha veintinueve de enero de dos mil veinticuatro queda inscrito el acto o contrato ADJUDICACION en el Registro de PROPIEDADES No. 107 en las fojas 562 a 562 del Tomo 2 celebrado entre ([GOMEZ FIGUEROA TERENCIA DE JESUS en calidad de HEREDERO ADJUDICANTE], [GOMEZ FIGUEROA JULIO GREGORIO en calidad de HEREDERO ADJUDICATARIO], [GOMEZ FIGUEROA CLEOTILDE MERCEDES en calidad de HEREDERO ADJUDICANTE], [GOMEZ FIGUEROA FILADELFIA DOLORES en calidad de HEREDERO ADJUDICANTE], [GOMEZ FIGUEROA LUIS FRANCISCO en calidad de HEREDERO ADJUDICANTE], [GOMEZ FIGUEROA GREGORIA GLADYS en calidad de HEREDERO ADJUDICANTE])

4.- Con fecha veintinueve de enero de dos mil veinticuatro queda inscrito el acto o contrato ADJUDICACION en el Registro de PROPIEDADES No. 108 en las fojas 563 a 563 del Tomo 2 celebrado entre ([GOMEZ FIGUEROA TERENCIA DE JESUS en calidad de HEREDERO ADJUDICANTE], [GOMEZ FIGUEROA JULIO GREGORIO en calidad de HEREDERO ADJUDICANTE], [GOMEZ FIGUEROA CLEOTILDE MERCEDES en calidad de HEREDERO ADJUDICATARIO], [GOMEZ FIGUEROA FILADELFIA DOLORES en calidad de HEREDERO ADJUDICANTE], [GOMEZ FIGUEROA LUIS FRANCISCO en calidad de HEREDERO ADJUDICANTE], [GOMEZ FIGUEROA GREGORIA GLADYS en calidad de HEREDERO ADJUDICANTE])

5.- Con fecha veintinueve de enero de dos mil veinticuatro queda inscrito el acto o contrato ADJUDICACION en el Registro de PROPIEDADES No. 109 en las fojas 564 a 564 del Tomo 2 celebrado entre ([GOMEZ FIGUEROA TERENCIA DE JESUS en calidad de HEREDERO ADJUDICANTE], [GOMEZ FIGUEROA JULIO GREGORIO en calidad de HEREDERO ADJUDICANTE], [GOMEZ FIGUEROA CLEOTILDE MERCEDES en calidad de HEREDERO ADJUDICANTE], [GOMEZ FIGUEROA FILADELFIA DOLORES en calidad de HEREDERO ADJUDICANTE], [GOMEZ FIGUEROA LUIS FRANCISCO en calidad de HEREDERO ADJUDICANTE], [GOMEZ FIGUEROA GREGORIA GLADYS en calidad de HEREDERO ADJUDICATARIO])

6.- Con fecha veintinueve de enero de dos mil veinticuatro queda inscrito el acto o contrato ADJUDICACION en el Registro de PROPIEDADES No. 110 en las fojas 565 a 565 del Tomo 2 celebrado entre ([GOMEZ FIGUEROA TERENCIA DE JESUS en calidad de HEREDERO ADJUDICANTE], [GOMEZ FIGUEROA JULIO GREGORIO en calidad de HEREDERO ADJUDICANTE], [GOMEZ FIGUEROA CLEOTILDE MERCEDES en calidad de HEREDERO ADJUDICANTE], [GOMEZ FIGUEROA FILADELFIA DOLORES en calidad de HEREDERO ADJUDICATARIO], [GOMEZ FIGUEROA LUIS FRANCISCO en calidad de HEREDERO ADJUDICANTE], [GOMEZ FIGUEROA GREGORIA GLADYS en calidad de HEREDERO ADJUDICANTE])

7.- Con fecha veintinueve de enero de dos mil veinticuatro queda inscrito el acto o contrato ADJUDICACION

Escaneado con CamScanner

RAZON DE INSCRIPCION

en el Registro de PROPIEDADES No 111 en las fojas 566 a 566 del Tomo 2 celebrado entre ([GOMEZ FIGUEROA TERENCIA DE JESUS en calidad de HEREDERO ADJUDICANTE], [GOMEZ FIGUEROA JULIO GREGORIO en calidad de HEREDERO ADJUDICANTE], [GOMEZ FIGUEROA CLEOTILDE MERCEDES en calidad de HEREDERO ADJUDICANTE], [GOMEZ FIGUEROA FILADELFIA DOLORES en calidad de HEREDERO ADJUDICANTE], [GOMEZ FIGUEROA LUIS FRANCISCO en calidad de HEREDERO ADJUDICATARIO], [GOMEZ FIGUEROA GREGORIA GLADYS en calidad de HEREDERO ADJUDICANTE])

8 - Con fecha veintinueve de enero de dos mil veinticuatro queda inscrito el acto o contrato ADJUDICACION en el Registro de PROPIEDADES No 112 en las fojas 567 a 567 del Tomo 2 celebrado entre ([GOMEZ FIGUEROA TERENCIA DE JESUS en calidad de HEREDERO ADJUDICATARIO], [GOMEZ FIGUEROA JULIO GREGORIO en calidad de HEREDERO ADJUDICATARIO], [GOMEZ FIGUEROA CLEOTILDE MERCEDES en calidad de HEREDERO ADJUDICANTE], [GOMEZ FIGUEROA FILADELFIA DOLORES en calidad de HEREDERO ADJUDICANTE], [GOMEZ FIGUEROA LUIS FRANCISCO en calidad de HEREDERO ADJUDICANTE], [GOMEZ FIGUEROA GREGORIA GLADYS en calidad de HEREDERO ADJUDICANTE])

9 - Con fecha veintinueve de enero de dos mil veinticuatro queda inscrito el acto o contrato ADJUDICACION en el Registro de PROPIEDADES No 113 en las fojas 568 a 568 del Tomo 2 celebrado entre ([GOMEZ FIGUEROA TERENCIA DE JESUS en calidad de HEREDERO ADJUDICANTE], [GOMEZ FIGUEROA JULIO GREGORIO en calidad de HEREDERO ADJUDICANTE], [GOMEZ FIGUEROA CLEOTILDE MERCEDES en calidad de HEREDERO ADJUDICATARIO], [GOMEZ FIGUEROA FILADELFIA DOLORES en calidad de HEREDERO ADJUDICANTE], [GOMEZ FIGUEROA LUIS FRANCISCO en calidad de HEREDERO ADJUDICATARIO], [GOMEZ FIGUEROA GREGORIA GLADYS en calidad de HEREDERO ADJUDICANTE])

10 - Con fecha veintinueve de enero de dos mil veinticuatro queda inscrito el acto o contrato ADJUDICACION en el Registro de PROPIEDADES No 114 en las fojas 569 a 569 del Tomo 2 celebrado entre ([GOMEZ FIGUEROA TERENCIA DE JESUS en calidad de HEREDERO ADJUDICANTE], [GOMEZ FIGUEROA JULIO GREGORIO en calidad de HEREDERO ADJUDICANTE], [GOMEZ FIGUEROA CLEOTILDE MERCEDES en calidad de HEREDERO ADJUDICANTE], [GOMEZ FIGUEROA FILADELFIA DOLORES en calidad de HEREDERO ADJUDICATARIO], [GOMEZ FIGUEROA LUIS FRANCISCO en calidad de HEREDERO ADJUDICANTE], [GOMEZ FIGUEROA GREGORIA GLADYS en calidad de HEREDERO ADJUDICATARIO])

QUE SE REFIERE AL/LOS) SIGUIENTE(S) BIEN(ES)

TIPO BIEN	COD CATASTRAL/ IDENT. PREDIAL	NRO. FICHA	ACTOS
TERRENO		14.105	Adjudicacion
TERRENO		14.106	Adjudicacion
TERRENO		14.107	Adjudicacion
TERRENO		14.108	Adjudicacion
TERRENO		14.109	Adjudicacion
TERRENO		14.110	Adjudicacion
TERRENO		14.111	Adjudicacion
TERRENO		14.112	Adjudicacion
TERRENO		14.113	Adjudicacion
TERRENO		14.114	Adjudicacion
TERRENO		14.115	Adjudicacion
TERRENO		14.116	Adjudicacion
TERRENO		14.117	Adjudicacion
TERRENO		9.530	Particion Extrajudicial

Escaneado con CamScanner

REGISTRO MUNICIPAL DE LA PROPIEDAD Y MERCANTIL DEL CANTÓN MOCACHE

28 de mayo y bolivar esquina/

NUMERO DE REPERTORIO 89
FECHA DE REPERTORIO 23/01/2024

RAZÓN DE INSCRIPCIÓN

TERRENO | 9 532 | Particion Extrajudicial

MOCACHE, lunes 29 de enero de 2 024
Impreso a las 10 52 56a m

Dr Manuel Bravo Bodero
REGISTRADOR DE LA PROPIEDAD (E)

Dr. Manuel Bravo Bodero
ABOGADO
Mat. N°. 24-2007-24

Escaneado con CamScanner

Factura: 003-002-000085784

20231205006O00656

EXTRACTO COPIA DE ARCHIVO N° 20231205006O00656

NOTARIO OTORGANTE:	DOCTOR CARLOS ARMANDO MENDOZA GARCIA NOTARIO(A) DEL CANTON QUEVEDO
FECHA:	19 DE DICIEMBRE DEL 2023, (15:55)
COPIA DEL TESTIMONIO:	SEXTO
ACTO O CONTRATO:	PARTICION Y/O ADJUDICACION

OTORGANTES			
OTORGADO POR			
NOMBRES/RAZÓN SOCIAL	TIPO INTERVINIENTE	DOCUMENTO DE IDENTIDAD	No. IDENTIFICACIÓN
GOMEZ FIGUEROA TERENCIA DE JESUS	POR SUS PROPIOS DERECHOS S	CÉDULA	0909788535
GOMEZ FIGUEROA JULIO GREGORIO	POR SUS PROPIOS DERECHOS S	CÉDULA	0912744240
GOMEZ FIGUEROA LUIS FRANCISCO	POR SUS PROPIOS DERECHOS C	CÉDULA	1202559666
GOMEZ FIGUEROA CLEOTILDE MERCEDES	POR SUS PROPIOS DERECHOS C	CÉDULA	0912753993
GOMEZ FIGUEROA GREGORIA GLADYS	POR SUS PROPIOS DERECHOS C	CÉDULA	1203580491
GOMEZ FIGUEROA FILADELFIA DOLORES	POR SUS PROPIOS DERECHOS S	CÉDULA	0912754009
A FAVOR DE			
NOMBRES/RAZÓN SOCIAL	TIPO INTERVINIENTE	DOCUMENTO DE IDENTIDAD	No. IDENTIFICACIÓN

FECHA DE OTORGAMIENTO:	12-..-2023
NOMBRE DEL PETICIONARIO:	LUIS GOMEZ FIGUEROA
N° IDENTIFICACIÓN DEL PETICIONARIO:	1202559666-6

OBSERVACIONES:

NOTARIO(A) CARLOS ARMANDO MENDOZA GARCIA

NOTARÍA SEXTA DEL CANTON QUEVEDO

GAD MUNICIPAL DE MOCACHE
DPTO AVALUOS Y CATASTROS
CATASTRADA
FECHA 02-01-2024 AREA 1.6051 HAS
CLAVE ANT. 4846
CLAVE ACT. 22610
IDENT PREDIAL 12-2280
RESPONSABLE

GAD MUNICIPAL DE MOCACHE
DPTO AVALUOS Y CATASTROS
CATASTRADA
FECHA 02-01-2024 AREA 5.3020 HAS
CLAVE ANT. 4846
CLAVE ACT. 22611
IDENT PREDIAL 12-2281
RESPONSABLE

Escaneado con CamScanner

Factura: 003-002-000085773

20231205006P02375

NOTARIO(A) CARLOS ARMANDO MENDOZA GARCIA

NOTARÍA SEXTA DEL CANTON QUEVEDO

EXTRACTO

Escritura N°	20231205006P02375

ACTO O CONTRATO:

PARTICIÓN Y/O ADJUDICACIÓN

FECHA DE OTORGAMIENTO:	19 DE DICIEMBRE DEL 2023, (19:55)

OTORGANTES

OTORGADO POR

Persona	Nombres/Razón social	Tipo interviniente	Documento de identidad	No. Identificación	Nacionalidad	Calidad	Persona que le representa

A FAVOR DE

Persona	Nombres/Razón social	Tipo interviniente	Documento de identidad	No. Identificación	Nacionalidad	Calidad	Persona que representa
Natural	GOMEZ FIGUEROA TERENCIA DE JESUS	POR SUS PROPIOS DERECHOS	CÉDULA	0909786535	ECUATORIANA	ADJUDICATARIO (A)	
Natural	GOMEZ FIGUEROA JULIO GREGORIO	POR SUS PROPIOS DERECHOS	CÉDULA	0912744240	ECUATORIANA	ADJUDICATARIO (A)	
Natural	GOMEZ FIGUEROA LUIS FRANCISCO	POR SUS PROPIOS DERECHOS	CÉDULA	1203559686	ECUATORIANA	ADJUDICATARIO (A)	
Natural	GOMEZ FIGUEROA CLEOTILDE MERCEDES	POR SUS PROPIOS DERECHOS	CÉDULA	0912753093	ECUATORIANA	ADJUDICATARIO (A)	
Natural	GOMEZ FIGUEROA GREGORIA GLADYS	POR SUS PROPIOS DERECHOS	CÉDULA	1203580491	ECUATORIANA	ADJUDICATARIO (A)	
Natural	GOMEZ FIGUEROA FILADELFIA DOLORES	POR SUS PROPIOS DERECHOS	CÉDULA	0912754009	ECUATORIANA	ADJUDICATARIO (A)	

UBICACION

Provincia	Cantón	Parroquia
LOS RIOS	QUEVEDO	24 DE MAYO

DESCRIPCION DOCUMENTO:

OBJETO/OBSERVACIONES

CUANTIA DEL ACTO O CONTRATO:	65134.00

NOTARIO(A) CARLOS ARMANDO MENDOZA GARCIA

NOTARÍA SEXTA DEL CANTÓN QUEVEDO

NOTARIA SEXTA DEL CANTÓN QUEVEDO PROV. DE LOS RIOS DR. CARLOS MENDOZA GARCIA NOTARIO TITULAR

Escaneado con CamScanner

NOTARIA SEXTA
CANTON QUEVEDO
LOS RIOS - ECUADOR

Numero: 20231205006P02875.-

ESCRITURA PÚBLICA DE PARTICIÓN EXTRAJUDICIAL Y ADJUDICACIÓN QUE CELEBRAN LOS HEREDEROS DEL CAUSANTE QUIEN EN VIDA SE LLAMO JULIO ALBERTO GOMEZ CANDELARIO.---

CUANTIA: $ 65.134,18.----------

DI: 2 COPIAS:

En la Ciudad de Quevedo, cabecera del Cantón del mismo nombre, Provincia de Los Ríos, República del Ecuador, el día de hoy diecinueve de diciembre del año dos mil veintitrés, ante mí, **Doctor CARLOS ARMANDO MENDOZA GARCIA,** Magister, Notario Sexto de este Cantón, celebración de la presente escritura pública, con plena capacidad, libertad y entendimiento, por una parte, por sus propios derechos, por una parte, por sus propios derechos, los señores: **TERENCIA DE JESUS GOMEZ FIGUEROA,** de estado civil soltero, de ocupación Quehaceres Domésticos, con domicilio y residencia en la Ciudad del Empalme, de tránsito por esta Ciudad, quien me proporciona su número de teléfono celular cero nueve seis ocho cuatro cuatro dos seis tres siete, y correo electrónico terenciagomez4@gmail.com, **JULIO**

Escaneado con CamScanner

GREGORIO GOMEZ FIGUEROA, de estado civil soltero, de ocupación albañil, con domicilio y residencia en la Ciudad del Empalme, de tránsito por esta Ciudad, quien me proporciona su número de teléfono celular cero nueve siete nueve cinco nueve nueve siete nueve dos, y correo electrónico juliogregoriogomezfigueroa5@gmail.com, **LUIS FRANCISCO GOMEZ FIGUEROA**, de estado civil casado, de ocupación agricultor, con domicilio y residencia en el Cantón El Empalme, de tránsito por esta Ciudad, quien me proporciona su número de teléfono celular cero nueve ocho seis cinco ocho nueve uno siete cinco, y correo electrónico gomezluisfrancisco44@gmail.com; **CLEOTILDE MERCEDES GOMEZ FIGUEROA**, de estado civil casada, de ocupación comerciante, con domicilio y residencia en la Ciudad de Machala, de tránsito por esta Ciudad, quien me proporciona su número de teléfono celular cero nueve nueve dos dos tres cinco dos seis siete, y correo electrónico mechegf@outlook.com, **FILADELFIA DOLORES GOMEZ FIGUEROA**, de estado civil soltera, de ocupación estudiante, con domicilio y residencia en la Ciudad de Guayaquil, de tránsito por esta Ciudad, quien me proporciona su número de teléfono celular cero nueve nueve siete cuatro dos seis nueve siete uno, y correo electrónico filadelfiagomez@hotmail.com; y, **GREGORIA GLADYS GOMEZ FIGUEROA**, de estado civil casada, de ocupación empleada, con domicilio y residencia en la Ciudad de Quito, de tránsito por esta Ciudad, quien me proporciona su número de teléfono celular cero nueve nueve cuatro cinco seis seis

Escaneado con CamScanner

ocho ocho cero, y correo electrónico gomez28figueroa@gmail.com.- Los comparecientes declaran ser de nacionalidad ecuatoriana, mayores de edad, hábiles en derecho para contratar y contraer obligaciones, a quienes de conocer en este acto doy fe. - En virtud de haberme exhibido sus documentos de identificación, así como también bajo la autorización de los titulares, conforme lo determina el artículo setenta y cinco de la ley Orgánica de Gestión de Identidad y Datos Civiles, accedo e imprimo los certificados digitales de datos de identidad que agrego. Advertidos los comparecientes por mí el Notario de los efectos y resultados de esta escritura pública, así como examinados que fueron en forma aislada y separada de que comparecen al otorgamiento de esta escritura pública, sin coacción, amenazas, temor reverencial, ni promesa o seducción, me piden que eleve a escritura pública la siguiente minuta.- **SEÑOR NOTARIO**: En el Registro de escrituras públicas a su cargo, sírvase insertar una de **Partición Extrajudicial, Adjudicación**, de conformidad con las siguientes cláusulas.- **PRIMERA: INTERVINIENTES**.- Comparecen a suscribir la presente escritura pública de Partición Extrajudicial y **Adjudicación**, de los bienes relictos dejados por quien en vida se llamó **JULIO ALBERTO GOMEZ CANDELARIO**, por sus propios derechos, los señores: **TERENCIA DE JESUS GOMEZ FIGUEROA, JULIO GREGORIO GOMEZ FIGUEROA, LUIS FRANCISCO GOMEZ FIGUEROA, CLEOTILDE MERCEDES GOMEZ FIGUEROA, FILADELFIA DOLORES GOMEZ FIGUEROA; y,**

Escaneado con CamScanner

GREGORIA GLADYS GOMEZ FIGUEROA, a quienes en adelante y para efectos de este instrumento se les denominara simplemente los **ADJUDICATARIOS**, los comparecientes se encuentran investidos de la capacidad civil y suficiente para celebrar este tipo de instrumento público.- **SEGUNDA: ANTECEDENTES.-** Los comparecientes señores: **TERENCIA DE JESUS GOMEZ FIGUEROA, JULIO GREGORIO GOMEZ FIGUEROA, LUIS FRANCISCO GOMEZ FIGUEROA, CLEOTILDE MERCEDES GOMEZ FIGUEROA, FILADELFIA DOLORES GOMEZ FIGUEROA; y, GREGORIA GLADYS GOMEZ FIGUEROA**, por sus propios derechos, declaran que cuando vivía su querido y recordado padre quien en vida se llamó **[illegible]**, este tenía en propiedad los siguientes bienes.- a).- Mediante Providencia número **NUEVE UNO CERO CERO CERO CINCO CINCO SEIS UNO**, de fecha Quito nueve de julio del año mil novecientos noventa y uno, Protocolizada en la Notaria Segunda del Cantón Quevedo, el diecinueve de julio del año mil novecientos noventa y uno, inscrita legalmente en el Registro de la Propiedad del Cantón Quevedo, bajo el número doce mil cincuenta y cuatro en el Registro de Propiedades y anotada al número cuatro mil doscientos diecisés en el Libro Repertorio, el diecisiete de septiembre del año mil novecientos noventa y uno, posteriormente reinscrita en el Registro de la Propiedad del Cantón Mocache, bajo el número doscientos sesenta y ocho del Registro de Propiedades y anotada al número trescientos

Escaneado con CamScanner

ochenta y tres del Libro Repertorio, el catorce de junio del año dos mil dieciocho, por la cual dicho instituto Adjudico a favor del señor **JULIO ALBERTO GOMEZ CANDELARIO**, Tres Lotes con una superficie de **SIETE HECTAREAS, OCHO HECTAREAS TREINTA AREAS; y, CUATRO HECTAREAS SESENTA AREAS**, que dan una superficie total de **DIECINUEVE HECTAREAS NOVENTA AREAS**, ubicado en la zona cuarenta y siete, jurisdicción del Cantón Mocache, Provincia de Los Ríos, con los siguientes linderos y medidas; **LOTE DE SIETE HECTAREAS, por el NORTE**: Cooperativa El Triunfo, en setenta y siete metros rumbo norte, ochenta y seis grados treinta minutos Este, ciento veintidós metros Rumbo Sur ochenta grados cero cero minutos Este, ciento veintidós metros Rumbo sur ochenta grados cero cero minutos Este; **por el SUR**: Enrique Vera, en doscientos veinticinco metros rumbo sur noventa grados cero cero minutos Oeste; **por el ESTE**: Agustín Mora, en ciento quince metros rumbo sur dos grados cuarenta y cinco minutos W y en doscientos cuarenta y dos metros rumbo sur dieciséis grados quince minutos Este; **por el OESTE**: Gerardo Guillen en cien metros Norte dieciocho grados cero cero minutos W, cuarenta y seis metros rumbo sur ochenta grados cero cero minutos Oeste, Teodoro Litardo en ciento veinte metros Rumbo norte cuarenta y nueve grados cero cero minutos Este, ciento setenta y cinco metros Norte cinco grados cuarenta y cinco minutos Oeste treinta y cuatro metros Norte treinta y nueve grados quince minutos Oeste, **LOTE DE OCHO COMA TREINTA HECTAREAS; por el**

Escaneado con CamScanner

NORTE: José Arriaga en cincuenta metros rumbo norte ochenta y cinco grados cero cero minutos Este; **por el SUR**: Lotes de María Aspiazu y Marco Aspiazu, en ciento noventa y ocho metros rumbo sur setenta y seis grados cero cero minutos Oeste, sesenta metros rumbo sur setenta grados cero cero minutos W; **por el ESTE**: Lotes de Julio Gómez, Ramon Gómez y Pascual Romero, en cuatrocientos ochenta metros rumbo sur catorce grados cero cero minutos Este, ciento ochenta y cuatro metros rumbo norte setenta y ocho grados cero cero minutos Este, cuarenta metros rumbo sur trece grados treinta minutos Este, ciento cincuenta metros sur veinticinco grados treinta minutos Este, cincuenta y siete metros rumbo sur, dos grados treinta minutos; y, por el OESTE: Ramon Gómez, en quinientos veintidos metros rumbo norte once grados cero cero minutos Oeste, doscientos metros rumbo norte once grados cero cero minutos Oeste, doscientos veinticinco metros rumbo norte, diecisiete grados cero cero minutos Oeste; Lote de **CUATRO COMA SESENTA HECTAREAS**; por el **NORTE:** Antonio Coque, en doscientos quince metros rumbo norte ochenta y un grados treinta minutos Este; por el SUR: Ramon Gómez en ciento sesenta y cuatro metros rumbo norte ochenta y dos grados cero cero minutos Oeste, setenta y cinco metros rumbo norte setenta y cuatro grados cero cero minutos Este; Pascual Romero en doscientos diecisiete metros rumbo sur catorce grados treinta minutos Oeste; Julio Gómez en ciento cuarenta y cuatro metros rumbo norte trece grados treinta minutos Oeste.- **b)** - Mediante escritura pública celebrada en

Escaneado con CamScanner

la Notaría Tercera del Cantón Quevedo, el trece de marzo del año dos mil dos, autorizada en ese entonces por el señor Abogado Abel Germán León León, Notario Público, inscrita legalmente en el Registro de la Propiedad del Cantón Mocache, bajo el número doscientos setenta en el Registro de Propiedades y anotada al número trescientos ochenta y cinco del Libro Repertorio, el catorce de junio del año dos mil dieciocho, por la cual los señores Marcos Alcides Aspiazu Litardo y Alicia Susana Montoya Vera, vendieron a favor del señor **JULIO ALBERTO GOMEZ CANDELARIO**, el lote de terreno de la superficie de **QUINCE HECTAREAS OCHENTA AREAS**, ubicado en la zona número cuarenta y siete, de la jurisdicción de la Parroquia y Cantón Mocache, Provincia de Los Ríos, circunscrito dentro de los siguientes linderos y medidas; por el **NORTE**: Pedro Figueroa y Casimiro Méndez; por el **SUR**: Julio Litardo; por el **ESTE**: Con propiedad de Marta Litardo, y, por el **OESTE**: Con propiedad de la señora Petra Litardo.- **c)**.- Que al fallecimiento del causante quien en vida se llamó **JULIO ALBERTO GOMEZ CANDELARIO**, hecho ocurrido el veintiocho de abril del año dos mil dieciocho, en la Parroquia Tarqui, Cantón Guayaquil, Provincia del Guayas, le han sucedido en todos sus derechos como sus únicos y universales herederos sus hijos señores: **TERENCIA DE JESUS GOMEZ FIGUEROA, JULIO GREGORIO GOMEZ FIGUEROA, LUIS FRANCISCO GOMEZ FIGUEROA, CLEOTILDE MERCEDES GOMEZ FIGUEROA, FILADELFIA DOLORES GOMEZ FIGUEROA; y,**

Escaneado con CamScanner

GREGORIA GLADYS GOMEZ FIGUEROA, conforme lo justifican el **Acta de Posesión Efectiva,** concedida, por la Notaria Primera Titular del Cantón El Empalme, el veintidós de Junio del año dos mil dieciocho, e inscrita legalmente en el Registro de la propiedad del Cantón Mocache, bajo el número veintinueve del Registro de Sentencias, y anotada al número cuatrocientos sesenta y uno del libro repertorio, el trece de Julio del año dos mil dieciocho.- dj.- Mediante escritura pública celebrada en la Notaria Primera del Cantón Mocache, el diecinueve de julio del año dos mil veintiuno, autorizada por el Doctor Juan Francisco Aguirre Bajaña, Notario Público, inscrita legalmente en el Registro de la Propiedad del Cantón Mocache, bajo el número setecientos setenta y siete del Registro de Propiedades y anotada al número setecientos sesenta y nueve del Libro Repertorio, el cinco de agosto del año dos mil veintiuno, por la cual los señores: **TERENCIA DE JESUS GOMEZ FIGUEROA, JULIO GREGORIO GOMEZ FIGUEROA, LUIS FRANCISCO GOMEZ FIGUEROA, CLEOTILDE MERCEDES GOMEZ FIGUEROA, FILADELFIA DOLORES GOMEZ FIGUEROA; y, GREGORIA GLADYS GOMEZ FIGUEROA,** realizaron **ACLARATORIA** de LINDEROS, MEDIDAS Y SUPERFICIE de los lotes **UNO** es; **NORTE**: Con Mendoza Margarita, en ciento un metros ochenta y siete centímetros, en ciento cincuenta y cuatro metros ochenta y un centímetros; con Vera Florencio, en setenta y un metros veintinueve centímetros, en ciento ochenta y un metros; con Bustamante Alvarado Herederos, en ciento cincuenta y tres metros

Escaneado con CamScanner

ochenta y cuatro centímetros, en treinta y dos metros veintiocho centímetros; **SUR:** Con Estero Peñafiel, en cincuenta y nueve metros ochenta y dos centímetros, en ochenta y un metros cero un centímetros, en cuarenta y tres metros cuarenta y dos centímetros siguiendo su rumbo, con Carranza Alvarado Mayra, en ciento veinticinco metros setenta y ocho centímetros; con Carranza Alvarado María, en doscientos cincuenta y cuatro metros cuarenta y siete centímetros; con Carretera Mocache – Huancavilca, en ciento diecinueve metros noventa y cuatro centímetros; **ESTE:** Con zona Pantonosa, en cincuenta y ocho metros sesenta y nueve centímetros, en cuarenta y cuatro metros cuarenta y dos centímetros, en cuarenta y nueve metros cero cuatro centímetros, en veintiocho metros cuarenta y tres centímetros, con Aguirre Moran Fraterno Demetrio, en ciento noventa y dos metros treinta y siete centímetros, en setenta y un metros cuarenta y siete centímetros, en cincuenta y un metros sesenta y seis centímetros, en treinta y seis metros cero seis centímetros, en treinta y siete metros sesenta y cuatro centímetros, en cuarenta y nueve metros veintiuno centímetros, en veinticuatro metros sesenta centímetros, y, **OESTE:** Con Petao Aspiazu Herederos, en ciento cincuenta y ocho metros treinta y ocho centímetros, en ciento cinco metros treinta y ocho centímetros, con Hemba Aspiazu Herederos, en cincuenta metros noventa y tres centímetros; con Aspiazu Nelson, en ochenta y nueve metros ochenta y siete centímetros; con Aspiazu Julia, en cuarenta y tres metros ochenta y dos centímetros, quedando una superficie

Escaneado con CamScanner

de **SIETE HECTAREAS SIETE MIL DOSCIENTOS TRECE METROS CUADRADOS; LOTE DOS; NORTE:** Con Arriaga José, en cincuenta metros R.N. ochenta y cinco grados cero minutos cero punto cero cero segundo cero cero; **SUR:** Con Vera Enrique, en doscientos veinticinco metros R. S. noventa grados cero minutos cero punto cero cero segundo cero cero W; **ESTE:** Con Gómez Julio, Gómez Ramón, Romero Pascual, en cuatrocientos ochenta metros R.S. catorce grados cero minutos cero punto cero cero segundos cero cero E, en ciento ochenta y cuatro metros R. N. setenta y ocho grados cero minutos cero punto cero cero segundos cero cero E, en cuarenta metros R.S. trece grados treinta minutos cero punto cero cero segundo cero cero E, en ciento cincuenta metros R.S. veinticinco grados treinta minutos cero punto cero cero segundos cero cero E, cincuenta y siete metros R.S dos grados treinta minutos cero punto cero cero segundo cero cero E; y, **OESTE:** Con Gómez Ramón, en quinientos veintidós metros R.N once grados cero minutos cero punto cero cero segundo cero cero W, en dos cientos veinticinco metros RN dieciciete grados cero minutos cero punto cero cero segundos cero cero W, en doscientos veinticinco metros R.N dieciciete grados cero minutos cero punto cero cero segundos cero cero W, área total **OCHO HECTAREAS CON TRES MIL METROS CUADRADOS.- LOTE TRES**, circunscrito dentro de los siguientes linderos y medidas; **NORTE:** Con Coque Antonio, en doscientos quince metros Rumbo Norte ochenta y un grados treinta minutos cero cero segundos E; **SUR:** Con Gómez Ramón, en ciento

Escaneado con CamScanner

sesenta y cuatro metros Rumbo Norte ochenta y dos grados cero cero minutos W, en setenta y cinco metros Rumbo Norte setenta y cuatro grados cero cero minutos W; **ESTE:** Con Romero Pascual, en doscientos dieciocho metros Rumbo Sur catorce grados treinta minutos cero cero segundos E; y, **OESTE:** Con Gómez Julio, en ciento cuarenta y cuatro metros Rumbo Norte trece grados treinta minutos cero cero segundos W, área total **CUATRO HECTAREAS SESENTA AREAS**, quedando una superficie actual para el lote de **VEINTE HECTAREAS CON SEIS MIL DOSCIENTOS TRECE METROS CUADRADOS**, ubicado en el sector Maculillo Bajo, jurisdicción de la Parroquia Mocache, Cantón Quevedo, hoy Cantón Mocache, Provincia de Los Ríos.- c.) Mediante escritura pública celebrada en la Notaria Sexta del Cantón Quevedo, el diez de febrero del año dos mil veintitrés, autorizada por el Doctor Carlos Armando Mendoza García, Notario Público, e inscrita legalmente en el Registro de la Propiedad del Cantón Mocache, bajo el número trescientos cuarenta del Registro de Propiedades y anotada al número trescientos del Libro Repertorio, el veintiocho de marzo del año dos mil veintitrés, por la cual los comparecientes señores **TERENCIA DE JESUS GOMEZ FIGUEROA, JULIO GREGORIO GOMEZ FIGUEROA, LUIS FRANCISCO GOMEZ FIGUEROA, CLEOTILDE MERCEDES GOMEZ FIGUEROA, FILADELFIA DOLORES GOMEZ FIGUEROA; y, GREGORIA GLADYS GOMEZ FIGUEROA,** por sus propios y personales derechos, **INTEGRARON** y/o **UNIFICARON** los **TRES** lotes, esto es

Escaneado con CamScanner

LOS LOTES DE LAS SUPERFICIE DE QUINCE HECTAREAS OCHENTA AREAS, OCHO HECTAREAS TREINTA AREAS; y, CUATRO HECTAREAS SESENTA AREAS, por cuanto estos se encontraban juntos el uno hacia los otros, basado para el efecto al levantamiento Planimétrico, Informe de Linderos y Medidas; así como de la Resolución Administrativa número **CERO CERO SIETE – IU-GADMCM-MCHA-DOS MIL VEINTIDOS**, suscrito por la Alcaldesa y Secretario General del GAD Municipal, dichos inmuebles **forman un solo cuerpo**, descrito de la siguiente manera: **AREA DE LOTE UNIFICADO**, de la superficie total de **VEINTIOCHO HECTAREAS SETENTA AREAS**, ubicado en el Sector denominado "BARRO COLORADO", de la jurisdicción de la Parroquia y Cantón Mocache, Provincia de Los Ríos, circunscrito dentro de los siguientes linderos y medidas: **por el NORTE**: Con María Arreaga Ronquillo, en sesenta y cuatro metros veintiocho centímetros; **por el SUR**: Con Paulino Antonio Litardo Aspiazu, en veintitrés metros ochenta y cuatro centímetros, en veintiún metros noventa y dos centímetros, en veintitrés metros cero un centímetros, en veintitrés metros veintitrés centímetros, en veintitrés metros doce centímetros , en veintidós metros; **por el ESTE**: Con Herederos Coque Aguirre, en ochenta y dos metros setenta y un centímetros, en veintiocho metros cincuenta y dos centímetros, en cinco metros cuarenta y seis centímetros, en ciento tres metros setenta y dos centímetros, en cuarenta y cinco metros sesenta y un centímetros, en ciento noventa y un metros ochenta y ocho centímetros, Con

Escaneado con CamScanner

Terencia Gómez Figueroa, en noventa metros trece centimetros, en veintiocho metros cero un centimetros, en cincuenta metros veintinueve centimetros; Con Carretero Publico, en tres metros setenta y seis centimetros, en cincuenta y cuatro metros setenta y tres centimetros, en veintinueve metros cero un centimetros; Con cruce de Carretero Publico, en cuatro metros veintinueve centimetros; Con Ramon Gómez Candelario, en ciento cincuenta y ocho metros cero ocho centímetros, en cien metros treinta y dos centimetros; en ochenta y ocho metros veinte centimetros, en setenta y seis metros cero tres centímetros, en treinta y tres metros setenta y nueve centimeiros, en setenta y cinco metros setenta y ocho centimetros, en cincuenta metros veintiocho; Con Rodolfo Mendoza Litardo, en seis metros cuarenta y tres centimetros, en ciento nueve metros cero un centimetros, en ciento tres metros once centimetros, en ciento siete metros cero cuatro centímetros, en quinientos metros treinta y dos centimetros ; y, **por el OESTE**: Con Paulino Antonio Litardo Aspiazu, en treinta y siete metros cero dos centimetros, en doscientos sesenta y seis metros sesenta y tres centimetros, en doscientos setenta y tres metros ochenta y tres centimetros; Con camino priva do, en cincuenta y cuatro metros cero siete centímetros, en doscientos veintiséis metros noventa y cuatro centímetros, en trece metros noventa y tres centimetros; Con Ramon Gómez Candelario, en veintitrés metros cero un centimetros, en cincuenta y siete metros noventa y nueve centimetros, en cuarenta y dos metros ochenta y siete centimetros, en

Escaneado con CamScanner

cuarenta y tres metros cero cuatro centimetros, en cuarenta y un metros setenta y cinco centimetros, en ciento seis metros cuarenta y tres centimetros, en cuarenta y ocho metros cero cinco centimetros, en sesenta y nueve metros cincuenta y siete centimetros; Con cruce de Carretero Publico, en cuatro metros cuarenta y dos centimetros; Con Ramon Gómez Candelario, en cuarenta y nueve metros veintidós centimetros, en ochenta y ocho metros noventa y dos centimetros, en sesenta y tres metros cero cuatro centimetros, en treinta y cinco metros setenta centimetros, en cincuenta y dos metros cuarenta y dos centimetros, en diecinueve metros cuarenta y nueve centimetros; Con Herederos Arrecga Giler, en cincuenta y cuatro metros setenta y tres centimetros, en cuarenta y cuatro metros cero nueve centimetros, en cincuenta y tres metros treinta y nueve centimetros.- Quedando el lote número DOS, de la superficie de **SIETE HECTAREAS SIETE MIL DOSCIENTOS TRECE METROS CUADRADOS**, como un solo cuerpo independiente con los siguientes linderos y medidas; **por el NORTE**: Con Eloy Gómez Aguirre, en setenta y dos metros diez centimetros, en setenta y nueve metros cincuenta y cinco centimetros, en cuarenta metros ochenta centimetros; **por el SUR**: Con Julia Aguirre Franco, en cuarenta y seis metros diez centimetros; con Lorenzo Vera Alvarado, en cinco metros ochenta y tres centimetros, en treinta y seis metros, en sesenta y tres metros veinticuatro centimetros; con Teófilo Aguirre Franco, en sesenta y ocho metros catorce centimetros; **por el ESTE**: Con Verónica Castro Aguirre, en

Escaneado con CamScanner

ciento setenta y dos metros veintinueve centímetros;: con Daniel Junco Coello, en cuarenta y un metros treinta centímetros, en cincuenta y ocho metros veintidós centímetros; con Julia Figueroa Bajaña, en ochenta y ocho metros noventa y seis centímetros; y, **por el OESTE:** Con Marco Guillen Castro, en veintiocho metros ochenta y nueve centímetros, en cincuenta y cuatro metros veintitrés centímetros; con Guardarraya, en treinta y nueve metros cuarenta centímetros , en veintiocho metros veintiocho centímetros, en cuarenta y cuatro metros veinte centímetros, en diecinueve metros noventa y dos centímetros, en ciento tres metros diecisiete centímetros; con Alberto Litardo Cadena, en ciento seis metros treinta y siete centímetros.- f). Los comparecientes señores: **TERENCIA DE JESUS GOMEZ FIGUEROA, JULIO GREGORIO GOMEZ FIGUEROA, LUIS FRANCISCO GOMEZ FIGUEROA, CLEOTILDE MERCEDES GOMEZ FIGUEROA, FILADELFIA DOLORES GOMEZ FIGUEROA; y, GREGORIA GLADYS GOMEZ FIGUEROA,** por sus propios derechos, declaran además que previa junta de familia han acordado de manera voluntaria en realizar Partición Extrajudicial, y Adjudicación, que para tal efecto han obtenido la Aprobación e Informe Favorable del Gobierno Autónomo Descentralizado Municipal del Cantón Mocache, Mediante Resolución y/o Criterio Jurídico número **CERO DOS CINCO UNO – GADMCM – PSM – DOS MIL VEINTITRES,** suscrito por el Abogado Rafael Ballesteros Vaca, Procurador Síndico Municipal y la Certificación suscrita por el Abogado Alcy Raúl

Escaneado con CamScanner

Fajardo Arana, Secretario del Ilustre Concejo General del GAD Municipal, de fecha cinco de diciembre del año dos mil veintitrés, las mismas que se adjuntan como documentos habilitantes a la presente escritura pública, a fin de que sirva de sustento legal, en la forma que se detallara en las cláusulas siguientes.- **TERCERA: PARTICIÓN EXTRAJUDICIAL Y ADJUDICACIÓN.-** Consustanciados los antecedentes en las clausulas precedentes, los comparecientes señores: **TERENCIA DE JESUS GOMEZ FIGUEROA, JULIO GREGORIO GOMEZ FIGUEROA, LUIS FRANCISCO GOMEZ FIGUEROA, CLEOTILDE MERCEDES GOMEZ FIGUEROA, FILADELFIA DOLORES GOMEZ FIGUEROA; y,. GREGORIA GLADYS GOMEZ FIGUEROA,** por sus propios derechos, en forma libre y voluntaria; y, previa junta de familia han acordado en realizar la presente Partición Extrajudicial y Adjudicación de los Lotes de terrenos de las superficie de **VEINTIOCHO HECTAREAS SETENTA AREAS**, el mismo que se encuentra dividido en **SEIS LOTES**; y, el Lote de **SIETE HECTAREAS SIETE MIL DOSCIENTOS TRECE METROS CUADRADOS**, el mismo que se encuentra dividido en **TRES LOTES**, para lo cual han obtenido autorización del Gobierno Autónomo Descentralizado Municipal del Cantón Mocache, mediante Resolución y/o Criterio Jurídico número **CERO DOS CINCO UNO – GADMCM – PSM – DOS MIL VEINTITRES**, suscrito por el Abogado Rafael Ballesteros Vaca, Procurador Sindico Municipal y la Certificación suscrita por el Abogado Alcy Raúl Fajardo Arana, Secretario del Ilustre Concejo General del

Escaneado con CamScanner

GAD Municipal, de fecha cinco de diciembre del año dos mil veintitrés, las mismas que se adjuntan como documentos habilitantes a la presente escritura pública, a fin de que sirva de sustento legal, y adjudicario como se detalla a continuación: a). Para la heredera señora **TERENCIA DE JESUS GOMEZ FIGUEROA,** en pago de su cuota hereditaria, se les adjudica en propiedad, **DOS** Lotes descritos de la siguiente manera: Lote de terreno de la superficie de **DOS HECTAREAS CON CERO CERO NOVENTA Y SIETE METROS CUADRADOS**, el mismo que se fraccionado del lote de mayor cabida esto es del lote de **VEINTIOCHO HECTAREAS SETENTA AREAS**, ubicado en el sector Barro Colorado, jurisdicción de la Parroquia y Cantón Mocache, Provincia de Los Ríos, circunscrito dentro de los siguientes linderos y medidas; **por el NORTE**: Con Gómez Figueroa Julio Gregorio con treinta y seis metros dieciséis centímetros; **por el SUR**: Con Litardo Aspiazu Paulino Antonio en veintitrés metros ochenta y cuatro centímetros; **por el ESTE**: Con Mendoza Aguirre Rodolfo en ciento tres metros con once centímetros; ciento siete metros cero cuatro centímetros; quinientos metros con treinta y dos centímetros; y, **por el OESTE**: Con Gómez Figueroa Julio Gregorio en cuatrocientos ochenta y cinco metros con ochenta y seis centímetros; doscientos diez metros con ochenta y un centímetros.- Y Lote de terreno de la superficie de **DOS HECTAREAS CON CERO OCHOCIENTOS CUARENTA Y UN METROS CUADRADOS**, el mismo que se fraccionado del lote de mayor cabida, esto es del lote de

Escaneado con CamScanner

VEINTIOCHO HECTAREAS SETENTA AREAS, ubicado en el sector Barro Colorado, jurisdicción de la Parroquia y Cantón Mocache, Provincia de Los Ríos, circunscrito dentro de los siguientes linderos y medidas; **por el NORTE**: Con Herederos Coque Aguirre en setenta y seis metros veintocho centímetros; **por el SUR**: Con Gómez Figueroa Terencia de Jesús en noventa y cuatro metros con dieciocho centímetros; **por el ESTE**: Con Herederos Coque Aguirre en doscientos treinta y siete metros con cuarenta y ocho centímetros; y, **por el OESTE**: Con Gómez Figueroa Cleotilde en doscientos noventa y siete metros sesenta y tres centímetros.-Se deja expresa constancia que a la presente Adjudicación se le establece un avalúo comercial de CINCO MIL CIENTO NOVENTA Y NUEVE CON DOS DOLARES AMERICANOS, cantidad con la que la Adjudicataria se encuentra satisfecha, adicionalmente se le adjudica en propiedad conjuntamente con otro de los herederos otro lote, por lo que deja expresa constancia que se han tributados los impuestos de alcabalas, y sus adicionales de ley, referente al exceso de adjudicación que se hace mediante esta escritura pública.- *b) Para el* heredero señor JULIO GREGORIO GOMEZ FIGUEROA, en pago de su cuota hereditaria, se le adjudica en propiedad, **DOS** Lote de terreno, descritos de la siguiente manera: Lote de la superficie de **UNA HECTAREA CON SIETE MIL OCHOCIENTOS NOVENTA Y OCHO METROS CUADRADOS**, el mismo que se fraccionado del lote de mayor cabida, esto es del lote de **VEINTIOCHO HECTAREAS SETENTA AREAS**, ubicado en el sector Barro

Escaneado con CamScanner

Colorado, jurisdicción de la Parroquia y Cantón Mocache, Provincia de Los Ríos, circunscrito dentro de los siguientes linderos y medidas; **por el NORTE**: Con Gómez Figueroa Julio en treinta metros con quince centímetros; **por el SUR**: Con Litardo Aspiazu Paulino Antonio, en veintiún metros con noventa y dos centímetros; **por el ESTE**: Con Gómez Figueroa Terencia en doscientos diez metros con ochenta y un centímetros; cuatrocientos ochenta y cinco metros con ochenta y siete centímetros; y, **por el OESTE**: Con Gómez Figueroa Luis en cuatrocientos treinta y ocho metros con cincuenta y cuatro centímetros; doscientos cuarenta y cuatro metros con sesenta y nueve centímetros.- **Y Lote de terreno,** de la superficie de DOS HECTAREAS CON CUATRO MIL CIENTO VEINTICUATRO METROS CUADRADOS, el mismo que se fraccionado del lote de mayor cabida, esto es del lote de VEINTIOCHO HECTAREAS SETENTA AREAS, ubicado en el sector Barro Colorado, jurisdicción de la Parroquia y Cantón Mocache, Provincia de Los Ríos, circunscrito dentro de los siguientes linderos y medidas; **por el NORTE**: Con Gómez Figueroa Gregoria en doscientos diez metros con sesenta y cuatro centímetros; por el SUR: Con Gómez Figueroa Terencia de Jesús en treinta y seis metros con dieciséis centímetros, con Gómez Figueroa Julio en treinta metros con quince centímetros, con Gómez Figueroa Luis en treinta y cinco metros con cincuenta y dos centímetros, con Gómez Figueroa Cleotilde en treinta y cinco metros con ochenta y cinco centímetros, con Gómez Figueroa Filadelfia en cuarenta y un metros con noventa y

Escaneado con CamScanner

nueve centímetros, con Gómez Figueroa Gregoria en treinta y cuatro metros noventa y ocho centímetros; **por el ESTE**: Con Gómez Candelario Ramon en ochenta y cinco metros cuarenta y siete centímetros; y, **por el OESTE**: Con Litardo Aspiazu Paulino Antonio en ciento setenta y ocho metros con veintiséis centímetros.- Se deja expresa constancia que a la presente Adjudicación se le establece un avalúo comercial de **CINCO MIL TRESCIENTOS CINCUENTA Y NUEVE 35/100 DOLARES AMERICANOS,** cantidad con el Adjudicatario se encuentran satisfechos.- Adicionalmente se le adjudica en propiedad conjuntamente con otro de los herederos otro lote, por lo que deja expresa constancia que se han tributados los impuestos de alcabalas, y sus adicionales de ley, referente al exceso de adjudicación que se hace mediante esta escritura pública.- **c).-** Para la heredera señora **CLEOTILDE MERCEDES GOMEZ FIGUEROA**, se le adjudica en propiedad, **DOS** lotes de terreno, descritos de la siguiente manera: **LOTE**, de la superficie de **UNA HECTAREAS CON OCHO MIL TRESCIENTOS CUARENTA Y SIETE METROS CUADRADOS**, el mismo que se fraccionado del lote de misma cabida, esto es del lote de la superficie VEINTIOCHO HECTAREAS SETENTA AREAS, ubicado en el sector Barro Colorado, jurisdicción de la Parroquia y Cantón Mocache, Provincia de Los Ríos, circunscrito dentro de los siguientes linderos y medidas; **por el NORTE**: Con Gómez Figueroa Julio en treinta y cinco metros con ochenta y cinco centímetros; **por el SUR**: Con Litardo Aspiazu Paulino Antonio en veinticuatro metros con veintitrés centímetros; **por**

Escaneado con CamScanner

el ESTE: Con Gómez Figueroa Luis en trescientos veintidós metros con dieciocho centímetros; trescientos cuarenta y tres metros setenta y siete centímetros; y, **por el OESTE**: Con Gómez Figueroa Filadelfia en trescientos veintisiete metros con sesenta y cuatro centímetros; trescientos nueve metros con cincuenta y cinco centímetros.- Y **Lote de terreno,** de la superficie de **SEIS HECTAREAS CON SIETE MIL VEINTE METROS CUADRADOS**, el mismo que se fraccionado del lote de mayor cabida, esto es del lote de la superficie **VEINTIOCHO HECTAREAS SETENTA AREAS**, ubicado en el sector Barro Colorado, jurisdicción de la Parroquia y Cantón Mocache, Provincia de Los Ríos, circunscrito dentro de los siguientes linderos y medidas: **por el NORTE**: Con Herederos Arreaga Giler en cincuenta y cuatro metros sesenta y tres centímetros; cuarenta y cuatro metros cetro nueve centímetros; cincuenta y tres metros treinta y nueve centímetros, con María Arreaga Ronquillo, en sesenta y cuatro metros con veintiocho centímetros, con Herederos Coque Aguirre en treinta y tres metros con treinta y tres centímetros; cuarenta y nueve metros con treinta y nueve centímetros; con veintiocho metros cincuenta y dos centímetros; treinta y dos metros setenta centímetros; **por el SUR**: Con Gregoria Gómez Figueroa en doscientos treinta y cinco metros con noventa y cinco centímetros; **por el ESTE**: Con Terencia Gómez Figueroa en doscientos noventa y siete metros con sesenta y tres centímetros, con Herederos Gómez Figueroa en veintidós metros con cincuenta y siete centímetros; cincuenta metros con veintinueve centímetros,

Escaneado con CamScanner

con Guardarraya Publica en tres metros setenta y cinco centimetros; cincuenta y cuatro metros setenta y tres centimetros, veintinueve metros un centímetros, con Cruce de Guardarraya Publica en cuatro metros con veintinueve centimetros, con Ramon Gómez en ciento cincuenta y ocho metros con ocho centimetros; con cien metros treinta y dos centimetros; ochenta y ocho metros con dos centimetros; veintinueve metros treinta y nueve centimetros; y, por el **OESTE**: Con Ramon Gómez Candelario en ochenta y cinco con sesenta y tres centimetros; cuarenta y ocho con cinco centimetros; sesenta y nueve metros con sesenta y cuatro centimetros, con Cruce de Guardarraya Publica en cuatro metros con cuarenta y dos centimetros, con Ramon Gómez Candelario en cuarenta y nueve metros con veintinueve centimetros; ochenta y ocho metros con noventa y dos centimetros; noventa y ocho metros con setenta y cuatro centimetros; cincuenta y dos metros con cuarenta y dos centimetros; diecinueve metros con cuarenta y siete centimetros.- Se deja expresa constancia que a la presente Adjudicación se le establece un avaluó comercial de **DIEZ MIL OCHOCIENTOS SESENTA Y SIETE PESOS DOLARES AMERICANOS,** cantidad con la Adjudicataria se encuentra satisfecha.- adicionalmente se le adjudica en propiedad conjuntamente con otro de los herederos otro lote, por lo que deja expresa constancia que se han tributados los impuestos de alcabalas, y sus adicionales de ley, referente al exceso de adjudicación que se hace mediante esta escritura pública.- **d).** Para la heredera **GREGORIA GLADYS GOMEZ**

Escaneado con CamScanner

FIGUEROA, se le adjudica en propiedad, **DOS** lote de terrenos, descritos de la siguiente manera: **LOTE** de terreno, de la superficie de **UNA HECTAREA CON SEIS MIL CINCUENTA Y TRES METROS CUADRADOS**, el mismo que se fraccionado del lote de mayor cabida, esto es del lote de la superficie **VEINTIOCHO HECTAREAS SETENTA AREAS**, ubicado en el sector Barro Colorado, jurisdicción de la Parroquia y Cantón Mocache, Provincia de Los Ríos, circunscrito dentro de los siguientes linderos y medidas; **por el NORTE**: Con Gómez Figueroa Julio en treinta y cuatro metros con noventa y ocho centímetros; **por el SUR**: Con Litardo Aspiazu Paulino Antonio en veintidós metros; **por el ESTE**: Con Gómez Figueroa Cleotilde en doscientos cuarenta y cuatro metros con ochenta y un centímetros; trescientos dieciséis metros con doce centímetros; y, **por el OESTE**: Con Litardo Aspiazu Paulino Antonio en trescientos tres metros con sesenta y cinco centímetros; doscientos sesenta y tres con ochenta y tres centímetros.- Y Lote de terreno, de la superficie de **SEIS HECTAREAS CON SIETE MIL VEINTE METROS CUADRADOS**, el mismo que se fraccionado del lote de mayor cabida, esto es del lote de la superficie **VEINTIOCHO HECTAREAS SETENTA AREAS**, ubicado en el sector Barro Colorado, jurisdicción de la Parroquia y Cantón Mocache, Provincia de Los Ríos, circunscrito dentro de los siguientes linderos y medidas; **por el NORTE**: Con Gómez Figueroa Cleotilde, en doscientos treinta y cinco metros con noventa y cinco centímetros; **por el SUR**: Con Gómez Figueroa Julio en doscientos diez metros con sesenta

Escaneado con CamScanner

y cuatro centímetros; **por el ESTE**: Con Gómez Candelario Ramon en cuarenta y seis metros con sesenta y cuatro centímetros; treinta y tres metros con setenta y nueve centímetros; setenta y cinco metros con setenta y ocho centímetros; catorce metros con catorce centímetros; seis metros con cuarenta y tres centímetros; veintitrés metros con cincuenta y tres centímetros; y, **por el OESTE**: Con Gómez Ramon en ciento dos metros con setenta y tres centímetros; trece metros con noventa y tres centímetros; veintitrés metros con un centímetros; con treinta y seis metros con sesenta y nueve centímetros; veintiún metros con treinta centímetros; cuarenta y dos metros con ochenta y siete centímetros; cuarenta y tres metros con cuatro centímetros; cuarenta y un metros con setenta y cinco centímetros; veinte metros con ochenta centímetros.- Se deja expresa constancia que a la presente Adjudicación se le establece un avaluó comercial de **DIEZ MIL QUINIENTOS NOVENTA Y CUATRO 87/100 DOLARES AMERICANOS,** cantidad con la que la Adjudicataria se encuentra satisfecha.- Adicionalmente se le adjudica en propiedad conjuntamente con otro de los herederos otro lote, por lo que deja expresa constancia que se han tributados los impuestos de alcabalas, y sus adicionales de ley, referente al exceso de adjudicación que se hace mediante esta escritura pública.- **e).** Para la heredera **FILADELFIA DOLORES GOMEZ FIGUEROA**, se le adjudica en propiedad Un lote de terreno, de la superficie de **UNA HECTAREA CON SIETE MIL CUATROCIENTOS TREINTA Y TRES METROS CUADRADOS**, el mismo que

Escaneado con CamScanner

se fraccionado del lote de mayor cabida, esto es del lote de la superficie **VEINTIOCHO HECTAREAS SETENTA AREAS,** ubicado en el sector Barro Colorado, jurisdicción de la Parroquia y Cantón Mocache, Provincia de Los Ríos, circunscrito dentro de los siguientes linderos y medidas; **por** el **NORTE**: Con Gómez Figueroa Julio en cuarenta y un metros con noventa y nueve centímetros; **por el SUR**: Con Litardo Aspiazu Paulino Antonio, en veintitrés metros con doce centímetros; **por el ESTE**: Con Gómez Figueroa Cleotilde en trescientos nueve metros con cincuenta y cinco centímetros; trescientos veintisiete metros con sesenta y cuatro centímetros; y, **por el OESTE**: Con Gómez Figueroa Gregoria en trescientos diecisiete metros con doce centímetros; doscientos ochenta y cuatro con ochenta y un centímetros.- Se deja expresa constancia que a la presente Adjudicación se le establece un avaluó comercial de **DOS MIL DOSCIENTOS VEINTITRES 35/100 DOLARES AMERICANOS,** cantidad con la que la Adjudicataria se encuentra satisfecha.- Adicionalmente se le adjudica en propiedad conjuntamente con otro de los herederos otro lote, por lo que deja expresa constancia que se NO TIENE **exceso de adjudicación, por lo que** no se debe de pagar alcabalas y sus adicionales.- f). Para el heredero **LUIS FRANCISCO GOMEZ FIGUEROA**, se le adjudica en propiedad, Un lote de terreno, de la superficie de **UNA HECTAREA CON SIETE MIL NOVECIENTOS SETENTA Y CINCO METROS CUADRADOS**, el mismo que se fraccionado del lote de mayor cabida, esto es del lote de la

Escaneado con CamScanner

superficie **VEINTIOCHO HECTAREAS SETENTA AREAS**, ubicado en el sector Barro Colorado, jurisdicción de la Parroquia y Cantón Mocache, Provincia de Los Ríos, circunscrito dentro de los siguientes linderos y medidas; **por el NORTE: Con** Gómez Figueroa Julio Gregorio en treinta y cinco metros con cincuenta y dos centímetros; **por el SUR:** Con Lilardo Aspiazu Paulino Antonio, en veintitrés metros con un centímetros; **por el ESTE:** Con Julio Gómez Figueroa en doscientos cuarenta y cuatro metros con setenta y nueve centímetros; cuatrocientos treinta y ocho metros con cincuenta y cinco centímetros; y, **por el OESTE:** Con Cleotilde Gómez Figueroa en trescientos cuarenta y tres metros con setenta y siete centímetros; trescientos veintidós metros con dieciocho centímetros.- Del lote de terreno fraccionado de mayor cabida existe un Área de Guardarraya Pública, de cero punto cero ciento noventa y dos metros cuadrados.- Se deja expresa constancia que a la presente Adjudicación se le establece un avaluó comercial de **DOS MIL DOSCIENTOS NOVENTA Y DOS 47/100 DOLARES AMERICANOS**, cantidad con la que el Adjudicatario se encuentra satisfecho.- Adicionalmente se le adjudica en propiedad conjuntamente con otro de los herederos otro lote, por lo que deja expresa constancia que se **NO TIENE** exceso de adjudicación, por lo que no se debe de pagar alcabalas y sus adicionales.- **Y del Lote de terreno SIETE HECTAREAS SIETE MIL DOSCIENTOS TRECE METROS CUADRADOS**, el mismo que se encuentra dividido en **TRES LOTES, y se Adjudica de la siguiente manera: a).** Para los

Escaneado con CamScanner

herederos señores: **TERENCIA DE JESUS GOMEZ FIGUEROA; y, JULIO GREGORIO GOMEZ FIGUEROA,** se le adjudica en propiedad, Un lote de terreno, de la superficie de **CUATRO HECTAREA CON MIL NOVECIENTOS CUARENTA Y UN METROS CUADRADOS**, el mismo que se fraccionado del lote de mayor cabida, esto es del lote de la superficie **SIETE HECTAREAS CON SIETE MIL DOSCIENTOS TRECE METROS CUADRADOS**, ubicado en el sector Barro Colorado, jurisdicción de la Parroquia y Cantón Mocache, Provincia de Los Ríos, circunscrito dentro de los siguientes linderos y medidas; **por el NORTE**: Con Gómez Aguirre Eloy en setenta y dos metros con once centímetros; setenta y nueve metros con cincuenta y un centímetros; cuarenta metros con ochenta centímetros; **por el SUR**: Con Luis Francisco Gómez Figueroa y Cleotilde Mercedes Gómez Figueroa en ciento ochenta y cuatro metros con noventa centímetros; **por el ESTE**: Con Castro Aguirre Verónica en ciento setenta y dos metros con veintinueve centímetros, con Junco Coello Daniel en cuarenta y un metros con treinta centímetros; y, **por el OESTE**: Con Guardamaya frente a Litardo Cadena Alberto en veintiún metros con ochenta y un centímetros; diecinueve metros con noventa y dos centímetros; ciento tres metros con diecisiete centímetros; Con Litardo Cadena Alberto en ciento seis metros con treinta y siete centímetros.- Se deja expresa constancia que a la presente Adjudicación se le establece un avaluó comercial de **QUINCE MIL QUINIENTOS VEINTIDOS 95/100 DOLARES AMERICANOS**, cantidad con los que el

Escaneado con CamScanner

Adjudicatarios se encuentran satisfechos.- **b).** Para los señores: **LUIS FRANCISCO GOMEZ FIGUEROA; y, CLEOTILDE MERCEDES GOMEZ FIGUEROA,** se les adjudica en propiedad Un lote de terreno, de la superficie de **UNA HECTAREA CON CUATRO MIL CIENTO SEIS METROS CUADRADOS**, el mismo que se fraccionado del lote de mayor cabida, esto es del lote de la superficie **SIETE HECTAREAS CON SIETE MIL DOSCIENTOS TRECE METROS CUADRADOS**, ubicado en el sector Barro Colorado, jurisdicción de la Parroquia y Cantón Mocache, Provincia de Los Rios, circunscrito dentro de los siguientes linderos y medidas; **por el NORTE**: Con Torencia de Jesús Gómez Figueroa y Julio Gregorio Gómez Figueroa en ciento ochenta y cuatro metros con noventa centímetros; por el **SUR**: Con Filadelfia Gómez Figueroa y Gregoria Gladys Gómez Figueroa en doscientos cuarenta y un metros con setenta centimetros; **por el ESTE**: Con Junco Coello Daniel en cincuenta y ocho metros con veintidós centímetros; y, **por el OESTE**: Con Guillen Castro Marco en trece metros cincuenta y ocho centimetros, con guardarraya frente a Lilardo Cadena Alberto en treinta y nueve metros con cuarenta centímetros; veintiocho metros veintiocho centimetros; veintidós metros con treinta y nueve centímetros.- Se deja expresa constancia que a la presente Adjudicación se le establece un avaluó comercial de **CINCO MIL DOSCIENTOS VEINTE 83/100 DOLARES AMERICANOS**, cantidad con los que el Adjudicatarios se encuentran satisfechos.- **c).** Y finalmente para los herederos:

Escaneado con CamScanner

FILADELFIA DOLORES GOMEZ FIGUEROA; y, GREGORIA GLADYS GOMEZ FIGUEROA, se les adjudica en propiedad Un lote de terreno, de la superficie de **DOS HECTAREAS CON MIL CIENTO SESENTA Y SEIS METROS CUADRADOS,** el mismo que se fraccionado del lote de mayor cabida, esto es del lote de la superficie **SIETE HECTAREAS CON SIETE MIL DOSCIENTOS TRECE METROS CUADRADOS,** ubicado en el sector Barro Colorado, jurisdicción de la Parroquia y Cantón Mocache, Provincia de Los Ríos, circunscrito dentro de los siguientes linderos y medidas; **por el NORTE:** Con Luis Francisco Gómez Figueroa y Cleotilde Mercedes Gómez Figueroa en doscientos cuarenta y un metros con setenta centímetros; **por el SUR:** Con Aguirre Franco Julia en cuarenta y seis metros con diez centímetros, Con Vera Alvarado Lorenzo en cinco metros con ochenta y tres centímetros; treinta y seis metros con cero centímetros; sesenta y tres metros con veinticuatro centímetros, Con Aguirre Franco Teófilo en sesenta y ocho metros con catorce centímetros; **por el ESTE:** Con Figueroa Bajaña Julia en ochenta y ocho metros con noventa y seis centímetros; y, **por el OESTE:** Con Guillen Castro Marco en sesenta y cuatro metros con cincuenta y un centímetros; cuarenta metros con sesenta y cinco centímetros.- Se deja expresa constancia que a la presente Adjudicación se le establece un avaluó comercial de **SIETE MIL OCHOCIENTOS TREINTA Y TRES 83/100 DOLARES AMERICANOS,** cantidad con los que el Adjudicatarios se encuentran satisfechos.- **CUARTA:**

Escaneado con CamScanner

ACEPTACIÓN DE LA PARTICIÓN EXTRAJUDICIAL Y ADJUDICACIÓN.- Por su parte los adjudicatarios señores: **TERENCIA DE JESUS GOMEZ FIGUEROA, JULIO GREGORIO GOMEZ FIGUEROA, LUIS FRANCISCO GOMEZ FIGUEROA, CLEOTILDE MERCEDES GOMEZ FIGUEROA, FILADELFIA DOLORES GOMEZ FIGUEROA; y, GREGORIA GLADYS GOMEZ FIGUEROA**, por sus propios derechos, aceptan la presente adjudicación, por ser hecha a favor, y por convenir a sus propios intereses, agradeciéndose entre sí, por este gesto de buena voluntad que han tenido, en adjudicarse los lotes de terreno.- **QUINTA: AVALUO DE PARTICION EXTRAJUDICIAL Y ADJUDICACIÓN PARCIAL.-** El Avalúo de la presente partición es de **SESENTA Y CINCO MIL CIENTO TREINTA Y CUATRO 16/100 DOLARES AMERICANOS**, conforme a los Certificados de Avalúos emitidos por el Departamento de Avalúos y Catastro del Gobierno Autónomo Descentralizado Municipal del Cantón Mocache, que se agregan como documentos habilitantes.- **SEXTA.- GASTOS.-** Todos los gastos que ocasionen la celebración de esta escritura pública, e inscripción en el Registro de la Propiedad del cantón Mocache, serán de cuenta y cargo de los adjudicatarios, en partes equitativas e iguales.- **SEPTIMA.- AUTORIZACIÓN PARA INSCRIBIR.-** Cualquiera de las partes intervinientes en este contrato, por si o por interpuesta persona podrán solicitar la inscripción de la presente escritura pública en el Registro de la Propiedad correspondiente conforme lo establecen los Artículos treinta y

Escaneado con CamScanner

MOCACHE ALCALDÍA

COMPROBANTE DE INGRESO A CAJA

FECHA DE EMISIÓN	FECHA RECAUDACIÓN	
15/12/2023	15/12/2023 9 38 AM	0329410

CONTRIBUYENTE	CÉDULA - RUC	COD. CATASTRAL
GOMEZ FIGUEROA TERENCIA DE JESUS	0909786535	

CONCEPTO

***** ALCABALAS ***** 2023

RUBRO	VALOR
IMPUESTO A LAS ALCABALAS	$ 21,05
JUNTA DE BENEFICENCIA	$ 6,31
TASA GENERAL DE EMISION	$ 1,35
CONSEJO PROV.	$ 0,21
PLUSVALIA	$ 0,00

OBSERVACIONES

ALCABALAS PARTICIÓN EXTRAJUDICIAL Y ADJUDICACIÓN DE LOTES DE 28 70 HAS , Y 7.7213 HAS SECTOR BARRO COLORADO , OTORGA HOROS GOMEZ FIGUEROA , A FAVOR TERENCIA GOMEZ FIGUEROA CON CUANTIA USD 65.134.18 DIFERENCIA

SUBTOTALES	
EFECTIVO	$ 28,92
NOTA DE	$ 0,00
CHEQUE	$ 0,00
TARJETA DE	$ 0,00
TRANSFERENCIA	$ 0,00
Intereses	$ 0,00
Descuentos	$ 0,00
Recargos	$ 0,00
TOTAL RECIBIDO	$28,92

15 DIC 2023

!ENT-295028 RECAUDACIÓN MUNICIPAL VEdison

MOCACHE ALCALDÍA

COMPROBANTE DE INGRESO A CAJA

FECHA DE EMISIÓN	FECHA RECAUDACIÓN	
15/12/2023	15/12/2023 9 38 AM	0329408

CONTRIBUYENTE	CÉDULA - RUC	COD. CATASTRAL
GOMEZ FIGUEROA GREGORIA GLADYS	1203580491	

CONCEPTO

***** ALCABALAS ***** 2023

RUBRO	VALOR
IMPUESTO A LAS ALCABALAS	$ 36,56
JUNTA DE BENEFICENCIA	$ 10,97
TASA GENERAL DE EMISION	$ 1,35
CONSEJO PROV.	$ 0,37
PLUSVALIA	$ 0,00

OBSERVACIONES

ALCABALAS PARTICIÓN EXTRAJUDICIAL Y ADJUDICACIÓN DE LOTES DE 28 70 HAS , Y 7.7213 HAS SECTOR BARRO COLORADO , OTORGA HOROS GOMEZ FIGUEROA , A FAVOR GREGORIA GOMEZ FIGUEROA CON CUANTIA USD 65.134.18 DIFERENCIA

SUBTOTALES	
EFECTIVO	$ 49,25
NOTA DE	$ 0,00
CHEQUE	$ 0,00
TARJETA DE	$ 0,00
TRANSFERENCIA	$ 0,00
Intereses	$ 0,00
Descuentos	$ 0,00
Recargos	$ 0,00
TOTAL RECIBIDO	$ 49,25

15 DIC 2023

!ENT-295028 RECAUDACIÓN MUNICIPAL VEdison

MOCACHE ALCALDÍA

COMPROBANTE DE INGRESO A CAJA

FECHA DE EMISIÓN	FECHA RECAUDACIÓN	
15/12/2023	15/12/2023 9 37 AM	0329407

CONTRIBUYENTE	CÉDULA - RUC	COD. CATASTRAL
GOMEZ FIGUEROA CLEOTILDE MERCEDES	0912753993	

CONCEPTO

***** ALCABALAS ***** 2023

RUBRO	VALOR
IMPUESTO A LAS ALCABALAS	$ 26,42
JUNTA DE BENEFICENCIA	$ 7,93
TASA GENERAL DE EMISION	$ 1,35
CONSEJO PROV.	$ 0,26
PLUSVALIA	$ 0,00

OBSERVACIONES

ALCABALAS PARTICIÓN EXTRAJUDICIAL Y ADJUDICACIÓN DE LOTES DE 28 70 HAS , Y 7.7213 HAS SECTOR BARRO COLORADO , OTORGA HOROS GOMEZ FIGUEROA , A FAVOR CLEOTILDE GOMEZ FIGUEROA CON CUANTIA USD 65.134.18 DIFERENCIA

SUBTOTALES	
EFECTIVO	$ 35,96
NOTA DE	$ 0,00
CHEQUE	$ 0,00
TARJETA DE	$ 0,00
TRANSFERENCIA	$ 0,00
Intereses	$ 0,00
Descuentos	$ 0,00
Recargos	$ 0,00
TOTAL RECIBIDO	$ 35,96

Escaneado con CamScanner

MOCACHE ALCALDÍA

COMPROBANTE DE INGRESO A CAJA

FECHA DE EMISIÓN	FECHA RECAUDACIÓN	
15/12/2023	15/12/2023 9:38 AM	0329409

CONTRIBUYENTE	CÉDULA - RUC	COD. CATASTRAL
GOMEZ FIGUEROA JULIO GREGORIO	0912744240	

CONCEPTO

***** ALCABALAS ***** 2023

RUBRO	VALOR
IMPUESTO A LAS ALCABALAS	$ 22,65
JUNTA DE BENEFICENCIA	$ 6,80
TASA GENERAL DE EMISION	$ 1,35
CONSEJO PROV.	$ 0,23
PLUSVALIA	$ 0,00

OBSERVACIONES

ALCABALAS PARTICIÓN EXTRAJUDICIAL Y ADJUDICACIÓN DE LOTES DE 28.70 HAS. Y 7,7213 HAS. SECTOR BARRO COLORADO , OTORGA HDROS GOMEZ FIGUEROA A FAVOR JULIO GOMEZ FIGUEROA CON CUANTIA USD 65.134,18 DIFERENCIA DE

SUBTOTALES

EFECTIVO	$ 31,03
NOTA DE	$ 0,00
CHEQUE	$ 0,00
TARJETA DE	$ 0,00
TRANSFERENCIA	$ 0,00
[illegible]	$ 0,00
[illegible]	$ 0,00
Recargos	$ 0,00
TOTAL RECIBIDO	$ 31,03

CAD. MUNICIPAL DEL CANTÓN MOCACHE 15 DIC 2023 TESORERÍA CANCELADO

RENT 295027

RECAUDACIÓN MUNICIPAL

VEdison

MOCACHE ALCALDÍA

COMPROBANTE DE INGRESO A CAJA

FECHA DE EMISIÓN	FECHA RECAUDACIÓN	
11/12/2023	11/12/2023 4:03 PM	0328933

CONTRIBUYENTE	CÉDULA - RUC	COD. CATASTRAL
GOMEZ FIGUEROA TERENCIA DE JESUS	0909786535	

CONCEPTO

***** CERTIFICADO DE NO ADEUDAR *****

Area Terreno

SE CERTIFICA DE QUE NO ES DEUDOR(A) AL GOBIERNO AUTONOMO DESCENTRALIZADO MUNICIPAL DEL CANTÓN MOCACHE , COMO ESTABLECE EL COA DISPOSICIONES TRANSITORIAS OCTAVA Y ART. 4 DE LA ORDENANZA QUE ESTABLECE LA TASA POR SERVICIO TECNICO ADMINISTRATIVO MEMORANDUN 20-DFM DEL 24/6/19

ESTE CERTIFICADO TIENE VALIDEZ POR 30 DIAS A PARTIR DEL DIA DE EMISION.

SUBTOTALES

TASA	$ 1,35
TOTAL RECIBIDO	$ 1,35

CAD. MUNICIPAL DEL CANTÓN MOCACHE 14 DIC 2023 TESORERÍA CANCELADO

34 : 29-571

RECAUDACIÓN MUNICIPAL

VEdison

MOCACHE ALCALDÍA

COMPROBANTE DE INGRESO A CAJA

FECHA DE EMISIÓN	FECHA RECAUDACIÓN	
11/12/2023	11/12/2023 4:01 PM	0328928

CONTRIBUYENTE	CÉDULA - RUC	COD. CATASTRAL
GOMEZ FIGUEROA GREGORIA GLADYS	1203580491	

CONCEPTO

***** CERTIFICADO DE NO ADEUDAR *****

Area Terreno

SE CERTIFICA DE QUE NO ES DEUDOR(A) AL GOBIERNO AUTONOMO DESCENTRALIZADO MUNICIPAL DEL CANTÓN MOCACHE , COMO ESTABLECE EL COA DISPOSICIONES TRANSITORIAS OCTAVA Y ART. 4 DE LA ORDENANZA QUE ESTABLECE LA TASA POR SERVICIO TECNICO ADMINISTRATIVO MEMORANDUN 20-DFM DEL 24/6/19

ESTE CERTIFICADO TIENE VALIDEZ POR 30 DÍAS A PARTIR DEL DÍA DE EMISIÓN.

SUBTOTALES

TASA	$ 1,35
TOTAL RECIBIDO	$ 1,35

CAD. MUNICIPAL DEL CANTÓN MOCACHE 11 DIC 2023 TESORERÍA CANCELADO

5+ : 29-568

Escaneado con CamScanner

MOCACHE ALCALDÍA

COMPROBANTE DE INGRESO A CAJA

FECHA DE EMISIÓN	FECHA RECAUDACIÓN	
11/12/2023	11/12/2023 4:02 PM	0328929

CONTRIBUYENTE	CÉDULA - RUC	COD. CATASTRAL
GOMEZ FIGUEROA FILADELFIA DOLORES	0912754003	

CONCEPTO

***** CERTIFICADO DE NO ADEUDAR *****

Area Terreno

SE CERTIFICA DE QUE NO ES DEUDOR(A) AL GOBIERNO AUTONOMO DESCENTRALIZADO MUNICIPAL DEL CANTÓN MOCACHE , COMO ESTABLECE EL COA DISPOSICIONES TRANSITORIAS OCTAVA Y ART. 4 DE LA ORDENANZA QUE ESTABLECE LA TASA POR SERVICIO TÉCNICO ADMINISTRATIVO MEMORANDUN 20-DFM DEL 24/6/19

ESTE CERTIFICADO TIENE VALIDEZ POR 30 DÍAS A PARTIR DEL DÍA DE EMISIÓN.

SUBTOTALES

TASA	$ 1,35
TOTAL RECIBIDO	$ 1,35

11 DIC 2023

Tel: 29-807

RECAUDACIÓN MUNICIPAL

VEdison

MOCACHE ALCALDÍA

COMPROBANTE DE INGRESO A CAJA

FECHA DE EMISIÓN	FECHA RECAUDACIÓN	
11/12/2023	11/12/2023 4:02 PM	0328930

CONTRIBUYENTE	CÉDULA - RUC	COD. CATASTRAL
GOMEZ FIGUEROA CLEOTILDE MERCEDES	0912753993	

CONCEPTO

***** CERTIFICADO DE NO ADEUDAR *****

Area Terreno

SE CERTIFICA DE QUE NO ES DEUDOR(A) AL GOBIERNO AUTONOMO DESCENTRALIZADO MUNICIPAL DEL CANTÓN MOCACHE , COMO ESTABLECE EL COA DISPOSICIONES TRANSITORIAS OCTAVA Y ART. 4 DE LA ORDENANZA QUE ESTABLECE LA TASA POR SERVICIO TÉCNICO ADMINISTRATIVO MEMORANDUN 20-DFM DEL 24/6/19

ESTE CERTIFICADO TIENE VALIDEZ POR 30 DÍAS A PARTIR DEL DÍA DE EMISIÓN.

SUBTOTALES

TASA	$ 1,35
TOTAL RECIBIDO	$ 1,35

11 DIC 2023

Tel: 29-808

RECAUDACIÓN MUNICIPAL

VEdison

NOTARIA PROTOCOLO DEL CARLOS MENDOZA GARCIA MSC NOTARIO TITULAR

ESPACIO EN BLANCO

Escaneado con CamScanner

MOCACHE ALCALDIA

COMPROBANTE DE INGRESO A CAJA

FECHA DE EMISIÓN	FECHA RECAUDACIÓN	
11/12/2023	11/12/2023 4.02 PM	0328931

CONTRIBUYENTE	CÉDULA - RUC	COD. CATASTRAL
GOMEZ FIGUEROA LUIS FRANCISCO	1302559000	

CONCEPTO

******* CERTIFICADO DE NO ADEUDAR *******

Area Terreno:

SE CERTIFICA DE QUE NO ES DEUDOR(A) AL GOBIERNO AUTONOMO DESCENTRALIZADO MUNICIPAL DEL CANTON MOCACHE , COMO ESTABLECE EL COA DISPOSICIONES TRANSITORIAS OCTAVA Y ART. 4 DE LA ORDENANZA QUE ESTABLECE LA TASA POR SERVICIO TÉCNICO ADMINISTRATIVO MEMORANDUN 20-DFM DEL 24/6/19

ESTE CERTIFICADO TIENE VALIDEZ POR 30 DIAS A PARTIR DEL DÍA DE EMISIÓN.

SUBTOTALES	
TASA	$ 1,35
TOTAL RECIBIDO	$ 1,35

Tel: 29-569

RECAUDACIÓN MUNICIPAL

VEdison

MOCACHE ALCALDIA

COMPROBANTE DE INGRESO A CAJA

FECHA DE EMISIÓN	FECHA RECAUDACIÓN	
11/12/2023	11/12/2023 4.03 PM	0328932

CONTRIBUYENTE	CÉDULA - RUC	COD. CATASTRAL
GOMEZ FIGUEROA JULIO GREGORIO	0912744240	

CONCEPTO

******* CERTIFICADO DE NO ADEUDAR *******

Area Terreno

SE CERTIFICA DE QUE NO ES DEUDOR(A) AL GOBIERNO AUTONOMO DESCENTRALIZADO MUNICIPAL DEL CANTON MOCACHE , COMO ESTABLECE EL COA DISPOSICIONES TRANSITORIAS OCTAVA Y ART. 4 DE LA ORDENANZA QUE ESTABLECE LA TASA POR SERVICIO TÉCNICO ADMINISTRATIVO MEMORANDUN 20-DFM DEL 24/6/19

ESTE CERTIFICADO TIENE VALIDEZ POR 30 DIAS A PARTIR DEL DÍA DE EMISIÓN.

SUBTOTALES	
TASA	$ 1,35
TOTAL RECIBIDO	$ 1,35

Tel: 29-569

RECAUDACIÓN MUNICIPAL

VEdison

ESPACIO EN BLANCO

Escaneado con CamScanner

MOCACHE ALCALDÍA — **COMPROBANTE DE INGRESO A CAJA**

FECHA DE EMISIÓN	FECHA RECAUDACIÓN	
01/01/2023	18/01/2023 3.34 PM	0290603

CONTRIBUYENTE	CÉDULA - RUC	COD. CATASTRAL
GOMEZ CANDELARIO JULIO ALBERT	1201046131	3647

CONCEPTO

***** PAGO ANUAL DE PREDIOS RURALES Y ADICI. *** 2023**

Nombre Predio: SAN LUIS II

Base $ 29.577,60 Area Terreno: 15.00 Dirección MACUL

RUBRO	VALOR
IMP. PREDIO RUSTICO	$ 81,34
INTERES	$ 0,00
TASA DE SEGURIDAD	$ 1,00
CUERPO DE BOMBEROS	$ 4,44
SERVICIO ADMINISTRATIVO	$ 1,35
TASA ADMINISTRATIVA POR	$ 1,35

7.7212

SUBTOTALES

EFECTIVO	$ 82,16
NOTA DE	$ 0,00
CHEQUE	$ 0,00
TARJETA DE	$ 0,00
TRANSFERENCI	$ 0,00
Subtotal	$ 89,48
Intereses	$ 0,00
Honorarios	$ 0,00
Descuentos	$ 7,32
Recargos	$ 0,00
TOTAL RECIBIDO	$ 82,16

Sec: 257137

RECAUDACIÓN MUNICIPAL

MEspinoza

MOCACHE ALCALDÍA — **COMPROBANTE DE INGRESO A CAJA**

FECHA DE EMISIÓN	FECHA RECAUDACIÓN	
01/01/2023	18/01/2023 3.34 PM	0290604

CONTRIBUYENTE	CÉDULA - RUC	COD. CATASTRAL
GOMEZ CANDELARIO JULIO ALBERT	1201046131	4346

CONCEPTO

***** PAGO ANUAL DE PREDIOS RURALES Y ADICI. *** 2023**

Nombre Predio: S/N

Base $ 38.603,07 Area Terreno: 70.62 Dirección BARRO COLORADO

RUBRO	VALOR
IMP. PREDIO RUSTICO	$ 115,81
INTERES	$ 0,00
TASA DE SEGURIDAD	$ 1,00
CUERPO DE BOMBEROS	$ 5,79
SERVICIO ADMINISTRATIVO	$ 1,35
TASA ADMINISTRATIVA POR	$ 1,35

2830

SUBTOTALES

EFECTIVO	$ 114,88
NOTA DE	$ 0,00
CHEQUE	$ 0,00
TARJETA DE	$ 0,00
TRANSFERENCI	$ 0,00
Subtotal	$ 125,30
Intereses	$ 0,00
Honorarios	$ 0,00
Descuentos	$ 10,42
Recargos	$ 0,00
TOTAL RECIBIDO	$ 114,88

Sec: 257139

RECAUDACIÓN MUNICIPAL

MEspinoza

NOTARIA SEXTA DEL CANTON QUEVEDO. De acuerdo con la facultad prevista en el Art. 18 numeral 5, literal e) de la Ley Notarial, doy fe que la(s) COPIA(S) que antecede(n), es igual al (los) documento(s) exhibido(s) en original (es) para que (la) haga (n) fe(s).

Quevedo, a

DR. CARLOS MENDOZA GARCIA MSc
NOTARIO SEXTO DEL CANTON QUEVEDO

NOTARIA SEXTA DEL CANTON QUEVEDO PROV. DE LOS RIOS DR. CARLOS MENDOZA GARCIA MSc NOTARIO TITULAR

Escaneado con CamScanner

REGISTRO MUNICIPAL DE LA PROPIEDAD Y MERCANTIL DEL CANTÓN MOCACHE

Dirección: 28 de mayo y bolivar esquina / Teléfono:

FICHA REGISTRAL	
NÚMERO	9.532
TIPO DE PREDIO	Inmueble Rural
CÓDIGO CATASTRAL	

CERTIFICADO DE FICHA REGISTRAL

Conforme a la solicitud # 3101, certifico hasta el dia de hoy, 11 de diciembre del 2023, la ficha registral # 9.532

La ficha registral contiene la historia jurídica del predio que consta en los archivos de este Registro de la Propiedad

INFORMACIÓN REGISTRAL

PROPIETARIO(S) GOMEZ CANDELARIO JULIO ALBERTO

PARROQUIA Mocache

TIPO DE BIEN TERRENO

SUPERFICIE 28.70HAS

DESCRIPCIÓN Y LINDERACIÓN

SCTOR BARRO COLORADO

norte CON MARIA ARREAGA RONQUILLO EN 64.28M
sur CON PAULINO ANTONIO LITARDO ASPIAZU EN 23.84, EN 21.92M EN 23.01M EN 24.23M EN 23.12, EN 22.00M.
este CON HEREDEROS COQUE AGUIRRE EN 82.71M EN 28.52M EN 5.46M EN 103.72M EN 45.61M EN 191.88M,CON TERENCIA GOMEZ FIGUEROA EN 90.13M EN 28.01M EN 50.29M, CON CARRETERO PUBLICO EN 3.76M EN 54.73M EN 29.01M, CON CRUCE DE CARRETERO PUBLICO EN 4.29M , CON RAMON GOMEZ CANDELARIO EN 158.08M EN 100.32M EN 88.20M EN 76.03M EN 33.79 EN 75.78M EN 50.28M, CON RODOLFO MENDOZA LITARDO EN 6.43M EN 109.01M EN 103.11M EN 107.04M EN 500.32M.
oeste CON PAULINO ANTONIO LITARDO ASPIAZU EN 37.02M EN 266.63M EN 273.83M CON CAMINO PRIVADO EN 54.07M EN 226.94M EN 13.93M CON RAMON GOMEZ CANDELARIO EN 23.01M EN 57.99M EN 42.87M EN 43.04M EN 41.75M EN 106.43M EN 48.05M EN 69.57M CON CRUCE EN CARRETERO PÚBLICO EN 4.42M CON RAMÓN GOMEZ CANDELARIO EN 49.22M EN 83.92M EN 63.04M EN 35.70M EN 52.42M EN 19.49M CON HEREDEROS ARREAGA GILER EN 54.63M EN 44.09M EN 53.39M

HISTORIA DE DOMINIO

Este bien inmueble, de acuerdo a los movimientos registrales, NO SOPORTA GRAVAMEN(es) vigente(s).

RESUMEN DE ACTOS REGISTRALES

Libro	Acto	Numero y Fecha de inscripción		Folio Inicial
Propiedades	Compraventa	270	14-jun-2018	1.532
Sentencias	Posesión	29	13-jul-2018	192

Certificación elaborada por MARISOL CARRANZA

Escaneado con CamScanner

DETALLE DE MOVIMIENTOS REGISTRALES

REGISTRO DE PROPIEDADES # 270 - 2018 : Compraventa

LIBRO Propiedades
ACTO Compraventa
TOMO 4 - 2.018 FOLIOS 1.532 - 1.537
NUMERO DE INSCRIPCIÓN 270 FECHA DE INSCRIPCION jueves,14 de junio de 2018
NUMERO DE REPERTORIO 365
OFICINA DONDE SE GUARDA EL DOCUMENTO ORIGINAL Notaría Tercera
CANTÓN DONDE SE ENCUENTRA LA OFICINA Quevedo
FECHA DE OTORGAMIENTO miércoles,13 de marzo de 2002
OFICIO / JUICIO / PROVIDENCIA / RESOLUCIÓN

a. OBSERVACIONES

INSCRITA ORIGINALMENTE EN EL REGISTRO DE LA PROPIEDAD DEL CANTON QUEVEDO BAJO EL No.1005 EN EL REGISTRO DE PROPIEDADES Y ANOTADA AL No.18888 EN EL LIBRO REPERTORIO EL 07 DE MAYO DEL AÑO 2002

b. INTERVINIENTES

Papel	Cédula / R.U.C.	Nombre y/o Razón Social	Estado Civil	Domicilio
Comprador	1201046131	GOMEZ CANDELARIO JULIO ALBERTO	No especificado	Mocache
Vendedor	1201363994	MONTOYA VERA ALICIA SUSANA	Soltero	Mocache
Vendedor	0905362521	ASPIAZU LITARDO MARCOS ALCIDES	Soltero	Mocache

REGISTRO DE SENTENCIAS # 29 - 2018 : Posesión

LIBRO Sentencias
ACTO Posesion
TOMO 1 - 2.018 FOLIOS 192 - 200
NUMERO DE INSCRIPCIÓN 29 FECHA DE INSCRIPCIÓN viernes,13 de julio de 2018
NUMERO DE REPERTORIO 461
OFICINA DONDE SE GUARDA EL DOCUMENTO ORIGINAL Notaría Primera
CANTÓN DONDE SE ENCUENTRA LA OFICINA El Empalme
FECHA DE OTORGAMIENTO viernes,22 de junio de 2018
OFICIO / JUICIO / PROVIDENCIA / RESOLUCIÓN

a. OBSERVACIONES

b. INTERVINIENTES

Papel	Cedula / R.U.C.	Nombre y/o Razón Social	Estado Civil	Domicilio
Causante	1201046131	GOMEZ CANDELARIO JULIO ALBERTO	No Aplica	No Especificado
Herederos	1202559688	GOMEZ FIGUEROA LUIS FRANCISCO	No especificado	Mocache
Herederos	1203580431	GOMEZ FIGUEROA GREGORIA GLADYS	No especificado	Mocache
Herederos	0909786535	GOMEZ FIGUEROA TERENCIA DE JESUS	No especificado	Mocache
Herederos	0912744240	GOMEZ FIGUEROA JULIO GREGORIO	No especificado	Mocache
Herederos	0912753093	GOMEZ FIGUEROA CLEOTILDE MERCEDES	No especificado	Mocache
Herederos	0912754009	GOMEZ FIGUEROA FILADELFIA DOLORES	No especificado	Mocache

REGISTRO DE PROPIEDADES # 340 - 2023 : Unificacion de lotes de Derechos y Acciones

LIBRO Propiedades
ACTO Unificacion de lotes de Derechos y Acciones
TOMO 4 - 2.023 FOLIOS 1.719 - 1.727
NÚMERO DE INSCRIPCIÓN 340 FECHA DE INSCRIPCIÓN martes,28 de marzo de 2023
NÚMERO DE REPERTORIO 300

Certificación elaborada por MARISOL CARRANZA

Escaneado con CamScanner

OFICINA DONDE SE GUARDA EL DOCUMENTO ORIGINAL Notaría Sexta
CANTÓN DONDE SE ENCUENTRA LA OFICINA Quevedo
FECHA DE OTORGAMIENTO viernes, 10 de febrero de 2023
OFICIO / JUICIO / PROVIDENCIA / RESOLUCIÓN

a. OBSERVACIONES

b. INTERVINIENTES

Papel	Cédula / R.U.C.	Nombre y/o Razón Social	Estado Civil	Domicilio
Causante-Propietario	1201046131	GOMEZ CANDELARIO JULIO ALBERTO	No Aplica	No Especificado
Heredero- unificante	0909786535	GOMEZ FIGUEROA TERENCIA DE JESUS	Soltera	Mocache
Heredero- unificante	0917744040	GOMEZ FIGUEROA JULIO GREGORIO	Soltero	Mocache
Heredero- unificante	0917757003	GOMEZ FIGUEROA CLEOTILDE MERCEDES	Casado	Mocache
Heredero- unificante	0917754003	GOMEZ FIGUEROA FILADELFIA DOLORES	Soltera	Mocache
Heredero- unificante	1202509686	GOMEZ FIGUEROA LUIS FRANCISCO	Casado	Mocache
Heredero- unificante	1202580491	GOMEZ FIGUEROA GREGORIA GLADYS	Casado	Mocache

c. ESTA INSCRIPCIÓN SE REFIERE A LA(S) QUE CONSTA(N) EN

Libro	Numero de Inscripción	Fecha de Inscripción	Folio Inicial	Folio Final
Propiedades	270	14-jun-2018	1.532	1.537
Propiedades	268	14-jun-2018	1.522	1.527

Los movimientos registrales que constan en esta ficha registral son los únicos que se refieren al predio que se certifica.

Cualquier enmendadura, alteración o modificación al texto de este certificado lo invalida.

IMPORTANTE

Se otorga el certificado en base a la solicitud presentada. Los datos consignados errónea o dolosamente exime de responsabilidad al Certificante.
El interesado deberá comunicar cualquier falla o error en este documento al Registrador de la Propiedad o a sus funcionarios para su inmediata modificación. Ley Orgánica del Sistema Nacional de Registro de Datos Públicos (SINARDAP), Artículo 8.- Rectificabilidad.- Los datos registrales del sistema son susceptibles de actualización, rectificación o supresión en los casos y con los requisitos que la ley señale.

MOCACHE, lunes 11 de diciembre de 2.023

Impreso a las 03:47:10p.m.

Dr. Manuel Bravo Bodero
REGISTRADOR DE LA PROPIEDAD (E)

GOBIERNO AUTÓNOMO DESCENTRALIZADO MUNICIPAL DE MOCACHE

ABOGADO

Certificación elaborada por MARISOL CARRANZA

Escaneado con CamScanner

REGISTRO MUNICIPAL DE LA PROPIEDAD Y MERCANTIL DEL CANTÓN MOCACHE

Dirección: 28 de mayo y bolivar esquina / Teléfono

FICHA REGISTRAL	
NÚMERO	9.530
TIPO DE PREDIO	Inmueble Rural
CÓDIGO CATASTRAL	

CERTIFICADO DE FICHA REGISTRAL

Conforme a la solicitud # 3102, certifico hasta el día de hoy, 11 de diciembre del 2023, la ficha registral # 9.530

La ficha registral contiene la historia jurídica del predio que consta en los archivos de este Registro de la Propiedad

INFORMACIÓN REGISTRAL

PROPIETARIO(S) GOMEZ CANDELARIO JULIO ALBERTO

PARROQUIA Mocache

TIPO DE BIEN TERRENO

SUPERFICIE 7.7213Has

DESCRIPCIÓN Y LINDERACIÓN

SECTOR: BARRO COLORADO

Norte: CON ELOY GOMEZ AGUIRRE EN 72.11M EN 79.51M EN 40.80M.
Sur: CON JULIA AGUIRRE FRANCO EN 46.10M CON LORENZA VERA ALVARADO EN 5.83M EN 36.00M EN 63.24M CON TEOFILO AGUIRRE FRANCO EN 68.14M.
Este: CON VERONICA CASTRO AGUIRRE EN 172.29M CON DANIEL JUNCO COELLO EN 41.30M EN 58.22M CON JULIA FIGUEROA BAJAÑA EN 88.96M.
Oeste: CON MARCO GUILLEN CASTRO EN 28.89M EN 54.23M CON GUARDARRAYA 39.40M EN 28.28M EN 44.20M EN 19.92M EN 103.17M CON ALBERTO LITARDO CADENA EN 106.37M.

OBSERVACIONES

SUPERFICIE, LINDEROS Y MEDIDAS ESTAN DADOS DE ACUERDO A LA ACLARATORIA DESCRITA POSTERIORMENTE.

HISTORIA DE DOMINIO

Este bien inmueble, de acuerdo a los movimientos registrales, NO SOPORTA GRAVAMEN(es) vigente(s).

RESUMEN DE MOVIMIENTOS REGISTRALES

Libro	Acto	Número y Fecha de inscripción		Folio Inicial
Propiedades	Adjudicacion	258	14-jun-2018	1.522
Sentencias	Posesión	29	13-jul-2018	192
Propiedades	Aclaratoria de Medida, Linderos y Superficie	677	05-ago-2021	4.101

Certificación elaborada por MARISOL CARRANZA

Escaneado con CamScanner

DETALLE DE MOVIMIENTOS REGISTRALES

REGISTRO DE PROPIEDADES # 268 - 2018 : Adjudicacion

LIBRO Propiedades
ACTO Adjudicacion
TOMO 4 - 2 018 FOLIOS 1 522 - 1 527
NUMERO DE INSCRIPCIÓN 268 FECHA DE INSCRIPCIÓN jueves,14 de junio de 2018
NUMERO DE REPERTORIO 383
OFICINA DONDE SE GUARDA EL DOCUMENTO ORIGINAL Notaria Segunda
CANTÓN DONDE SE ENCUENTRA LA OFICINA Quevedo
FECHA DE OTORGAMIENTO viernes,19 de julio de 1991
OFICIO / JUICIO / PROVIDENCIA / RESOLUCIÓN PROV ADJU No 910005561

a. OBSERVACIONES

INSCRITA ORIGINALMENTE EN EL REGISTRO DE LA PROPIEDAD DEL CANTON QUEVEDO BAJO EL No.2054 EN EL REGISTRO DE PROPIEDADES Y ANOTADA AL No.4216 EN EL LIBRO REPERTORIO EL 17 DE SEPTIEMBRE DE 1991

b. INTERVINIENTES

Papel	Cédula / R.U.C.	Nombre y/o Razon Social	Estado Civil	Domicilio
ADJUDICADOR		I.E.R.A.C	No Aplica	Quito
Adjudicatario	1201046131	GOMEZ CANDELARIO JULIO ALBERTO	No especificado	Mocache

REGISTRO DE SENTENCIAS # 29 - 2018 : Posesión

LIBRO Sentencias
ACTO Posesion
TOMO 1 - 2 018 FOLIOS 192 - 200
NUMERO DE INSCRIPCIÓN 29 FECHA DE INSCRIPCION viernes,13 de julio de 2018
NUMERO DE REPERTORIO 461
OFICINA DONDE SE GUARDA EL DOCUMENTO ORIGINAL Notaria Primera
CANTÓN DONDE SE ENCUENTRA LA OFICINA El Empalme
FECHA DE OTORGAMIENTO viernes,22 de junio de 2018
OFICIO / JUICIO / PROVIDENCIA / RESOLUCIÓN

a. OBSERVACIONES

b. INTERVINIENTES

Papel	Cédula / R.U.C.	Nombre y/o Razon Social	Estado Civil	Domicilio
Causante	1201046131	GOMEZ CANDELARIO JULIO ALBERTO	No Aplica	No Especificado
Heredero	1202339686	GOMEZ FIGUEROA LUIS FRANCISCO	No especificado	Mocache
Heredero	1201580491	GOMEZ FIGUEROA GREGORIA GLADYS	No especificado	Mocache
Heredero	0901786535	GOMEZ FIGUEROA TERENCIA DE JESUS	No especificado	Mocache
Heredero	0912744240	GOMEZ FIGUEROA JULIO GREGORIO	No especificado	Mocache
Heredero	0912753993	GOMEZ FIGUEROA OLEOTILDE MERCEDES	No especificado	Mocache
Heredero	0912754009	GOMEZ FIGUEROA FILADELFIA DOLORES	No especificado	Mocache

REGISTRO DE PROPIEDADES # 677 - 2021 : Aclaratoria de Medida, Linderos y Superficie

LIBRO Propiedades
ACTO Aclaratoria de Medida, Linderos y Superficie
TOMO 9 - 2 021 FOLIOS 4 101 - 4 106
NUMERO DE INSCRIPCIÓN 677 FECHA DE INSCRIPCIÓN jueves,5 de agosto de 2021
NUMERO DE REPERTORIO 769
OFICINA DONDE SE GUARDA EL DOCUMENTO ORIGINAL Notaria Primera

Escaneado con CamScanner

CANTÓN DONDE SE ENCUENTRA LA OFICINA Mocache
FECHA DE OTORGAMIENTO lunes,19 de julio de 2021
OFICIO / JUICIO / PROVIDENCIA / RESOLUCIÓN

a. OBSERVACIONES

b. INTERVINIENTES

Papel	Cédula / R.U.C.	Nombre y/o Razón Social	Estado Civil	Domicilio
Ratificante	0909786535	GOMEZ FIGUEROA TERENCIA DE JESUS	Casado	Velasco Ibarra
Ratificante	0912744240	GOMEZ FIGUEROA JULIO GREGORIO	Soltero	Velasco Ibarra
Ratificante	0912753993	GOMEZ FIGUEROA CLEOTILDE MERCEDES	Casado	Velasco Ibarra
Ratificante	0912754999	GOMEZ FIGUEROA FILADELFIA DOLORES	Soltero	Velasco Ibarra
Ratificante	1202559686	GOMEZ FIGUEROA LUIS FRANCISCO	Casado	Mocache
Ratificante	1203580491	GOMEZ FIGUEROA GREGORIA GLADYS	Casado	Velasco Ibarra

c. ESTA INSCRIPCIÓN SE REFIERE A LA(S) QUE CONSTA(N) EN

Libro	Número de Inscripción	Fecha de Inscripción	Folio Inicial	Folio Final
Propiedades	268	14-jun-2018	1.522	1.527

REGISTRO DE PROPIEDADES # 340 - 2023 : Unificacion de lotes de Derechos y Acciones

LIBRO Propiedades
ACTO Unificacion de lotes de Derechos y Acciones
TOMO 4 - 2.023 FOLIOS 1.719 - 1.727
NÚMERO DE INSCRIPCIÓN 340 FECHA DE INSCRIPCIÓN martes,28 de marzo de 2023
NÚMERO DE REPERTORIO 300
OFICINA DONDE SE GUARDA EL DOCUMENTO ORIGINAL Notaria Sexta
CANTÓN DONDE SE ENCUENTRA LA OFICINA Quevedo
FECHA DE OTORGAMIENTO viernes,10 de febrero de 2023
OFICIO / JUICIO / PROVIDENCIA / RESOLUCIÓN

a. OBSERVACIONES

b. INTERVINIENTES

Papel	Cédula / R.U.C.	Nombre y/o Razón Social	Estado Civil	Domicilio
Causante-Propietario	1201046131	GOMEZ CANDELARIO JULIO ALBERTO	No Aplica	No Especificado
Heredero- unificante	0909786535	GOMEZ FIGUEROA TERENCIA DE JESUS	Soltero	Mocache
Heredero- unificante	0912744240	GOMEZ FIGUEROA JULIO GREGORIO	Soltero	Mocache
Heredero- unificante	0912753993	GOMEZ FIGUEROA CLEOTILDE MERCEDES	Casado	Mocache
Heredero- unificante	0912754999	GOMEZ FIGUEROA FILADELFIA DOLORES	Soltero	Mocache
Heredero- unificante	1202559686	GOMEZ FIGUEROA LUIS FRANCISCO	Casado	Mocache
Heredero- unificante	1203580491	GOMEZ FIGUEROA GREGORIA GLADYS	Casado	Mocache

c. ESTA INSCRIPCIÓN SE REFIERE A LA(S) QUE CONSTA(N) EN

Libro	Número de Inscripción	Fecha de Inscripción	Folio Inicial	Folio Final
Propiedades	270	14-jun-2018	1.532	1.537
Propiedades	268	14-jun-2018	1.522	1.527

Escaneado con CamScanner

Los movimientos registrales que constan en esta ficha registral son los únicos que se refieren al predio que se certifica.

Cualquier enmendadura, alteración o modificación al texto de este certificado lo invalida.

MOCACHE, lunes 11 de diciembre de 2.023

IMPORTANTE

Se otorga el certificado en base a la solicitud presentada. Los datos consignados errónea o dolosamente exime de responsabilidad al Certificante.
El interesado deberá comunicar cualquier falta o error en este documento al Registrador de la Propiedad o a sus funcionarios para su inmediata modificación. Ley Orgánica del Sistema Nacional de Registro de Datos Públicos (SINARDAP), Artículo 6.- Rectificabilidad.- Los datos registrales del sistema son susceptibles de actualización, rectificación o supresión en los casos y con los requisitos que la ley señale.

Impreso a las 03:47:43p.m.

GOBIERNO AUTÓNOMO DESCENTRALIZADO MUNICIPAL DE MOCACHE

Dr. Manuel Bravo Bodero
REGISTRADOR DE LA PROPIEDAD (E)

Dr. Manuel Bravo Bodero
ABOGADO
Mat. Nº. 13-2007-04

Certificación elaborada por MARISOL CARRANZA

Escaneado con CamScanner

Mocache
ALCALDÍA CIUDADANA

Certificado N° 00314- DAC-AMG
Mocache, diciembre 07 del 2023

CERTIFICACIÓN

Arq. Adriana Moncayo García, Jefa del Departamento de Avalúos y Catastros del Gobierno Autónomo Descentralizado Municipal del Cantón Mocache.

CERTIFICO

De acuerdo al Criterio Jurídico N° 0251-GADMCM-PSM-2023, se autoriza la PARTICION EXTRAJUDICIAL Y ADJUDICACION VOLUNTARIA del terreno de propiedad de: **GOMEZ CANDELARIO JULIO ALBERTO** a favor de: **GOMEZ FIGUEROA CLEOTILDE MERCEDES** el área de 6.7020 HAS considerando un avalúo de $ 8.047,52 dólares de Norteamérica

Es todo cuanto puedo certificar en honor a la verdad y a los archivos que reposan en este departamento.

Atentamente.

Arq. Adriana Moncayo García
JEFA DE AVALUOS Y CATASTRO
AMG/Gepcenda
c.c. arch.

Escaneado con CamScanner

Certificado N° 00318- DAC-AMG
Mocache, diciembre 07 del 2023

CERTIFICACIÓN

Arq. Adriana Moncayo García, Jefa del Departamento de Avalúos y Catastros del Gobierno Autónomo Descentralizado Municipal del Cantón Mocache.

CERTIFICO

De acuerdo al Criterio Jurídico N° 0251-GADMCM-PSM-2023, se autoriza la PARTICION EXTRAJUDICIAL Y ADJUDICACION VOLUNTARIA del terreno de propiedad de. **GOMEZ CANDELARIO JULIO ALBERTO** a favor de **GOMEZ FIGUEROA FILADELFIA DOLORES** el área de **1.7433 HAS** considerando un avalúo de **$ 2.223,35** dólares de Norteamérica

Es todo cuanto puedo certificar en honor a la verdad y a los archivos que reposan en este departamento.

Atentamente.

Arq. Adriana Moncayo García
JEFA DE AVALUOS Y CATASTRO
AMG/Geoconda
c.c. arch.

Escaneado con CamScanner

Certificado N° 00315- DAC-AMG
Mocache, diciembre 07 del 2023

CERTIFICACIÓN

Arq. Adriana Moncayo García, Jefa del Departamento de Avalúos y Catastros del Gobierno Autónomo Descentralizado Municipal del Cantón Mocache.

CERTIFICO

De acuerdo al Criterio Jurídico N° 0251-GADMCM-PSM-2023, se autoriza la PARTICION EXTRAJUDICIAL Y ADJUDICACION VOLUNTARIA del terreno de propiedad de: **GOMEZ CANDELARIO JULIO ALBERTO** a favor de: **GOMEZ FIGUEROA GREGORIA GLADYS** el área de 1.6053 **HAS** considerando un avalúo de $ 2.947,35 dólares de Norteamérica

Es todo cuanto puedo certificar en honor a la verdad y a los archivos que reposan en este departamento.

Atentamente.

Arq. Adriana Moncayo García
JEFA DE AVALUOS Y CATASTRO
AMG/Gaoconda
c.c. arch.

Escaneado con CamScanner

Certificado N° 00317- DAC-AMG
Mocache, diciembre 07 del 2023

CERTIFICACIÓN

Arq. Adriana Moncayo Garcia, Jefa del Departamento de Avalúos y Catastros del Gobierno Autónomo Descentralizado Municipal del Cantón Mocache.

CERTIFICO

De acuerdo al Criterio Jurídico N° 0251-GADMCM-PSM-2023, se autoriza la PARTICION EXTRAJUDICIAL Y ADJUDICACION VOLUNTARIA del terreno de propiedad de: **GOMEZ CANDELARIO JULIO ALBERTO** a favor de: **GOMEZ FIGUEROA GREGORIA GLADYS** el área de 6.7020 **HAS** considerando un avalúo de $ 8.547,52 dólares de Norteamérica

Es todo cuanto puedo certificar en honor a la verdad y a los archivos que reposan en este departamento.

Atentamente.

Arq. Adriana Moncayo Garcia
JEFA DE AVALUOS Y CATASTRO
AMG/Geoconda
c.c. arch.

Escaneado con CamScanner

Certificado N° 00312- DAC-AMG
Mocache, diciembre 06 del 2023

CERTIFICACIÓN

Arq. Adriana Moncayo García, Jefa del Departamento de Avalúos y Catastros del Gobierno Autónomo Descentralizado Municipal del Cantón Mocache.

CERTIFICO

De acuerdo al Criterio Jurídico N° 0251-GADMCM-PSM-2023, se autoriza la PARTICION EXTRAJUDICIAL Y ADJUDICACION VOLUNTARIA del terreno de propiedad de: **GOMEZ CANDELARIO JULIO ALBERTO** a favor de: **GOMEZ FIGUEROA JULIO GREGORIO** el área de **2.4124 HAS** considerando un avalúo de **$** 3.070,78 dólares de Norteamérica.

Es todo cuanto puedo certificar en honor a la verdad y a los archivos que reposan en este departamento.

Atentamente.

Arq. Adriana Moncayo García
JEFA DE AVALUOS Y CATASTRO
AMG/Geoconda
c.c. arch.

Escaneado con CamScanner

Mocache
ALCALDÍA CIUDADANA

YENNY DOMINGUEZ
2023-2027
¡Un gobierno que nos une!

Certificado N° 00313- DAC-AMG
Mocache, diciembre 06 del 2023

CERTIFICACION

Arq. Adriana Moncayo García, Jefa del Departamento de Avalúos y Catastros del Gobierno Autónomo Descentralizado Municipal del Cantón Mocache.

CERTIFICO

De acuerdo al Criterio Jurídico N° 0251-GADMCM-PSM-2023, se autoriza la PARTICION EXTRAJUDICIAL Y ADJUDICACION VOLUNTARIA del terreno de propiedad de: **GOMEZ CANDELARIO JULIO ALBERTO** a favor de: **GOMEZ FIGUEROA CLEOTILDE MERCEDES** el área de 1.8347 HAS considerando un avalúo de $ 2.333,92 dólares de Norteamérica

Es todo cuanto puedo certificar en honor a la verdad y a los archivos que reposan en este departamento.

Atentamente.

Arq. Adriana Moncayo García
JEFA DE AVALUOS Y CATASTRO
AMG/Geoconda
c.c. arch.

ESTADO ENVIADO

Escaneado con CamScanner

Certificado N° 00311- DAC-AMG
Mocache, diciembre 03 del 2023

CERTIFICACIÓN

Arq. Adriana Moncayo García, Jefa del Departamento de Avalúos y Catastros del Gobierno Autónomo Descentralizado Municipal del Cantón Mocache.

CERTIFICO

De acuerdo al Criterio Jurídico N° 0251-GADMCM-PSM-2023, se autoriza la PARTICION EXTRAJUDICIAL Y ADJUDICACION VOLUNTARIA del terreno de propiedad de: **GOMEZ CANDELARIO JULIO ALBERTO** a favor de: **GOMEZ FIGUEROA JULIO GREGORIO** el área de 1.7898 HAS considerando un avalúo de $ 2.282,55 dólares de Norteamérica

Es todo cuanto puedo certificar en honor a la verdad y a los archivos que reposan en este departamento.

Atentamente,

Arq. Adriana Moncayo García
JEFA DE AVALUOS Y CATASTRO
AMG/Geoconda
c.c. arch.

Escaneado con CamScanner

Certificado N° 00310-DAC-AMG
Mocache, diciembre 06 del 2023

CERTIFICACIÓN

Arq. Adriana Moncayo García, Jefa del Departamento de Avalúos y Catastros del Gobierno Autónomo Descentralizado Municipal del Cantón Mocache.

CERTIFICO

De acuerdo al Criterio Jurídico N° 0251-GADMCM-PSM-2023, se autoriza la PARTICION EXTRAJUDICIAL Y ADJUDICACION VOLUNTARIA del terreno de propiedad de: **GOMEZ CANDELARIO JULIO ALBERTO** a favor de: **GOMEZ FIGUEROA TERENCIA DE JESUS** el área de **2.0841 HAS** considerando un avalúo de $ 2.657,99 dólares de Norteamérica

Es todo cuanto puedo certificar en honor a la verdad y a los archivos que reposan en este departamento.

Atentamente.

Arq. Adriana Moncayo García
JEFA DE AVALUOS Y CATASTRO
AMG/Geoconda
c.c. arch.

ESPACIO EN BLANCO

Escaneado con CamScanner

Certificado Nº 00309- DAC-AMG
Mocache, diciembre 06 del 2023

CERTIFICACIÓN

Arq. Adriana Moncayo García, Jefa del Departamento de Avalúos y Catastros del Gobierno Autónomo Descentralizado Municipal del Cantón Mocache.

CERTIFICO

De acuerdo al Criterio Jurídico Nº 0251-GADMCM-PSM-2023, se autoriza la PARTICION EXTRAJUDICIAL Y ADJUDICACION VOLUNTARIA del terreno de propiedad de: **GOMEZ CANDELARIO JULIO ALBERTO** a favor de: **GOMEZ FIGUEROA TERENCIA DE JESUS** el área de **2.0097 HAS** considerando un avalúo de $ 2.541,10 dólares de Norteamérica

Es todo cuanto puedo certificar en honor a la verdad y a los archivos que reposan en este departamento.

Atentamente,

Arq. Adriana Moncayo García
JEFA DE AVALUOS Y CATASTRO
AMG/Geoconda
c.c. arch.

Escaneado con CamScanner

Certificado N° 00317- DAC-AMG
Mocache, diciembre 07 del 2023

CERTIFICACIÓN

Arq. Adriana Moncayo García, Jefa del Departamento de Avalúos y Catastros del Gobierno Autónomo Descentralizado Municipal del Cantón Mocache.

CERTIFICO

De acuerdo al Criterio Jurídico N° 0251-GADMCM-PSM-2023, se autoriza la PARTICION EXTRAJUDICIAL Y ADJUDICACION VOLUNTARIA del terreno de propiedad de: **GOMEZ CANDELARIO JULIO ALBERTO** a favor de: **GOMEZ FIGUEROA LUIS FRANCISCO** el área de 1.7975 HAS considerando un avalúo de $ 2.202,47 dólares de Norteamérica

Es todo cuanto puedo certificar en honor a la verdad y a los archivos que reposan en este departamento.

Atentamente.

Arq. Adriana Moncayo García
JEFA DE AVALUOS Y CATASTRO
AMG/Geoconda
c.c. arch.

Escaneado con CamScanner

Certificado N° 00317- DAC-AMG
Mocache, diciembre 07 del 2023

CERTIFICACIÓN

Arq. Adriana Moncayo García, Jefa del Departamento de Avalúos y Catastros del Gobierno Autónomo Descentralizado Municipal del Cantón Mocache.

CERTIFICO

De acuerdo al Criterio Jurídico N° 0251-GADMCM-PSM-2023, se autoriza la PARTICION EXTRAJUDICIAL Y ADJUDICACION VOLUNTARIA del terreno de propiedad de: **GOMEZ CANDELARIO JULIO ALBERTO** a favor de: **GOMEZ FIGUEROA TERENCIA DE JESUS** y **GOMEZ FIGUEROA JULIO GREGORIO** el área de 4.1941 HAS considerando un avalúo de $ **15.522,95** dólares de Norteamérica

Es todo cuanto puedo certificar en honor a la verdad y a los archivos que reposan en este departamento.

Atentamente.

Arq. Adriana Moncayo García
JEFA DE AVALUOS Y CATASTRO
AMG/Gaconda
c.c. arch.

Escaneado con CamScanner

Certificado N° 00321- DAC-AMG
Mocache, diciembre 07 del 2023

CERTIFICACIÓN

Arq. Adriana Moncayo García, Jefa del Departamento de Avalúos y Catastros del Gobierno Autónomo Descentralizado Municipal del Cantón Mocache.

CERTIFICO

De acuerdo al Criterio Jurídico N° 0251-GADMCM-PSM-2023, se autoriza la PARTICION EXTRAJUDICIAL Y ADJUDICACION VOLUNTARIA del terreno de propiedad de: **GOMEZ CANDELARIO JULIO ALBERTO** a favor de: **GOMEZ FIGUEROA LUIS FRANCISCO** y **GOMEZ FIGUEROA CLEOTILDE MARCEDES** el área de **1.4106 HAS** considerando un avalúo de $ 6.220,83 dólares de Norteamérica

Es todo cuanto puedo certificar en honor a la verdad y a los archivos que reposan en este departamento

Atentamente.

Arq. Adriana Moncayo García
JEFA DE AVALUOS Y CATASTRO
AMG/Geoconda
c.c. arch.

ESPACIO EN BLANCO

Escaneado con CamScanner

Mocache
ALCALDÍA CIUDADANA

VERONICA BERMUDEZ
2023-2027
¡Un gobierno que nos une!

Certificado Nº 00322- DAC-AMG
Mocache, diciembre 07 del 2023

CERTIFICACIÓN

Arq. Adriana Moncayo García, Jefa del Departamento de Avalúos y Catastros del Gobierno Autónomo Descentralizado Municipal del Cantón Mocache.

CERTIFICO

De acuerdo al Criterio Jurídico Nº 0251-GADMCM-PSM-2023, se autoriza la PARTICION EXTRAJUDICIAL Y ADJUDICACION VOLUNTARIA del terreno de propiedad de: **GOMEZ CANDELARIO JULIO ALBERTO** a favor de: **GOMEZ FIGUEROA GREGORIA GLADYS** y **GOMEZ FIGUEROA FILADELFIA DOLORES** el área de 2.1100 HAS considerando un avalúo de **$ 7.833,83** dólares de Norteamérica

Es todo cuanto puedo certificar en honor a la verdad y a los archivos que reposan en este departamento.

Atentamente.

Arq. Adriana Moncayo García
JEFA DE AVALUOS Y CATASTRO
AMG/Goccanda
c.c. arch.

Escaneado con CamScanner

Mocache

Mocache
ALCALDÍA CIUDADANA

YENNY DOMINGUEZ
2023 - 2027
¡Un gobierno que nos une!

Oficio N° 056-SCG-ARFA-2023
Mocache, 05 de diciembre del 2023.

Señores (as)
HEREDEROS DEL SEÑOR JULIO ALBERTO GOMEZ CANDELARIO.

Ciudad.-

De mi consideración.

En atención a lo requerido por ustedes, respecto de la partición extrajudicial y adjudicación de dos lotes de terreno ubicados en el sector rural denominado "Barro Colorado" de esta jurisdicción cantonal, adjunto al presente la resolución tomada por el I. Concejo del Gobierno Autónomo Descentralizado Municipal del cantón Mocache en la Sesión Ordinaria realizada el jueves 16 de noviembre del 2023, copias certificadas del informe técnico y jurídico (19 hojas), así como los originales de los planos respectivos (13 hojas).

Particular que comunico para los fines pertinentes.

Atentamente,

Ab. Alcy Raúl Fajardo Arana
SECRETARIO I. CONCEJO / GENERAL

Adjunto: lo indicado.

Acción	Nombre	Cargo	Firma
Elaborado por:	Ab. Mariana Macías Chamber.	Analista de Secretaría	
Revisado por:	Ab. Alcy Raúl Fajardo Arana	Secretario General / Concejo	

Escaneado con CamScanner

Mocache

GOBIERNO AUTÓNOMO DESCENTRALIZADO MUNICIPAL DEL CANTÓN MOCACHE

En virtud de lo dispuesto en el Art. 357 del Código Orgánico de Organización Territorial, Autonomía y Descentralización,

CERTIFICO:

QUE EL I. CONCEJO MUNICIPAL DEL GOBIERNO AUTÓNOMO DESCENTRALIZADO MUNICIPAL DEL CANTÓN MOCACHE EN SESIÓN ORDINARIA REALIZADA EL JUEVES 16 DE NOVIEMBRE DEL 2023, QUINTO PUNTO: CONOCER Y RESOLVER RESPECTO DE LA AUTORIZACIÓN REQUERIDA POR HEREDEROS DEL SEÑOR JULIO ALBERTO GÓMEZ CANDELARIO, NECESARIA PARA REALIZAR LA PARTICIÓN EXTRAJUDICIAL Y ADJUDICACIÓN DE DOS LOTES DE TERRENO UBICADOS EN EL SECTOR RURAL DENOMINADO "BARRIO COLORADO" DE ESTA JURISDICCIÓN CANTONAL, CONFORME A LO ESTABLECIDO EN EL CÓDIGO ORGÁNICO DE ORGANIZACIÓN TERRITORIAL, AUTONOMÍA Y DESCENTRALIZACIÓN COOTAD EN EL ARTÍCULO 473 Y EL CRITERIO JURÍDICO N°0251-GADMCM-PSM-2023, SUSCRITO POR EL AB. RAFAEL BALLESTEROS VACA, PROCURADOR SÍNDICO MUNICIPAL, REMITIDO CON MEMORÁNDUM N°0407-GADMCM-PSM-2023 DE FECHA 02 DE OCTUBRE DEL 2023, resolvió:

"Conceder la autorización requerida por herederos del señor Julio Alberto Gómez Candelario, necesaria para realizar la partición extrajudicial y adjudicación de dos lotes de terreno ubicados en el sector rural denominado "Barrio Colorado" de esta jurisdicción cantonal, conforme a lo establecido en el Código Orgánico de Organización Territorial, Autonomía y Descentralización COOTAD en el artículo 473 y el Criterio Jurídico N°0251-GADMCM-PSM-2023, suscrito por el Ab. Rafael Ballesteros Vaca, Procurador Síndico Municipal, remitido con Memorándum N°0407-GADMCM-PSM-2023 de fecha 02 de octubre del 2023".

Lo Certifico.-

Mocache, 05 de diciembre del 2023

Ab. Alex Raúl Fajardo Arana
SECRETARIO DEL I. CONCEJO / GENERAL

c.c. arch.

Escaneado con CamScanner

Mocache
ALCALDÍA CIUDADANA

YENNY DOMÍNGUEZ
2023 - 2027
¡Un gobierno que nos une!
4120

PROCURADURÍA SINDICA

MEMORÁNDUM N° 0402-GADMCM-PSM-2023

PARA: **Ab. Yenny Domínguez Saltos- ALCALDESA DE MOCACHE.**

DE: Ab. Rafael Ballesteros Vaca
PROCURADOR SÍNDICO

ASUNTO: ENTREGA DE CRITERIO JURÍDICO DE PARTICION EXTRAJUDICIAL Y ADJUDICACION VOLUNTARIA.

FECHA: Mocache, 02 de octubre de 2023.

Adjunto al presente encontrara el **CRITERIO JURÍDICO No. 0251-GADMCM-PSM-2023,** relacionado a la **PARTICION EXTRAJUDICIAL Y ADJUDICACION VOLUNTARIA, DE UN LOTE DE TERRENO UBICADO EN LA ZONA RURAL DEL CANTON MOCACHE,** conforme a la petición realizada por **HEREDEROS GOMEZ FIGUEROA, GOMEZ FIGUEROA TERENCIA DE JESUS, GOMEZ FIGUEROA JULIO GREGORIO, GOMEZ FIGUEROA LUIS FRANCISCO, GOMEZ FIGUEROA CLEOTILDE MERCEDES, GOMEZ FIGUEROA GREGORIA GLADYS Y GOMEZ FIGUEROA FILADELFIA DOLORES** quien solicita la Partición Extrajudicial y Adjudicación Voluntaria, a favor de **GOMEZ FIGUEROA TERENCIA DE JESUS, GOMEZ FIGUEROA JULIO GREGORIO, GOMEZ FIGUEROA LUIS FRANCISCO, GOMEZ FIGUEROA CLEOTILDE MERCEDES, GOMEZ FIGUEROA GREGORIA GLADYS Y GOMEZ FIGUEROA FILADELFIA DOLORES** , lotes de terreno ubicado en el sector de **"Barro Colorado"**, de la jurisdicción del cantón Mocache.

Particular que remito para los fines pertinentes.

Atentamente;

Ab. Rafael Ballesteros Vaca
PROCURADOR SÍNDICO MUNICIPAL

Cc. Archivo

Elaborado por:	Ab. Irwin Romero Guevara.
Revisado por:	Ab. Rafael Ballesteros Vaca

POR DISPOSICIÓN DE LA MAXIMA AUTORIDAD PASA A CONOCIMIENTO DE

DIR. ADMINISTRACIÓN	DIR. FINANCIERA	DIR. CAPITALIZACIÓN Y DESPACHO	DIR. COMERCIO SOCIAL	DIR. OBRAS PÚBLICAS	DIR. OTALIS	PROCURADURÍA SÍNDICA
TALENTO HUMANO	RENTAS	COMUNICACIÓN SOCIAL	CULTURA, PATRIMONIO Y DEPORTES	AGUA POTABLE	MUSEOS Y CASAS TRIPS	[illegible]
COMPRAS PÚBLICAS	TELEGRAFÍA	[illegible]	[illegible]	GESTIÓN AMBIENTAL	PLANIFICACIÓN INSTITUCIONAL	DIVULGACIÓN UTM
[illegible]	COMISARÍA	TICS	TURISMO	DECLARACIÓN DE TIERRA	GESTIÓN DE RIESGOS	SECRETARÍA
ATENDER: GESTION			GESTION DE DESARROLLO Y ORDENAMIENTO	ARCHIVO	[illegible]	[illegible]

GAD. M. DEL CANTÓN MOCACHE
SECRETARÍA GENERAL
RECIBIDO
12 OCT 2023 11:20 HORA
FIRMA [illegible]

IGUAL A SU ORIGINAL
SECRETARIO GENERAL

Dir.: Calle 28 de Mayo y Bolívar

Escaneado con CamScanner

2.16. El artículo 57 de la Ley Orgánica de Ordenamiento Territorial, Uso de Gestión del Suelo, instituye que: Fraccionamiento, partición o subdivisión. El fraccionamiento, la partición o la subdivisión son procesos mediante los cuales un predio se subdivide en varios, por iniciativa pública o privada. Se podrá llevar a cabo mediante un plan parcial y unidades de actuación urbanística. En el caso que se haga sin una unidad de actuación urbanística se aplicará lo dispuesto en el Código Orgánico de Organización Territorial, Autonomía y Descentralización.

2.17. El Estatuto Orgánico de Gestión Organizacional por Procesos 2021 señala en el artículo 12.- Procesos Habilitantes de Asesoría 12.1 Procuraduría Síndica – Atribuciones y Responsabilidades literal f) Absolver consultas y brindar asesoría jurídica a el/la Alcalde/sa, Concejo Cantonal Municipal y Unidades Administrativas del Gobierno Municipal.

III.- ANÁLISIS Y CRITERIO JURÍDICO:

Como se observa en los antecedentes expuestos, la normativa jurídica inherente al tema en el considerando; en mi calidad de Procurador Síndico del Gobierno Autónomo Descentralizado Municipal del Cantón Mocache, al respecto se establece el siguiente análisis y criterio jurídico:

3.1.- Cumplimiento del ordenamiento jurídico. - Tal como lo instituye la norma jurídica para el efecto, la juridicidad de las actuaciones administrativas, se someten a la Constitución de la República, a la ley, a los principios, a la jurisprudencia aplicable; en cuyo sentido la potestad discrecional se utilizará conforme a derecho.

3.2.- De la eficacia jurídica de los fraccionamientos de lote terreno en la zona rural.- El propietario o propietaria de un predio (lote de terreno) que se encuentre ubicado en el área rural, que requiera efectuar actos de fraccionamientos de dominio, ya sea por venta, partición o donación u otra cosa similar, en efecto requerirá que la Dirección de Gestión de Ordenamiento Territorial y Planeamiento Urbano y Rural del GAD Municipal del Cantón Mocache, apruebe el plano respectivo de desmembración o fraccionamiento del lote o lotes de terreno, para lo cual la referida Unidad Administrativa necesariamente deberá considerar lo establecido el numeral 3 del artículo 19 de la Ley de Ordenamiento Territorial de Uso y Gestión del Suelo.

3.3.- Criterios jurídicos concluyentes. - Con los antecedentes expuestos, esta Procuraduría Síndica Municipal, considera procedente y legal que la administración del Gobierno Autónomo Descentralizado Municipal del Cantón Mocache, apruebe la partición extrajudicial y adjudicación voluntaria, según solicitud presentada por los Herederos del causante Julio Alberto Gómez Candelario como son: **Gómez Figueroa Terencia De Jesús, Gómez Figueroa Julio Gregorio, Gómez Figueroa Luis Francisco, Gómez Figueroa Cleotilde Mercedes, Gómez Figueroa Gregoria Gladys Y Gómez Figueroa Filadelfia Dolores**, somos , propietarios del terreno ubicado en el sector rural de "**Barro Colorado**", a favor de **Gómez Figueroa Terencia De Jesús, Gómez Figueroa Julio Gregorio, Gómez Figueroa Luis Francisco, Gómez Figueroa Cleotilde Mercedes, Gómez Figueroa Gregoria Gladys Y Gómez Figueroa Filadelfia Dolores** , en base al memorándum **N.º 0857-DOTPUR-ZNMA-2023**, suscrito por la PhD. Zoila Merino Acosta, Directora de Ordenamiento Territorial y Planeamiento Urbano y Rural, del GAD

Escaneado con CamScanner

evidencia que conste en el expediente administrativo. La explicación de la pertinencia del régimen jurídico invocado en relación con los hechos determinados.

2.8. El artículo 595 del Código Civil ecuatoriano codificado, determina que: "Derecho real es el que tenemos sobre una cosa sin respecto determinada persona. Son derechos reales el de dominio, el de herencia, los de usufructo, uso o habitación, los de servidumbres activas, el de prenda y el de hipoteca. De estos derechos nacen las acciones reales.

2.9. El artículo 53 del Código Orgánico de Organización Territorial, Autonomía y Descentralización, el mismo que en adelante será denominado por sus siglas –COOTAD, establece que los gobiernos autónomos descentralizados municipales son personas jurídicas de derecho público, con autonomía política administrativa y financiera (...).

2.10. El literal c) del artículo 54 del COOTAD, determina que: Son funciones del gobierno autónomo descentralizado municipal las siguientes: (...) Establecer el régimen de uso del suelo y urbanístico, para lo cual determinará las condiciones de urbanización, parcelación, lotización, división o cualquier otra forma de fraccionamiento de conformidad con la planificación cantonal, asegurando porcentajes para zonas verdes y áreas comunales.

2.11. El literal d) del artículo 57 del COOTAD, determina que al Concejo Municipal le corresponde: Expedir acuerdos o resoluciones, en al ámbito de la competencia del gobierno autónomo descentralizado municipal, para regular temas institucionales específicos o reconocer derechos particulares.

2.12 El artículo 473 del COOTAD, determina que: Partición Judicial y Extrajudicial de Inmuebles.- En el caso de partición judicial de inmuebles los jueces ordenaran que se cite con la demanda con la municipalidad del cantón (...). En el caso de partición extrajudicial, los interesados pedirán al Gobierno municipal o metropolitano la autorización respectiva, sin la cual no podrá realizarse la partición.

2.13. El numeral 8 del artículo 4 de la Ley Orgánica de Ordenamiento Territorial Uso y Gestión de Suelo, instituye que: Para efectos de la aplicación de esta Ley, se utilizarán las siguientes definiciones constantes en este artículo: (...) Fraccionamiento, partición o subdivisión. Son los procesos mediante los cuales un predio se subdivide en varios predios a través de una autorización del gobierno autónomo descentralizado municipal o metropolitano, que viabiliza el registro e individualización de predios, solares o lotes resultantes, los cuales pueden tener distintos condicionamientos y obligaciones (...).

2.14. El artículo 16 de la Ley Orgánica de Ordenamiento Territorial, Uso y Gestión del Suelo, señala que: El suelo es el soporte físico de las actividades que la población lleva a cabo en búsqueda de su desarrollo integral sostenible y en el que se materializan las decisiones y estrategias territoriales, de acuerdo con las dimensiones social, económica, cultural y ambiental.

2.15. El artículo 19 de la Ley Orgánica de Ordenamiento Territorial, Uso y Gestión del Suelo, establece que: El suelo rural es el destinado principalmente a actividades agroproductivas, extractivas o forestales, o el que por sus especiales características biofísicas o geográficas debe ser protegido o reservado para futuros usos urbanos. Para el suelo rural se establece la siguiente subclasificación (...).

GADM DEL CANTÓN MOCACHE
CERTIFICO QUE ESTA COPIA ES IGUAL A SU ORIGINAL

SECRETARIO GENERAL

Dir.: Calle 28 de Mayo y Bolivar
www.mocache.gob.ec

Escaneado con CamScanner

encuentra ubicado en el sector denominado **"BARRO COLORADO"**, perteneciente a esta Jurisdicción Cantonal. Es todo cuanto puedo certificar en honor a la verdad y a los archivos que reposan en este departamento (...)". **1.7.1.-** El Certificado No. 362-DAC-AMG de fecha 18 de septiembre de 2023 suscrito por la Arq. Adriana Moncayo García, Jefa del Departamento de Avalúos y Catastros del Gobierno Autónomo Descentralizado Municipal del Cantón Mocache, el mismo que en su parte pertinente señala: **CERTIFICO:** Que una vez revisados lo catastros de predios rurales del Cantón Mocache, consta ingresada al catastro una propiedad a nombre de: **JULIO ALBERTO GOMEZ CANDELARIO**, con Registro Catastral N° 4846 con un área de terreno de **28.700Has** cuyo avalúo es de **$ 30.603.07** del año **2023**, el mismo que se encuentra ubicado en el sector denominado "BARRO COLORADO", perteneciente a esta Jurisdicción Cantonal. Es todo cuanto puedo certificar en honor a la verdad y a los archivos que reposan en este departamento (...)"

II.- FUNDAMENTOS JURIDICOS:

2.1. El primer inciso del artículo 1 de la Constitución de la República del Ecuador, establece que: "El Ecuador es un Estado constitucional de derechos y justicia (...).

2.2. El artículo 66.26 de la Constitución de la República, establece que: Se reconoce y garantizará a las personas: "El derecho a la propiedad en todas sus formas, con función y responsabilidad social y ambiental. El derecho al acceso a la propiedad se hará efectivo con la adopción de políticas públicas, entre otras medidas".

2.3. El artículo 226 de la Constitución de la República, instituye que: Las instituciones del Estado, sus organismos, dependencias, las servidoras o servidores públicos y las personas que actúen en virtud de una potestad estatal ejercerán solamente las competencias y facultades que les sean atribuidas en la Constitución y la ley. Tendrán el deber de coordinar acciones para el cumplimiento de sus fines y hacer efectivo el goce y ejercicio de los derechos reconocidos en la Constitución.

2.4. El numeral 2 del artículo 264 de la Constitución de la República, determina que: Los gobiernos municipales tendrán las (...) competencias exclusivas sin perjuicio de otras que determine la ley Ejercer el control sobre el uso y ocupación del suelo en el cantón.

2.5. El artículo 321 de la Constitución de la República, establece que el Estado reconoce y garantiza el derecho a la propiedad en sus formas pública, privada, comunitaria, estatal, asociativa, cooperativa, mixta, y que deberá cumplir su función social y ambiental, por lo que en materia de propiedad privada se debe garantizar al propietario el ejercicio de sus facultades de usar, gozar y disponer libremente de lo que le pertenece.

2.6. El artículo 23 del Código Orgánico Administrativo determina, que: La decisión de las administraciones públicas debe estar motivada.

2.7. Los numerales 1, 2 y 3 del artículo 100 del Código Orgánico Administrativo, determina que En la motivación del acto administrativo se observará: El señalamiento de la norma jurídica o principios jurídicos aplicables y la determinación de su alcance. La calificación de los hechos relevantes para la adopción de la decisión, sobre la base de la

Escaneado con CamScanner

favorable técnicamente, Constatando que en el sitio se encuentra y sembrío de ciclo corto, siendo favorable técnicamente para uso agrícola, consecuentemente sírvase emitir su criterio jurídico al respecto.

De acuerdo a la ordenanza que aprueba el plan de desarrollo y ordenamiento territorial del cantón Mocache 2021-2023, y el plan de uso y gestión de suelo del Cantón Mocache 2021-2023 acogiéndonos al capítulo III compatibilidad, ocupación y edificabilidad, art 43 y tabla N° 6 usos generales y específicos de suelo rural, los predios para partición extrajudicial y adjudicación voluntaria serán de uso Agrícola.

1.5. El memorándum No 0857-DOTPUR-ZMA-2023, de fecha 25 de julio del 2023, suscrito por la PhD. Zoila Merino Acosta, Directora de Ordenamiento Territorial y Planeamiento Urbano y Rural, la misma que en su parte pertinente señala: "Abg. Rafael Ballesteros Vaca PROCURADOR SÍNDICO MUNICIPAL.- En atención a la solicitud actual # 2423 de 15 de agosto de 2023, suscrita por los Herederos Gómez Figueroa, **Gómez Figueroa Terencia De Jesús, Gómez Figueroa Julio Gregorio, Gómez Figueroa Luis Francisco, Gómez Figueroa Cleotilde Mercedes, Gómez Figueroa Gregoria Gladys** Y **Gómez Figueroa Filadelfia Dolores** quienes solicitan la autorización de la partición extrajudicial y adjudicación voluntaria de predios, ubicados en el sector rural **"Barro Colorado"**, informando que luego de revisada la documentación y de haber realizado la inspección en el sitio por el Arq. Carlos Sinchiguano B. Analista de Avalúos y Catastro del GAD Municipal del cantón Mocache, el 14/09/2023, el plano se ajusta a las medidas y coordenadas. Constatando que el sitio a partir seguirá siendo de uso agrícola.

1.6. El Informe de Regulación Urbana y Rural No. 149-2023 de fecha 18 de septiembre de 2023, suscrito por la PhD, Zoila Merino Acosta, Directora de Ordenamiento Territorial y Planeamiento Urbano y Rural, indica que el predio de clave catastral 3647 de propiedad de los Herederos de Julio Alberto Gómez Candelario donde indica que se realizó el informe de regulación del terreno ubicado en el sector rural de Barro Colorado de la jurisdicción cantonal de Mocache, y que dicho terreno obtiene la ocupación del suelo Agrícola, que no tiene ninguna afectación. **1.6.1** - El Informe de Regulación Urbana y Rural No. 150-2023 de fecha 18 de septiembre de 2023, suscrito por la PhD, Zoila Merino Acosta, Directora de Ordenamiento Territorial y Planeamiento Urbano y Rural, indica que el predio de clave catastral 4846 de propiedad de los Herederos de Julio Alberto Gómez Candelario donde indica que se realizó el informe de regulación del terreno ubicado en el sector rural de Barro Colorado de la jurisdicción cantonal de Mocache, y que dicho terreno obtiene la ocupación del suelo Agrícola, que no tiene ninguna afectación.

1.7. El Certificado No. 361-DAC-AMG de fecha 18 de septiembre de 2023 suscrito por la Arq. Adriana Moncayo García, Jefa del Departamento de Avalúos y Catastros del Gobierno Autónomo Descentralizado Municipal del Cantón Mocache, el mismo que en su parte pertinente señala: **CERTIFICO:** Que una vez revisados lo catastros de predios rurales del Cantón Mocache, consta ingresada al catastro una propiedad a nombre de: **JULIO ALBERTO GOMEZ CANDELARIO,** con Registro Catastral N° 3647 con un área de terreno de **7.7213Has** cuyo avalúo es de **$ 29.577.60** del año **2023**, el mismo que se

SECRETARIO GENERAL

Escaneado con CamScanner

SUR	Con Luis Francisco Gómez Figueroa y Cleotilde Mercedes Gómez Figueroa en 184.90m
ESTE	Con Castro Aguirre Verónica en 172.29m
	Con Junco Coello Daniel en 41.30m
OESTE	Con Guardarraya frente a Litardo Cadena Alberto en 21.81m; 19.92m; 103.17m
	Con Litardo Cadena Alberto en 106.37m

Linderos y Medidas del lote para partición extrajudicial y adjudicación voluntaria a favor de: Luis Francisco Gómez Figueroa y Cleotilde Mercedes Gómez Figueroa en 1.4106 Has

NORTE	Con Terencia De Jesús Gómez Figueroa y Julio Gregorio Gómez Figueroa en 184.90m
SUR	Con Filadelfia Gómez Figueroa y Gregoria Gladys Gómez Figueroa en 241.70m
ESTE	Con Junco Coello Daniel en 58.22m
OESTE	Con Guillen Castro Marco en 13.58m
	Con Guardarraya frente a Litardo Cadena Alberto en 39.40m; 28.28m; 22.39m

Linderos y Medidas del lote para partición extrajudicial y adjudicación voluntaria a favor de: Filadelfia Gómez Figueroa y Gregoria Gladys Gómez Figueroa en 2.1166 Has

NORTE	Con Luis Francisco Gómez Figueroa y Cleotilde Mercedes Gómez Figueroa en 241.70m
SUR	Con Aguirre Franco Julia en 46.10m;
	Con Vera Alvarado Lorenzo en 5.83m; 36.00m; 63.24m
	Con Aguirre Franco Teofilo en 68.14m
ESTE	Con Figueroa Bajaña Julia en 88.96m
OESTE	Con Guillen Castro Marco en 64.51m; 40.65m.

Ante lo expuesto debo mencionar que luego de haber realizado la inspección en el sitio, por el Arq. Carlos Sinchiguano Barahona. Analista de Avalúos y Catastro. El 14/09/2023, los planos se ajustan a las medidas y coordenadas, por lo tanto el presente Informe es

Escaneado con CamScanner

ESTE	Con Gómez Candelario Ramón en 46.64m; 33.79m; 75.78m; 14.14m; 6.43m; 23.53m
OESTE	Con Gómez Ramón en 102.73m; 13.93m; 23.01m; 36.69m; 21.30m; 42.87m; 43.04m; 41.75m; 20.60m

Linderos y Medidas del lote para partición extrajudicial y adjudicación voluntaria a favor de: Gómez Figueroa Filadelfia Dolores en 1.7433 has

NORTE	Con Gómez Figueroa Julio en 41.99m
SUR	Con Litardo Aspiazu Paulino Antonio en 23.12m
ESTE	Con Gómez Figueroa Cleotilde en 309.55m; 327.64m
OESTE	Con Gómez Figueroa Gregoria en 316.12m; 284.81

Linderos y Medidas del lote para partición extrajudicial y adjudicación voluntaria a favor de: Gómez Figueroa Luis Francisco en 1.7975 has

NORTE	Con Gómez Figueroa Julio Gregorio en 35.52m
SUR	Con Paulino Antonio Litardo Aspiazu en 23.01m
ESTE	Con Julio Gómez Figueroa en 244.69m; 438.55m
OESTE	Con Cleotilde Gómez Figueroa en 343.77m; 322.18m

Área de Guardarraya Publica 0.0192 has.

Sector: BARRO COLORADO

Área Total: 7.7213 Has

Datos de terreno	
AREA SEGÚN REGISTRO:	7.7213 Has
ÁREA GRÁFICA:	7.7213 Has
AVALÚO:	$ 29.577,60
CLAVE CATASTRAL:	3647
ZONA:	Rural
SECTOR:	Barro Colorado

Linderos y Medidas del lote para partición extrajudicial y adjudicación voluntaria a favor de: Terencia De Jesús Gómez Figueroa y Julio Gregorio Gómez Figueroa en 4.194 has

NORTE	Con Gómez Aguirre Eloy en 72.11m; 79.51m; 40.60m

MOCACHE CERTIFICO QUE ESTA COPIA ES IGUAL A SU ORIGINAL

SECRETARIO GENERAL

Escaneado con CamScanner

Linderos y Medidas del lote para partición extrajudicial y adjudicación voluntaria a favor de: Gómez Figueroa Cleotilde Mercedes con 1.8347 has

NORTE	Con Gómez Figueroa Julio en 35.65m
SUR	Con Litardo Aspiazu Paulino Antonio en 24.23m
ESTE	Con Gómez Figueroa Luis en 322.18m; 343.77m
OESTE	Con Gómez Figueroa Filadelfia en 327.64m; 309.55

Linderos y Medidas del lote para partición extrajudicial y adjudicación voluntaria a favor de: Gómez Figueroa Cleotilde Mercedes con 6.7020 has

NORTE	Con Hdros Arreaga Giler en 54.63m; 44.09m; 53.39m
	Con María Arreaga Ronquillo en 64.28m
	Con Hdros Coque Aguirre en 33.33m; 49.39m; 28.52m; 32.70m
SUR	Con Gregoria Gómez Figueroa en 235.95m
ESTE	Con Terencia Gómez Figueroa en 297.63m
	Con Hdros Gómez Figueroa en 22.57m; 50.29m;
	Con Guardarraya Pública en 3.75m; 54.73m; 29.01m;
	Con Cruce de Guardarraya Pública en 4.29m
	Con Ramón Gómez en 158.08m; 100.32m; 88.2m; 29.39m
OESTE	Con Ramón Gómez Candelario en 85.63m; 48.05m; 69.64m
	Con Cruce de Guardarraya Pública en 4.42m
	Con Ramón Gómez Candelario en 49.22m; 88.92m; 98.74m; 52.42m; 19.47m

Linderos y Medidas del lote para partición extrajudicial y adjudicación voluntaria a favor de: Gómez Figueroa Gregoria Gladys en 1.6053 has

NORTE	Con Gómez Figueroa Julio en 34.98m
SUR	Con Litardo Aspiazu Paulino Antonio en 22.00m
ESTE	Con Gómez Figueroa Filadelfia en 284.81m; 316.12m
OESTE	Con Litardo Aspiazu Paulino Antonio en 303.65m; 273.83m

Linderos y Medidas del lote para partición extrajudicial y adjudicación voluntaria a favor de: Gómez Figueroa Gregoria Gladys en 6.7020 has

NORTE	Con Gómez Figueroa Cleotilde en 235.95m
SUR	Con Gómez Figueroa Julio en 210.64m

Escaneado con CamScanner

ESTE	Con Mendoza Aguirre Rodolfo en 103.11m, 107.04m, 500.32m
OESTE	Con Gómez Figueroa Julio Gregorio en 485.86m; 210.81m

Linderos y Medidas del lote para partición extrajudicial y adjudicación voluntaria a favor de: Gómez Figueroa Terencia de Jesús con 2.0841 Has

NORTE	Con Hdros Coque Aguirre en 76.28m
SUR	Con Gómez Figueroa Terencia de Jesús en 94.18m
ESTE	Con Hdros Coque Aguirre en 237.48m
OESTE	Con Gómez Figueroa Cleotilde en 297.63m

Linderos y Medidas del lote para partición extrajudicial y adjudicación voluntaria a favor de: Gómez Figueroa Julio Gregorio con 1.7898 Has

NORTE	Con Gómez Figueroa Julio en 30.15m
SUR	Con Litardo Aspiazu Paulino Antonio en 21.92m
ESTE	Con Gómez Figueroa Terencia en 210.81m; 485.87m
OESTE	Con Gómez Figueroa Luis en 438.54m; 244.69m

Linderos y Medidas del lote para partición extrajudicial y adjudicación voluntaria a favor de: Gómez Figueroa Julio Gregorio con 2.4124 has

NORTE	Con Gómez Figueroa Gregoria en 210.64m
SUR	Con Gómez Figueroa Terencia de Jesús en 36.16m
	Con Gómez Figueroa Julio en 30.15m
	Con Gómez Figueroa Luis en 35.52m
	Con Gómez Figueroa Cleotilde en 35.85m
	Con Gómez Figueroa Filadelfia en 41.99m
	Con Gómez Figueroa Gregoria en 34.98m
ESTE	Con Gómez Candelario Ramón en 85.47m
OESTE	Con Litardo Aspiazu Paulino Antonio en 178.26m

GADM. DEL CANTÓN MOCACHE
CERTIFICO QUE ESTA COPIA ES IGUAL A SU ORIGINAL

SECRETARIO GENERAL

Escaneado con CamScanner

1.2. Se adjunta la Posesión Efectiva, concedida a favor de los herederos del causante Julio Alberto Gómez Candelario, realizada en la notaria tercera del Cantón Quevedo, el 21 de junio del 2021 e inscrita en el Registro Municipal de la Propiedad y Mercantil del Cantón Mocache, el 13 de julio del 2018. (...).

1.3. Certificado del Registro de la Propiedad con ficha registral # **9.532** de fecha 3 de agosto del 2023, suscrito por el doctor Manuel Bravo Bodero, Registrador de la Propiedad del GAD Municipal del Cantón Mocache, el mismo que en su parte pertinente señala: Que en la Información registral consta inscrita una propiedad a favor de **GOMEZ CALENDARIO JULIO ALBERTO** con una superficie de **28.70HAS**. (.) No soporta gravamen.1.3.1.- Certificado del Registro de la Propiedad con ficha registral # **9.530** de fecha 3 de agosto del 2023, suscrito por el doctor Manuel Bravo Bodero, Registrador de la Propiedad del GAD Municipal del Cantón Mocache, el mismo que en su parte pertinente señala: Que en la Información registral consta inscrita una propiedad a favor de **GOMEZ CALENDARIO JULIO ALBERTO** con una superficie de **7.7213 HAS**. (..) No soporta gravamen.

1.4. Que mediante Informe Técnico No. 168-2023 de fecha 14 de septiembre de 2023, suscrito por el Arq. Carlos Sinchiguano B, Analista de Avalúos y Catastro del GAD Municipal del cantón Mocache, el mismo que en su parte pertinente señala (...).

Una vez revisada toda la documentación presentada y los planos en físico y digital, Informe de regulación Rural, el Informe Técnico de campo # 168-2023, de acuerdo a lo expuesto detallo el siguiente Informe Técnico de Campo.

Informe Técnico:

Sector: BARRO COLORADO

Área Total: 28.70 Has

Datos de terreno	
AREA SEGÚN REGISTRO:	**28.70 has**
ÁREA GRÁFICA:	**28.70 has**
AVALÚO:	$ 36.603,07
CLAVE CATASTRAL:	4846
ZONA:	Rural
SECTOR:	Barro Colorado

<u>Linderos y Medidas del lote para partición extrajudicial y adjudicación voluntaria a favor de:</u> Gómez Figueroa Terencia de Jesús con 2.0097 Has

NORTE Con Gómez Figueroa Julio Gregorio con 36.16m

SUR Con Litardo Aspiazu Paulino Antonio en 23.84m

Escaneado con CamScanner

CRITERIO JURÍDICO No. 0251-GADMCM-PSM-2023

"PARTICION EXTRAJUDICIAL DE UN LOTE DE TERRENO UBICADO EN LA ZONA RURAL DE "BARRO COLORADO" DE LA JURISDICCION DEL CANTON MOCACHE". -

1.- FUNDAMENTOS DE HECHOS:

1.1 El escrito de fecha 15 de agosto de 2023, presentado por los **HEREDEROS GOMEZ FIGUEROA: GOMEZ FIGUEROA TERENCIA DE JESUS, GOMEZ FIGUEROA JULIO GREGORIO, GOMEZ FIGUEROA LUIS FRANCISCO, GOMEZ FIGUEROA CLEOTILDE MERCEDES, GOMEZ FIGUEROA GREGORIA GLADYS Y GOMEZ FIGUEROA FILADELFIA DOLORES,** solicitamos la autorización para realizar la **PARTICION EXTRAJUDICIAL Y ADJUDICACION HEREDITARIA** de dos lotes de Terreno de 28.70HAS y 7.7213 has, ubicados en el **SECTOR "BARRO COLORADO"**, del Cantón Mocache, los terrenos a desmembrar serán de uso agrícola(...).

NOMBRE Y APELLIDOS	CI
Gómez Figueroa Terencia de Jesús	0909786535
Gómez Figueroa Julio Gregorio	0912744240
Gómez Figueroa Luis Francisco	1202559686
Gómez Figueroa Cleotilde Mercedes	0912753993
Gómez Figueroa Gregoria Gladys	1203580491
Gómez Figueroa Filadelfia Dolores	0912754009

Solicitando una Partición Extrajudicial y Adjudicación Voluntaria de dos lotes en el sector rural de BARRO COLORADO, a favor de:

Lote N°1 de 28.70 Has

NOMBRE Y APELLIDOS	AREA	
Gómez Figueroa Terencia de Jesús	2.0097 Has	2.0841 Has
Gómez Figueroa Julio Gregorio	1.7898 Has	2.4124 Has
Gómez Figueroa Cleotilde Mercedes	1.8347 Has	6.7020 Has
Gómez Figueroa Gregoria Gladys	1.6053 Has	6.7020 Has
Gómez Figueroa Filadelfia Dolores	1.7433 Has	-
Gómez Figueroa Luis Francisco	1.7975 Has	-
Guardarraya Pública	0.0192 has	
Total	28.70 has	

Lote N°2 de 7.7213 Has

NOMBRE Y APELLIDOS	AREA
Gómez Figueroa Terencia de Jesús	4.1941 Has
Gómez Figueroa Julio Gregorio	
Gómez Figueroa Luis Francisco	1.4106 Has
Gómez Figueroa Cleotilde Mercedes	
Gómez Figueroa Gregoria Gladys	2.1166 Has
Gómez Figueroa Filadelfia Dolores	
Total	**7.7213 Has**

CANTON MOCACHE
QUE ESTA COPIA ES
IGUAL A SU ORIGINAL

SECRETARIA GENERAL

Dir.: Calle 28 de Mayo y Bolivar
www.mocache.gob.ec

Escaneado con CamScanner

Municipal, y el Informe Técnico N° 168, suscrito por el Arq. Carlos Sinchiguano B. Analista de Avalúos y Catastro del GAD Municipal del cantón Mocache, en la que indica que los planos se ajustan a las medidas y coordenadas, por lo tanto el presente informe es favorable técnicamente, además se constató que el para la Partición Extrajudicial y Adjudicación será de uso Agrícola en función al plan de uso y gestión del suelo ( ).

3.4.- Para el efecto de la respectiva celebración de la escritura como la de su inscripción en función del acto administrativo de fraccionamiento, los respectivos funcionarios de las Notarías Públicas y el Registro de la Propiedad del Cantón Mocache deberá considerar que la documentación que adjunta la administrada deberá estar vigente para el efecto

Los informes técnicos que se adjuntan, y que forman parte del presente criterio jurídico, son de absoluta responsabilidad de quienes los suscriben.

Particular que se emite, para los fines pertinentes.

Mocache, 02 de octubre 2023

Atentamente,

Ab. Rafael Ballesteros Vaca
PROCURADOR SÍNDICO MUNICIPAL

Elaborado por	Ab. Irwin Ruiseño Guevara
Aprobado por	Ab. Rafael Ballesteros Vaca

C. c. Archi.

GADM. DEL CANTON MOCACHE
CERTIFICO QUE ESTA COPIA ES IGUAL A SU ORIGINAL
SECRETARIO GENERAL

Escaneado con CamScanner

GOBIERNO AUTÓNOMO DESCENTRALIZADO MUNICIPAL
DEL CANTÓN MOCACHE
DIRECCIÓN DE ORDENAMIENTO TERRITORIAL
Y PLANEAMIENTO URBANO Y RURAL

Memorándum N° 0857 – DOTPUR- ZMA – 2023
Mocache, 14 de Septiembre de 2023

Ab. Rafael Ballesteros Vaca
PROCURADOR SÍNDICO MUNICIPAL
En su despacho.-

En atención a la solicitud # 2423, el 15 de Agosto de 2023, ingresada por Herederos Gómez Figueroa conformados por:

NOMBRE Y APELLIDOS	CI
Gómez Figueroa Terencia de Jesús	0909786535
Gómez Figueroa Julio Gregorio	0912744240
Gómez Figueroa Luis Francisco	1202559686
Gómez Figueroa Cleotilde Mercedes	0912753993
Gómez Figueroa Gregoria Gladys	1203560491
Gómez Figueroa Filadelfia Dolores	0912754009

Solicitando una Partición Extrajudicial y Adjudicación Voluntaria de dos lotes en el sector rural de BARRO COLORADO, a favor de:

Lote N°1 de 28.70 Has

NOMBRE Y APELLIDOS	AREA	
Gómez Figueroa Terencia de Jesus	2.0097 Has	2.0841 Has
Gómez Figueroa Julio Gregorio	1.7898 Has	2.4124 Has
Gómez Figueroa Cleotilde Mercedes	1.8347 Has	6.7020 Has
Gómez Figueroa Gregoria Gladys	1.6053 Has	6.7020 Has
Gómez Figueroa Filadelfia Dolores	1.7433 Has	-
Gómez Figueroa Luis Francisco	1.7975 Has	-
Guardarraya Pública	0.0192 has	
Total	28.70 has	

Lote N°2 de 7.7213 Has

NOMBRE Y APELLIDOS	AREA
Gómez Figueroa Terencia de Jesús	4.1941 Has
Gómez Figueroa Julio Gregorio	
Gómez Figueroa Luis Francisco	1.4106 Has
Gómez Figueroa Cleotilde Mercedes	
Gómez Figueroa Gregoria Gladys	2.1166 Has
Gómez Figueroa Filadelfia Dolores	
Total	**7.7213 Has**

GAD MUN. DEL CANTÓN MOCACHE
CERTIFICO QUE ESTA COPIA ES IGUAL A SU ORIGINAL
SECRETARIO GENERAL

Escaneado con CamScanner

GOBIERNO AUTÓNOMO DESCENTRALIZADO MUNICIPAL DEL CANTÓN MOCACHE

DIRECCIÓN DE ORDENAMIENTO TERRITORIAL Y PLANEAMIENTO URBANO Y RURAL

Una vez revisada toda la documentación presentada y los planos en físico y digital, Informe de regulación Rural, el Informe Técnico de campo # 168-2023, de acuerdo a lo expuesto detallo el siguiente Informe Técnico de Campo.

Informe Técnico:

Sector: BARRO COLORADO
Área Total: 28.70 Has

Datos de terreno	
AREA SEGUN REGISTRO:	**28.70 has**
ÁREA GRÁFICA:	**28.70 has**
AVALÚO:	$ 36.603,07
CLAVE CATASTRAL:	4846
ZONA:	Rural
SECTOR:	Barro Colorado

Linderos y Medidas del lote para partición extrajudicial y adjudicación voluntaria a favor de: Gómez Figueroa Terencia de Jesús con 2.0097 Has

NORTE Con Gómez Figueroa Julio Gregorio con 36.16m
SUR Con Litardo Aspiazu Paulino Antonio en 23.84m
ESTE Con Mendoza Aguirre Rodolfo en 103.11m; 107.04m; 500.32m
OESTE Con Gómez Figueroa Julio Gregorio en 485.86m; 210.81m

Linderos y Medidas del lote para partición extrajudicial y adjudicación voluntaria a favor de: Gómez Figueroa Terencia de Jesús con 2.0841 Has

NORTE Con Hdros Coque Aguirre en 76.28m
SUR Con Gómez Figueroa Terencia de Jesús en 94.18m
ESTE Con Hdros Coque Aguirre en 237.48m
OESTE Con Gómez Figueroa Cleotilde en 297.63m

Linderos y Medidas del lote para partición extrajudicial y adjudicación voluntaria a favor de: Gómez Figueroa Julio Gregorio con 1.7898 Has

NORTE Con Gomez Figueroa Julio en 30.15m
SUR Con Litardo Aspiazu Paulino Antonio en 21.92m
ESTE Con Gomez Figueroa Terencia en 210.81m, 485.87m
OESTE Con Gomez Figueroa Luis en 438.54m; 244.69m

Linderos y Medidas del lote para partición extrajudicial y adjudicación voluntaria a favor de: Gómez Figueroa Julio Gregorio con 2.4124 has

NORTE Con Gomez Figueroa Gregoria en 210.64m
SUR Con Gomez Figueroa Terencia de Jesus en 36.16m
Con Gomez Figueroa Julio en 30.15m
Con Gomez Figueroa Luis en 35.52m

GADM. DEL CANTON MOCACHE
CERTIFICO QUE ESTA COPIA ES IGUAL A SU ORIGINAL
SECRETARIO GENERAL

Escaneado con CamScanner

GOBIERNO AUTÓNOMO DESCENTRALIZADO MUNICIPAL DEL CANTÓN MOCACHE

DIRECCIÓN DE ORDENAMIENTO TERRITORIAL Y PLANEAMIENTO URBANO Y RURAL

	Con Gomez Figueroa Cleotilde en 35.85m
	Con Gómez Figueroa Filadelfia en 41.99m
	Con Gómez Figueroa Gregoria en 34.98m
ESTE	Con Gómez Candelario Ramón en 85.47m
OESTE	Con Litardo Aspiazu Paulino Antonio en 178.26m

Linderos y Medidas del lote para partición extrajudicial y adjudicación voluntaria a favor de: Gómez Figueroa Cleotilde Mercedes con 1.8347 has

NORTE	Con Gomez Figueroa Julio en 35.85m
SUR	Con Litardo Aspiazu Paulino Antonio en 24.23m
ESTE	Con Gómez Figueroa Luis en 322.18m; 343.77m
OESTE	Con Gómez Figueroa Filadelfia en 327.64m; 309.55

Linderos y Medidas del lote para partición extrajudicial y adjudicación voluntaria a favor de: Gómez Figueroa Cleotilde Mercedes con 6.7020 has

NORTE	Con Hdros Arreaga Giler en 54.63m; 44.09m; 53.39m
	Con María Arreaga Ronquillo en 64.28m
	Con Hdros Coque Aguirre en 33.33m; 49.39m; 28.52m; 32.70m
SUR	Con Gregoria Gómez Figueroa en 235.95m
ESTE	Con Terencia Gómez Figueroa en 297.63m
	Con Hdros Gómez Figueroa en 22.57m; 50.29m;
	Con Guardarraya Pública en 3.75m; 54.73m; 29.01m;
	Con Cruce de Guardarraya Pública en 4.29m
	Con Ramón Gómez en 150.08m; 100.32m; 88.2m; 29.39m
OESTE	Con Ramón Gómez Candelario en 85.63m; 48.05m; 69.64m
	Con Cruce de Guardarraya Pública en 4.42m
	Con Ramón Gómez Candelario en 49.22m; 88.92m; 98.74m; 52.42m; 19.47m

Linderos y Medidas del lote para partición extrajudicial y adjudicación voluntaria a favor de: Gómez Figueroa Gregoria Gladys en 1.6053 has

NORTE	Con Gómez Figueroa Julio en 34.98m
SUR	Con Litardo Aspiazu Paulino Antonio en 22.00m
ESTE	Con Gómez Figueroa Filadelfia en 284.81m; 316.12m
OESTE	Con Litardo Aspiazu Paulino Antonio en 303.65m; 273.83m

Linderos y Medidas del lote para partición extrajudicial y adjudicación voluntaria a favor de: Gómez Figueroa Gregoria Gladys en 6.7020 has

NORTE	Con Gómez Figueroa Cleotilde en 235.95m
SUR	Con Gómez Figueroa Julio en 210.64m
ESTE	Con Gómez Candelario Ramón en 46.64m; 33.79m; 75.78m; 14.14m; 6.43m; 23.53m
OESTE	Con Gómez Ramón en 102.73m; 13.93m; 23.01m; 36.69m; 21.30m; 42.87m; 43.04m; 41.75m; 20.80m

GADM DEL CANTÓN MOCACHE
CERTIFICO QUE ESTA COPIA ES IGUAL A SU ORIGINAL

SECRETARIO GENERAL

Escaneado con CamScanner

GOBIERNO AUTÓNOMO DESCENTRALIZADO MUNICIPAL DEL CANTÓN MOCACHE

DIRECCIÓN DE ORDENAMIENTO TERRITORIAL Y PLANEAMIENTO URBANO Y RURAL

Linderos y Medidas del lote para partición extrajudicial y adjudicación voluntaria a favor de: Gómez Figueroa Filadelfia Dolores en 1.7433 has

NORTE Con Gómez Figueroa Julio en 41.99m
SUR Con Litardo Aspiazu Paulino Antonio en 23.12m
ESTE Con Gómez Figueroa Cleotilde en 309.55m; 327.64m
OESTE Con Gómez Figueroa Gregoria en 316.12m; 284.81

Linderos y Medidas del lote para partición extrajudicial y adjudicación voluntaria a favor de: Gómez Figueroa Luis Francisco con 1.7975 has

NORTE Con Julio Gómez Figueroa en 35.52m
SUR Con Paulino Antonio Litardo Aspiazu en 23.01m
ESTE Con Julio Gómez Figueroa en 244.69m; 438.55m
OESTE Con Cleotilde Gómez Figueroa en 343.77m; 322.18m

Área de Guardarraya Pública 0.0192 has

Sector: BARRO COLORADO
Área Total: 7.7213 Has

Datos de terreno	
AREA SEGUN REGISTRO:	**7.7213 Has**
ÁREA GRÁFICA:	**7.7213 Has**
AVALÚO:	$ 29.577,60
CLAVE CATASTRAL:	3647
ZONA:	Rural
SECTOR:	Barro Colorado

Linderos y Medidas del lote para partición extrajudicial y adjudicación voluntaria a favor de: Terencia De Jesús Gómez Figueroa y Julio Gregorio Gómez Figueroa en 4.1941 has

NORTE Con Gómez Aguirre Eloy en 72.11m; 79.51m; 40.80m
SUR Con Luis Francisco Gómez Figueroa y Cleotilde Mercedes Gómez Figueroa en 184.90m
ESTE Con Castro Aguirre Verónica en 172.29m
Con Junco Coello Daniel en 41.30m
OESTE Con Guardarraya frente a Litardo Cadena Alberto en 21.81m; 19.92m; 103.17m; Con Litardo Cadena Alberto en 106.37m

NOTARIA SEXTA DEL CANTÓN MOCACHE PROV. DE LOS RÍOS CARLOS MENDOZA GARCÍA MS. NOTARIO TITULAR

GADM. DEL CANTÓN MOCACHE
CERTIFICO QUE ESTA COPIA ES IGUAL A SU ORIGINAL

SECRETARIO GENERAL

Escaneado con CamScanner

GOBIERNO AUTÓNOMO DESCENTRALIZADO MUNICIPAL DEL CANTÓN MOCACHE

DIRECCIÓN DE ORDENAMIENTO TERRITORIAL Y PLANEAMIENTO URBANO Y RURAL

Linderos y Medidas del lote para partición extrajudicial y adjudicación voluntaria a favor de: Luis Francisco Gómez Figueroa y Cleotilde Mercedes Gómez Figueroa en 1.4106 Has

NORTE	Con Terancia De Jesús Gómez Figueroa y Julio Gregorio Gómez Figueroa en 184.90m
SUR	Con Filadelfia Gómez Figueroa y Gregoria Gladys Gómez Figueroa en 241.70m
ESTE	Con Junco Coello Daniel en 58.22m
OESTE	Con Guillen Castro Marco en 13.58m Con Guardarraya frente a Litardo Cadena Alberto en 39.40m; 28.26m; 22.39m

Linderos y Medidas del lote para partición extrajudicial y adjudicación voluntaria a favor de: Filadelfia Gómez Figueroa y Gregoria Gladys Gómez Figueroa en 2.1166 Has

NORTE	Con Luis Francisco Gómez Figueroa y Cleotilde Mercedes Gómez Figueroa en 241.70m
SUR	Con Aguirre Franco Julia en 46.10m; Con Vera Alvarado Lorenzo en 5.83m; 36.00m; 63.24m Con Aguirre Franco Teofilo en 68.14m
ESTE	Con Figueroa Bajaña Julia en 83.96m
OESTE	Con Guillen Castro Marco en 64.51m; 40.65m

Ante lo expuesto debo mencionar que luego de haber realizado la inspección en el sitio, por el Arq. Carlos Sinchiguano Barahona. Analista de Avalúos y Catastro. El 14/09/2023, los planos se ajustan a las medidas y coordenadas, por lo tanto el presente Informe es favorable técnicamente, Constatando que en el sitio se encuentra y sembrío de ciclo corto, siendo favorable técnicamente para uso agrícola, consecuentemente sírvase emitir su criterio jurídico al respecto.

De acuerdo a la ordenanza que aprueba el plan de desarrollo y ordenamiento territorial del cantón Mocache 2021-2023, y el plan de uso y gestión de suelo del Cantón Mocache 2021-2023 acogiéndonos al capítulo III compatibilidad, ocupación y edificabilidad, art 43 y tabla N° 6 usos generales y específicos de suelo rural, los predios para partición extrajudicial y adjudicación voluntaria serán de uso Agrícola.

Atentamente

PhD. Zoila Merino Acosta, Ing.
DIRECTORA DE ORDENAMIENTO TERRITORIAL Y PLANEAMIENTO URBANO Y RURAL
c.c arch
Arq. Carlos Sinchiguano

GADM DEL CANTÓN MOCACHE
EL SUSCRITO QUE ESTA COPIA ES IGUAL A SU ORIGINAL
SECRETARIO GENERAL

Escaneado con CamScanner

Mocache, 14 de Septiembre de 2023

PARA: Phd. Zoila Merino Acosta, Ing.
DE: Arq. Carlos Sinchiguano B. – Analista de Avalúos y Catastro
ASUNTO: Informe Técnico

INFORME TÉCNICO DE CAMPO No. 168-2023

Provincia: Los Ríos
Cantón: Mocache
Parroquia: Mocache
Sector: BARRO COLORADO
No. De Solicitud: 2423
Ingreso de Solicitud: 15 de Agosto de 2023
Nombre del Solicitante: Herederos Gómez Figueroa
Fecha de Inspección: 14-09-2023
Hora de Inspección: 11:00 am

Se procedió a inspeccionar 2 lotes a nombre de Herederos Gómez Figueroa conformado por

NOMBRE Y APELLIDOS	CI
Gómez Figueroa Terencia de Jesús	0909786535
Gómez Figueroa Julio Gregorio	0912744240
Gómez Figueroa Luis Francisco	1202559686
Gómez Figueroa Cleotilde Mercedes	0912753993
Gómez Figueroa Gregoria Gladys	1203580491
Gómez Figueroa Filadelfia Dolores	0912754009

Solicitando una Partición Extrajudicial y Adjudicación Voluntaria de dos lotes en el sector rural de BARRO COLORADO, a favor de:

Lote N°1 de 28.70 Has

NOMBRE Y APELLIDOS	AREA	
Gómez Figueroa Terencia de Jesús	2.0097 Has	2.0841 Has
Gómez Figueroa Julio Gregorio	1.7898 Has	2.4124 Has
Gómez Figueroa Cleotilde Mercedes	1.8347 Has	6.7020 Has
Gómez Figueroa Gregoria Gladys	1.6053 Has	6.7020 Has
Gómez Figueroa Filadelfia Dolores	1.7433 Has	-
Gómez Figueroa Luis Francisco	1.7975 Has	-
Guardarraya Pública	0.0192 has	
Total	28.70 has	

Lote N°2 de 7.7213 Has

NOMBRE Y APELLIDOS	AREA
Gómez Figueroa Terencia de Jesús	4.1941 Has
Gómez Figueroa Julio Gregorio	
Gómez Figueroa Luis Francisco	1.4106 Has
Gómez Figueroa Cleotilde Mercedes	
Gómez Figueroa Gregoria Gladys	2.1166 Has
Gómez Figueroa Filadelfia Dolores	
Total	**7.7213 Has**

GAD. DEL CANTON MOCACHE
CERTIFICO QUE ESTA COPIA ES IGUAL A SU ORIGINAL
SECRETARIO GENERAL

Escaneado con CamScanner

Una vez revisada toda la documentación presentada y los planos en físico y digital, emito el siguiente Informe Técnico de Campo, el cual detallo a continuación:

Informe Técnico:

Sector:	BARRO COLORADO
Área Total:	28.70 Has

Linderos y Medidas del lote para partición extrajudicial y adjudicación voluntaria a favor de: Gómez Figueroa Terencia de Jesús con 2.0097 Has

NORTE	Con Gómez Figueroa Julio Gregorio con 36.16m
SUR	Con Litardo Aspiazu Paulino Antonio en 23.84m
ESTE	Con Mendoza Aguirre Rodolfo en 103.11m; 107.04m; 500.32m
OESTE	Con Gómez Figueroa Julio Gregorio en 485.86m; 210.81m

Linderos y Medidas del lote para partición extrajudicial y adjudicación voluntaria a favor de: Gómez Figueroa Terencia de Jesús con 2.0841 Has

NORTE	Con Hdros Coque Aguirre en 76.28m
SUR	Con Gómez Figueroa Terencia de Jesús en 94.18m
ESTE	Con Hdros Coque Aguirre en 237.48m
OESTE	Con Gómez Figueroa Cleotilde en 297.63m

Linderos y Medidas del lote para partición extrajudicial y adjudicación voluntaria a favor de: Gómez Figueroa Julio Gregorio con 1.7898 Has

NORTE	Con Gomez Figueroa Julio en 30.15m
SUR	Con Litardo Aspiazu Paulino Antonio en 21.92m
ESTE	Con Gomez Figueroa Terencia en 210.81m; 485.87m
OESTE	Con Gomez Figueroa Luis en 438.54m; 244.69m

Linderos y Medidas del lote para partición extrajudicial y adjudicación voluntaria a favor de: Gómez Figueroa Julio Gregorio con 2.4124 has

NORTE	Con Gomez Figueroa Gregoria en 210.64m
SUR	Con Gomez Figueroa Terencia de Jesus en 36.16m
	Con Gomez Figueroa Julio en 30.15m
	Con Gomez Figueroa Luis en 35.52m
	Con Gomez Figueroa Cleotilde en 35.85m
	Con Gómez Figueroa Filadelfia en 41.99m
	Con Gómez Figueroa Gregoria en 34.98m
ESTE	Con Gómez Candelario Ramón en 85.47m
OESTE	Con Litardo Aspiazu Paulino Antonio en 178.26m

Linderos y Medidas del lote para partición extrajudicial y adjudicación voluntaria a favor de: Gómez Figueroa Cleotilde Mercedes con 1.8347 has

NORTE	Con Gomez Figueroa Julio en 35.85m
SUR	Con Litardo Aspiazu Paulino Antonio en 24.23m
ESTE	Con Gómez Figueroa Luis en 322.18m; 343.77m
OESTE	Con Gómez Figueroa Filadelfia en 327.64m; 309.55

GADM. DEL CANTON MOCACHE
CERTIFICO QUE ESTA COPIA ES IGUAL A SU ORIGINAL
SECRETARIO GENERAL

www.mocache.gob.ec |

Escaneado con CamScanner

Linderos y Medidas del lote para partición extrajudicial y adjudicación voluntaria a favor de: Gómez Figueroa Cleotilde Mercedes con 6.7020 has

NORTE	Con Hdros Arreaga Giler en 54.63m; 44.09m; 53.39m Con María Arreaga Ronquillo en 64.28m Con Hdros Coque Aguirre en 33.33m; 49.39m; 28.52m; 32.70m
SUR	Con Gregoria Gómez Figueroa en 235.95m
ESTE	Con Terencia Gómez Figueroa en 297.63m Con Hdros Gómez Figueroa en 22.57m; 50.29m; Con Guardarraya Pública en 3.75m; 54.73m; 29.01m; Con Cruce de Guardarraya Pública en 4.29m Con Ramón Gómez en 158.08m; 100.32m; 88.2m; 29.39m
OESTE	Con Ramón Gómez Candelario en 85.63m; 48.05m; 69.64m Con Cruce de Guardarraya Pública en 4.42m Con Ramón Gómez Candelario en 49.22m; 88.92m; 98.74m; 52.42m; 19.47m

Linderos y Medidas del lote para partición extrajudicial y adjudicación voluntaria a favor de: Gómez Figueroa Gregoria Gladys en 1.6053 has

NORTE	Con Gómez Figueroa Julio en 34.98m
SUR	Con Litardo Aspiazu Paulino Antonio en 22.00m
ESTE	Con Gómez Figueroa Filadelfia en 284.81m; 316.12m
OESTE	Con Litardo Aspiazu Paulino Antonio en 303.65m; 273.83m

Linderos y Medidas del lote para partición extrajudicial y adjudicación voluntaria a favor de: Gómez Figueroa Gregoria Gladys en 6.7020 has

NORTE	Con Gómez Figueroa Cleotilde en 235.95m
SUR	Con Gómez Figueroa Julio en 210.64m
ESTE	Con Gómez Candelario Ramón en 46.64m; 33.70m; 75.78m; 14.14m; 6.43m; 23.53m
OESTE	Con Gómez Ramón en 102.73m; 13.93m; 23.01m; 36.69m; 21.30m; 42.87m; 43.04m; 41.75m; 20.80m

Linderos y Medidas del lote para partición extrajudicial y adjudicación voluntaria a favor de: Gómez Figueroa Filadelfia Dolores en 1.7433 has

NORTE	Con Gómez Figueroa Julio en 41.99m
SUR	Con Litardo Aspiazu Paulino Antonio en 23.12m
ESTE	Con Gómez Figueroa Cleotilde en 309.55m; 327.64m
OESTE	Con Gómez Figueroa Gregoria en 316.12m; 284.81

Linderos y Medidas del lote para partición extrajudicial y adjudicación voluntaria a favor de: Gómez Figueroa Luis Francisco con 1.7975 has

NORTE	Con Julio Gómez Figueroa en 35.52m
SUR	Con Paulino Antonio Litardo Aspiazu en 23.01m
ESTE	Con Julio Gómez Figueroa en 244.69m; 438.55m
OESTE	Con Cleotilde Gómez Figueroa en 343.77m; 322.18m

GADM DEL CANTON MOCACHE
CERTIFICO QUE ESTA COPIA ES IGUAL A SU ORIGINAL
SECRETARIO GENERAL

Escaneado con CamScanner

Área de Guardarraya Pública 0.0192 has

Sector: BARRO COLORADO
Área Total: 7.7213 Has

Linderos y Medidas del lote para partición extrajudicial y adjudicación voluntaria a favor de: Terencia De Jesús Gómez Figueroa y Julio Gregorio Gómez Figueroa en 4.1941 has

NORTE Con Gómez Aguirre Eloy en 72.11m; 79.51m; 40.80m
SUR Con Luis Francisco Gómez Figueroa y Cleotilde Mercedes Gómez Figueroa en 184.90m
ESTE Con Castro Aguirre Verónica en 172.29m
Con Junco Coello Daniel en 41.30m
OESTE Con Guardarraya frente a Litardo Cadena Alberto en 21.81m; 19.92m; 103.17m
Con Litardo Cadena Alberto en 106.37m

Linderos y Medidas del lote para partición extrajudicial y adjudicación voluntaria a favor de: Luis Francisco Gómez Figueroa y Cleotilde Mercedes Gómez Figueroa en 1.4106 Has

NORTE Con Terencia De Jesús Gómez Figueroa y Julio Gregorio Gómez Figueroa en 184.90m
SUR Con Filadelfia Gómez Figueroa y Gregoria Gladys Gómez Figueroa en 241.70m
ESTE Con Junco Coello Daniel en 58.22m
OESTE Con Guillen Castro Marco en 13.58m
Con Guardarraya frente a Litardo Cadena Alberto en 39.40m; 28.28m; 22.39m

Linderos y Medidas del lote para partición extrajudicial y adjudicación voluntaria a favor de: Filadelfia Gómez Figueroa y Gregoria Gladys Gómez Figueroa en 2.1166 Has

NORTE Con Luis Francisco Gómez Figueroa y Cleotilde Mercedes Gómez Figueroa en 241.70m
SUR Con Aguirre Franco Julia en 46.10m;
Con Vera Alvarado Lorenzo en 5.83m; 36.00m; 63.24m
Con Aguirre Franco Teofilo en 68.14m
ESTE Con Figueroa Bajaña Julia en 88.96m
OESTE Con Guillen Castro Marco en 64.51m; 40.65m

GADM DEL CANTON MOCACHE
SE CERTIFICO QUE ESTA COPIA ES
IGUAL A SU ORIGINAL
SECRETARIO GENERAL

Escaneado con CamScanner

RESPALDO FOTOGRÁFICO DE INSPECCIÓN



Informo que luego de revisada la documentación y de haber realizado la inspección, los planos se ajustan a las medidas y coordenadas las mismas que fueron verificadas en sitio; el 14/09/2023. En los predios a desmembrar se encontraron plantaciones de ciclo corto

De acuerdo a la ordenanza que aprueba el plan de desarrollo y ordenamiento territorial del cantón Mocache 2021-2023, y el plan de uso y gestión de suelo del Cantón Mocache 2021-2023 acogiéndonos al capítulo III compatibilidad, ocupación y edificabilidad, art 43 y tabla N° 6 usos generales y específicos de suelo rural, los predios desmembración serán de uso Agrícola, siendo posterior a inspección, favorable técnicamente.
Particular que le comunico para los fines pertinentes.

Atentamente

Arq. Carlos Sinchiguano B.
Analista de Avalúos y Catastro
c.c arch

GADM. DEL CANTÓN MOCACHE
CERTIFICO QUE ESTA COPIA ES IGUAL A SU ORIGINAL
SECRETARIO GENERAL

Escaneado con CamScanner

NFORME DE REGULACION URBANA Y RURAL

GADM MOCACHE

Mocache
ALCALDÍA CIUDADANA

INFORMACION PREDIAL

INFORME DE REGULACION URBANA Y RURAL No. 150-2023

DATOS TITULAR DE DOMINIO	
C.C/RUC	1201046131
Nombre o Razón Social	Julio Alberto Gomez Candelario
Numero de predio:	4846
Clave catastral anterior:	4846
En derechos y acciones:	28,70 has
AREAS DE CONSTRUCCION	
Area de construcción cubierta:	0,00m
Area de construcción abierta:	0,00m
Área bruta total de construcción	0,00m
AREA DEL PREDIO	
Area según escritura:	28,70 has
Area grafica:	28,70 has
Frente total:	-
Maximo ETAM permitido:	15%
Zona	RURAL
Barrio/Sector:	BARRO COLORADO

VIAS		
Nombre	Ancho	Referencia
Guardarraya S/n	7,00m	3,50 m AL EJE DE VIA

REGULACIONES		
Zona	Rural	Retiro Frontal : 5,00 m.
Lote Minimo	150,00 M2	Retiro Lateral 1 0,00 m
Frente Minimo		Retiro Lateral 2 : 0,00m
COS PB	0%	Retiro Posterior :
COS TOTAL	0%	Entre Bloques
Forma de Ocupación del Suelo	AGRICOLA	Clasificación de Uso de Suelo. AGRICOLA
Uso del Suelo	AGRICOLA	Factibilidad de Servicios: NO
Pisos	-	
Altura de Construcción	-	

Pisos

EL PREDIO EN MENCION NO TIENE NINGUNA AFECTACION

OBSERVACIONES

EL PRESENTE CERTIFICADO SE EXPIDIO EL 18 DE SEPTIEMBRE DE 2023

NOTAS

Los datos aquí representados están referidos al PUOUS e instrumentos de planificación complementarios, vigentes

Este informe no representa título legal alguno que perjudique a terceros.

Este informe no autoriza ningún trabajo de construcción o division de lotes, tampoco autoriza el funcionamiento de actividad alguna

"ETAM" es el "Error Técnico Aceptable de Medición", expresado en porcentaje y m2, que se acepta entre el área establecida en El Título de Propiedad (escritura), y la superficie del lote de terreno proveniente de la medición realizada por el GADMM, dentro del proceso de regularización de excedentes y diferencias de superficies, conforme lo establecido en el Artículo 481.1 del COOTAD

Este informe tendrá validez durante el tiempo de vigencia de UN AÑO

Para iniciar cualquier proceso de habilitación de la edificación del suelo o actividad, se deberá obtener el IRU respectivo

PHD. Zoila Merino Acosta, Ing.

DIRECTORA DE ORDENAMIENTO TERRITORIAL Y PLANEAMIENTO URBANO Y RURAL

Escaneado con CamScanner

NFORME DE REGULACION URBANA Y RURAI

GADM MOCACHE

Mocache
ALCALDÍA CIUDADANA

INFORMACION PREDIAL

INFORME DE REGULACION URBANA Y RURAL No. 149-2023

DATOS TITULAR DE DOMINIO	
C.C/RUC	1201045131
Nombre o Razón Social	Julio Alberto Gomez Candelario
Numero de predio:	3647
Clave catastral anterior:	3647
En derechos y acciones:	7,7213 has
AREAS DE CONSTRUCCION	
Area de construcción cubierta:	0,00m
Area de construcción abierta:	0,00m
Area bruta total de construcción	0,00m
AREA DEL PREDIO	
Area según escritura:	7,7213 has
Area gráfica:	7,7213 has
Frente total:	-
Máximo ETAM permitido:	15%
Zona:	RURAL
Barrio/Sector:	BARRIO COLORADO

VIAS

Nombre	Ancho	Referencia
Guardarraya S/n	7,00m	3,50 m AL EJE DE VIA

REGULACIONES

Zona	Rural	Retiro Frontal : 5,00 m.
Lote Mínimo	150,00 M2	Retiro Lateral 1 0,00 m
Frente Mínimo		Retiro Lateral 2 : 0,00m
COS PB	0%	Retiro Posterior :
COS TOTAL	0%	Entre Bloques
Forma de Ocupación del Suelo	AGRICOLA	Clasificación de Uso de Suelo AGRÍCOLA
Uso del Suelo	AGRICOLA	Factibilidad de Servicios: NO
Pisos	-	
Altura de Construcción	-	

Pisos

EL PREDIO EN MENCION NO TIENE NINGUNA AFECTACION

OBSERVACIONES

EL PRESENTE CERTIFICADO SE EXPIDIO EL 18 DE SEPTIEMBRE DE 2023

NOTAS

Los datos aquí representados están atenidos al PUOUS e instrumentos de planificación complementarios, vigentes

Este informe no representa título legal alguno que perjudique a terceros.

Este informe no autoriza ningún trabajo de construcción o división de lotes, tampoco autoriza el funcionamiento de actividad alguna

"ETAM" es el "Error Técnico Aceptable de Medición", expresado en porcentaje y m2, que se acepta entre el área establecida en El Título de Propiedad (escritura), y la superficie del lote de terreno proveniente de la medición realizada por el GADMM, dentro del proceso de regularización de excedentes y diferencias de superficies, conforme lo establecido en el Artículo 431.1 del COOTAD

Este informe tendrá validez durante el tiempo de vigencia de UN AÑO

Para iniciar cualquier proceso de habilitación de la edificación del suelo o actividad, se deberá obtener el IRU respectivo

PhD. Zoila Marina Acosta, Ing.

DIRECTORA DE ORDENAMIENTO TERRITORIAL Y PLANEAMIENTO URBANO Y RURAL

GADM DEL CANTON MOCACHE
EL SUSCRITO DEL CANTON MOCACHE
RURAL SUBROGANTE
SECRETARIO GENERAL

Escaneado con CamScanner

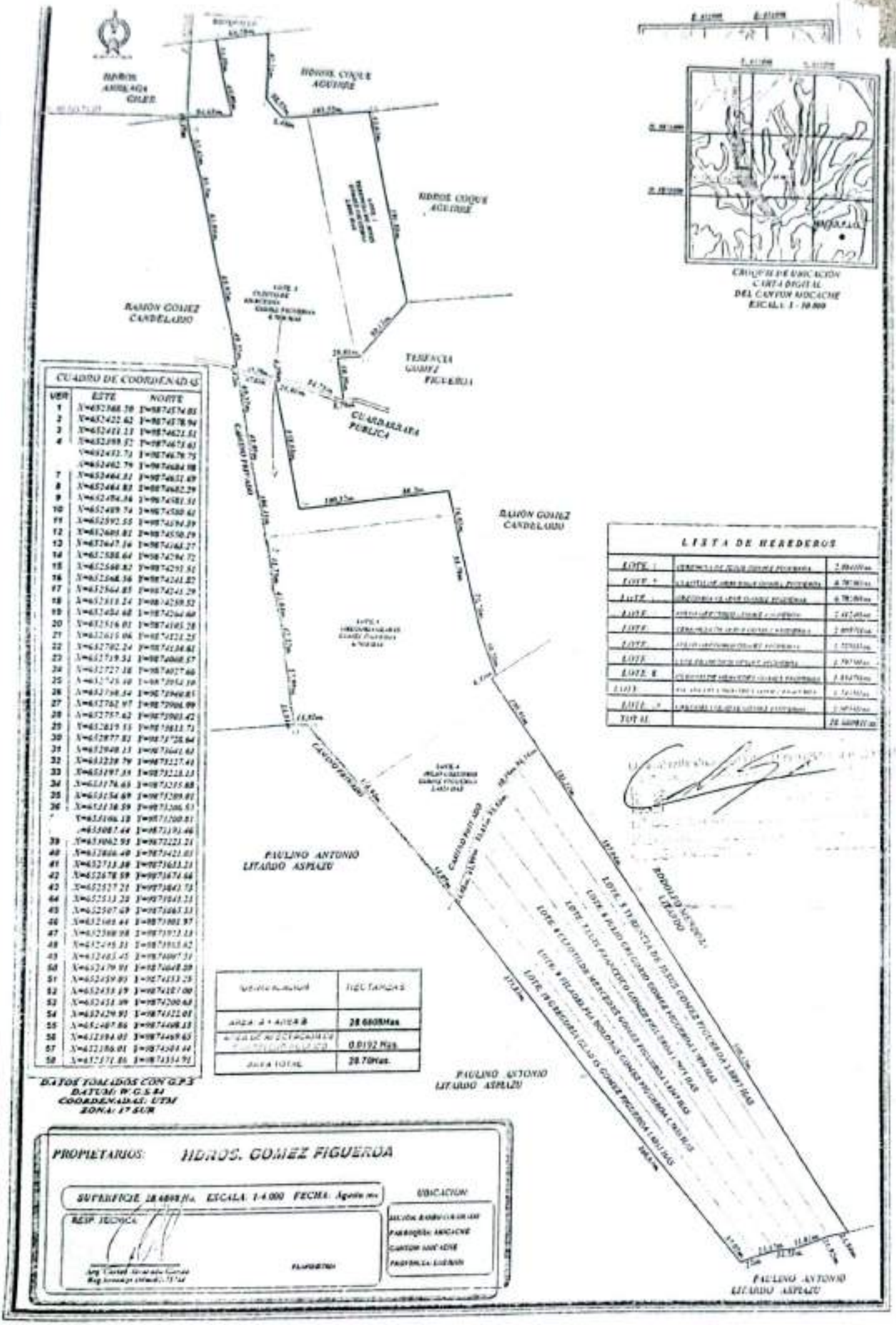

Escaneado con CamScanner

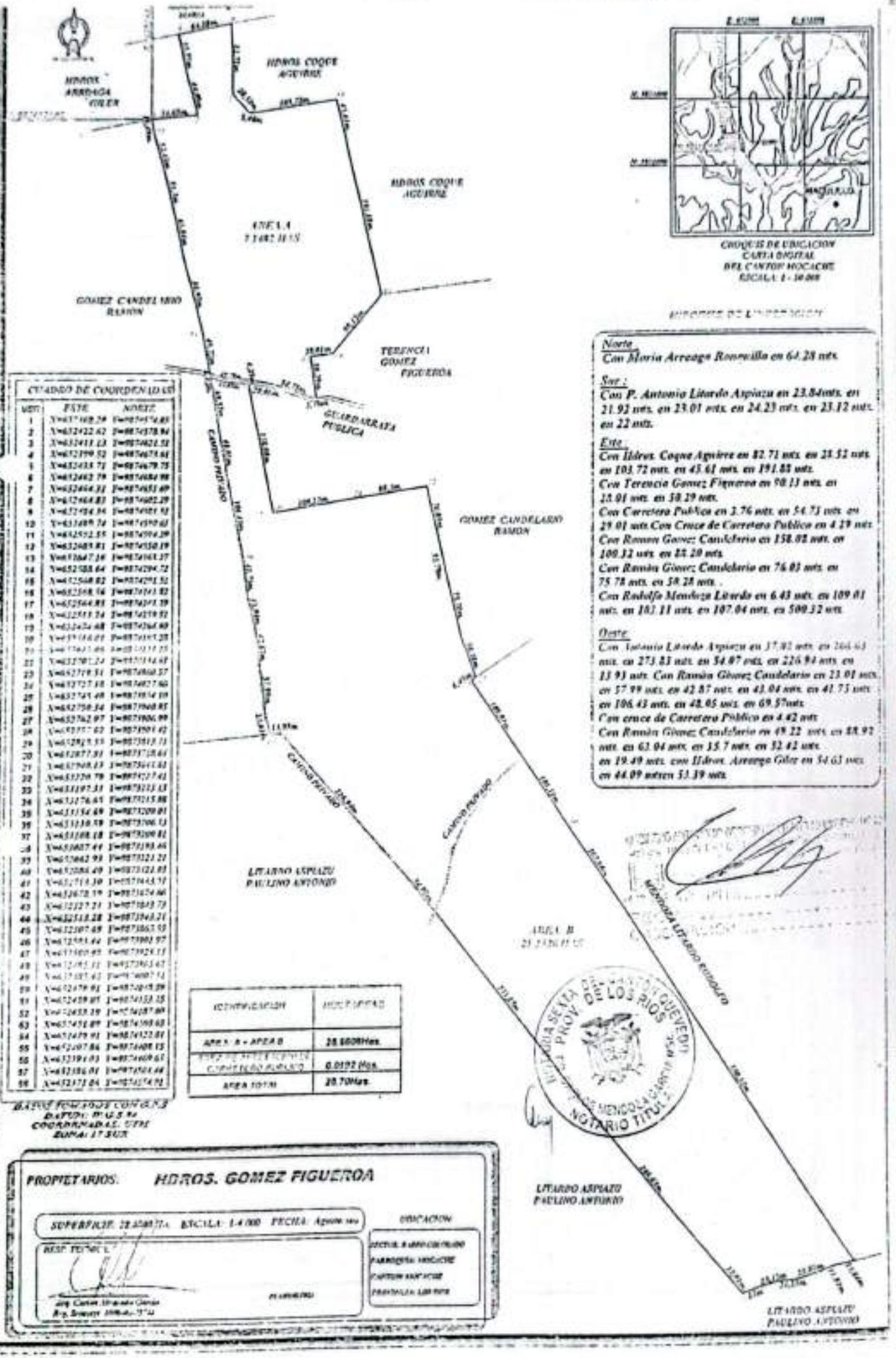

Escaneado con CamScanner

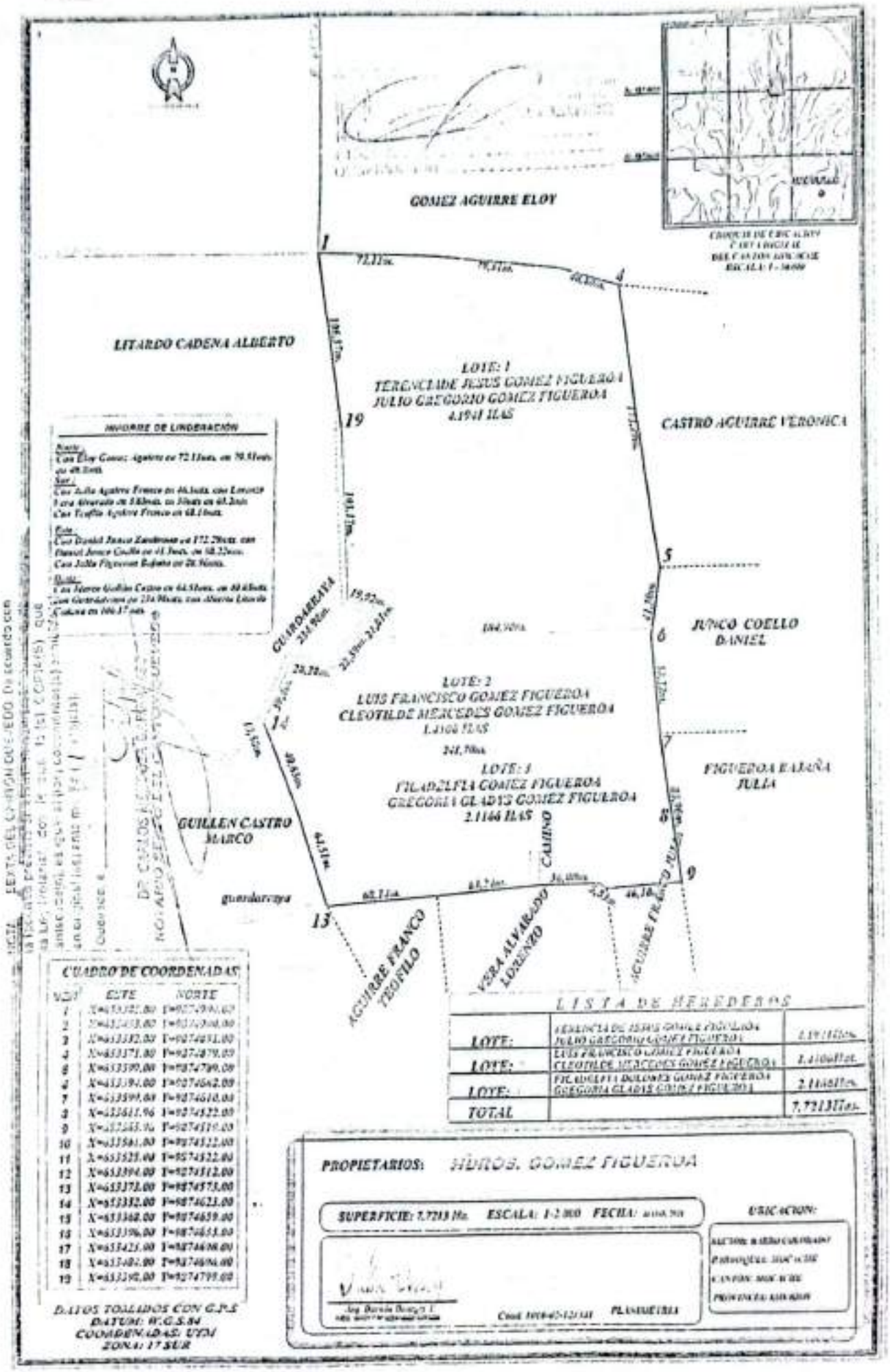
GOMEZ AGUIRRE ELOY
LITARDO CADENA ALBERTO
LOTE: 1
TERENCIA DE JESUS GOMEZ FIGUEROA
JULIO GREGORIO GOMEZ FIGUEROA
4.1941 HAS
CASTRO AGUIRRE VERONICA
JUNCO COELLO DANIEL
LOTE: 2
LUIS FRANCISCO GOMEZ FIGUEROA
CLEOTILDE MERCEDES GOMEZ FIGUEROA
1.4106 HAS
LOTE: 3
FILADELFIA GOMEZ FIGUEROA
GREGORIA GLADYS GOMEZ FIGUEROA
2.1166 HAS
FIGUEROA BAJAÑA JULIA
GUILLEN CASTRO MARCO
guardarraya
CAMINO
AGUIRRE FRANCO TEOFILO
VERA ALVARADO LORENZO
AGUIRRE FRANCO JULIO
INFORME DE LINDERACIÓN
CUADRO DE COORDENADAS
ESTE
NORTE
DATOS TOMADOS CON G.P.S
DATUM: W.G.S.84
COORDENADAS: UTM
ZONA: 17 SUR
LISTA DE HEREDEROS
LOTE:
LOTE:
LOTE:
TOTAL
PROPIETARIOS: HDROS. GOMEZ FIGUEROA
SUPERFICIE: 7.7213 Ha.
ESCALA: 1-2.000
FECHA:
UBICACION:
PLANIMETRIA

N: 9874584.25

HDROS. COQUE AGUIRRE

76,28m.

237,48m.

LOTE. 1
GOMEZ FIGUEROA
TERENCIA DE JESUS

297,63m.

LOTE. 2
GOMEZ FIGUEROA
CLEOTILDE

94,18m.

GOMEZ FIGUEROA
TERENCIA DE JESUS

HDROS. COQUE AGUIRRE

CARTA DIGITAL
DEL CANTON SUCUMBIOS
ESCALA 1 : 50.000

INFORME DE LINDEPACIÓN

Norte:
Con Hdros. Coque Aguirre en 76,28mts.

Sur:
Con Terencia Gomez Figueroa en 94,18mts.

Este:
Con Hdros. Coque Aguirre en 237,48mts.

Oeste:
Con Lote 2 de Cleotilde Gomez Figueroa en 297,63mts.

VER	ESTE	NORTE
1	X=652516.95	Y=9874584.25
2	X=652592.55	Y=9874504.30
3	X=652603.81	Y=9874550.13
4	X=652647.16	Y=9874363.26
5	X=652588.64	Y=9874294.71
6	X=652523.24	Y=9874291.69

DATOS TOMADOS CON GPS
DATUM: W.G.S. 84
COORDENADAS: UTM
ZONA: 17 SUR

PROPIETARIOS:
Documento a favor de:
TERENCIA DE JESUS GOMEZ FIGUEROA

SUPERFICIE: [illegible] m² ESCALA: 1:1500 FECHA: Agosto 2008

RESP. TECNICA
Arq. Carlos Alberto Garcia
Reg. Senescyt 1006-02-75744
PLANIMETRA

UBICACION
SECTOR: BARRIO COLORADO
PARROQUIA: NUEVO ROCAFUERTE
CANTON:
PROVINCIA: LOS RIOS

Escaneado con CamScanner

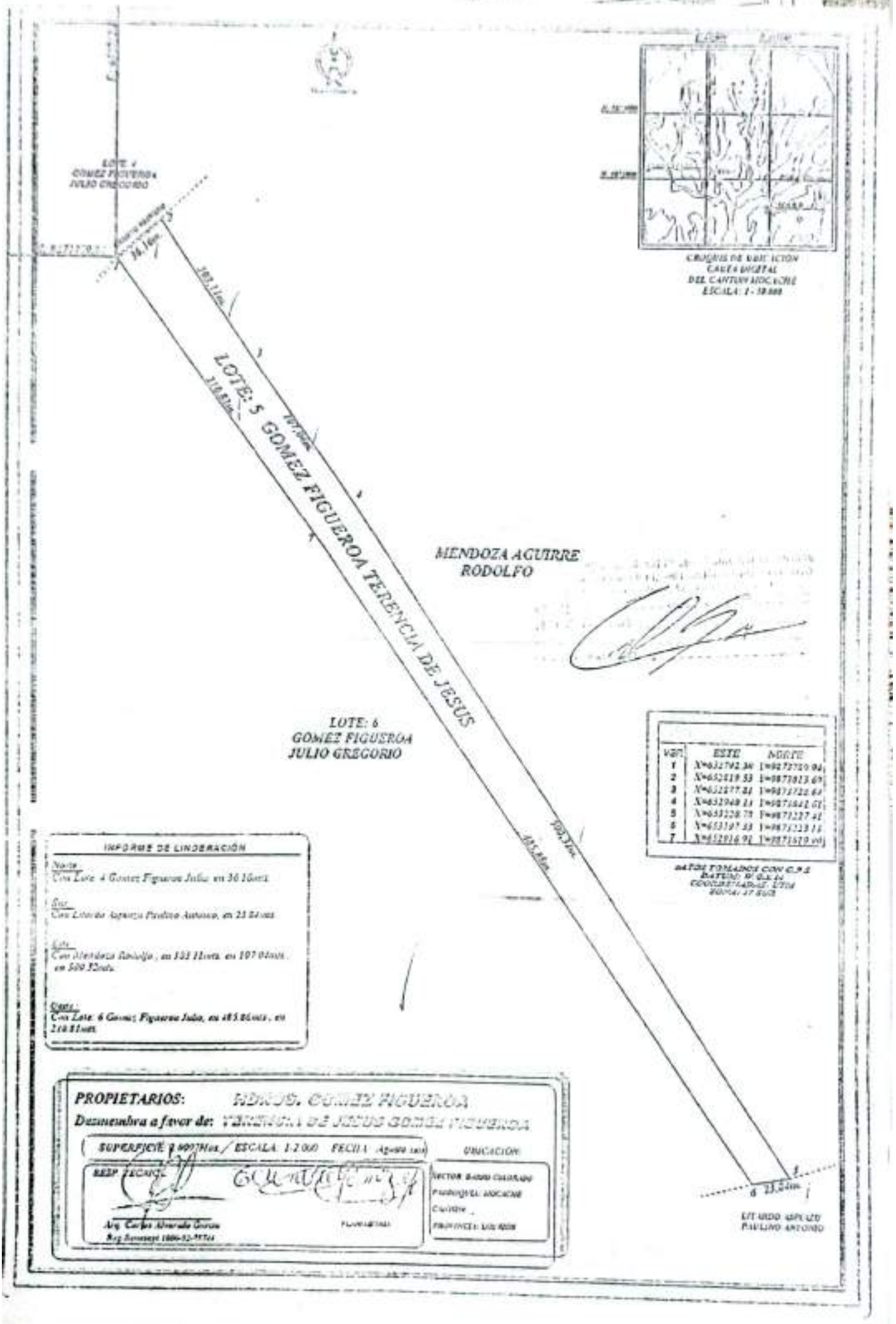

VER.	ESTE	NORTE
1	X=632792.36	Y=9873720.94
2	X=652819.53	Y=9873813.69
3	X=652877.81	Y=9873722.64
4	X=652948.13	Y=9873642.61
5	X=653228.78	Y=9873227.41
6	X=653197.33	Y=9873223.13
7	X=652916.92	Y=9873619.00

DATOS TOMADOS CON G.P.S.
DATUM: W.G.S.84
COORDENADAS: UTM
ZONA: 17 SUR

Escaneado con CamScanner

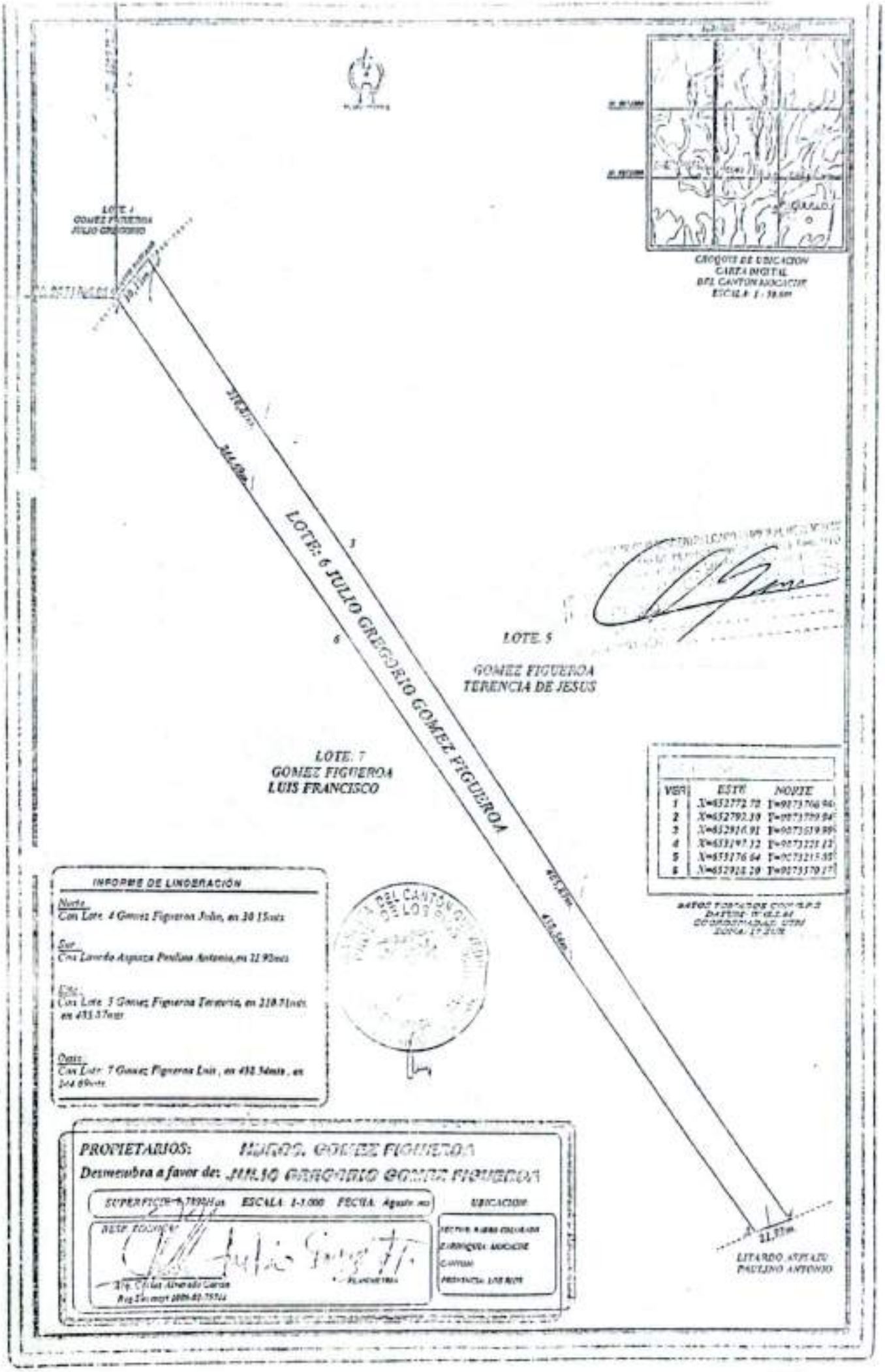

Escaneado con CamScanner

LOTE: 3
GOMEZ FIGUEROA
GREGORIA

GOMEZ CANDELARIO
RAMON

LOTE. 4
GOMEZ FIGUEROA
JULIO GREGORIO

LITARDO ASPIAZU
FAULINO ANTONIO

CAMINO PRIVADO

210,64m.

85,47m.

178,26m.

36,16m.

30,15m.

35,52m.

35,85m.

41,99m.

34,98m.

LOTE:5
GOMEZ FIGUEROA
TERENCIA DE JESUS

LOTE: 6
GOMEZ FIGUEROA
JULIO

LOTE: 7
GOMEZ FIGUEROA
LUIS

LOTE: 8
GOMEZ FIGUEROA
CLEOTILDE

LOTE: 9
GOMEZ FIGUEROA
FILADELFIA

LOTE: 10
GOMEZ FIGUEROA
GREGORIA

1

2

3

11

E: 652525,7

N: 9873767,2

CROQUIS DE UBICACION
CARTA DIGITAL
DEL CANTON MOCACHE
ESCALA: 1 - 50.000

VERT	ESTE	NORTE
1	[illegible]	[illegible]
2	[illegible]	[illegible]
3	[illegible]	[illegible]
4	[illegible]	[illegible]
5	[illegible]	[illegible]
6	[illegible]	[illegible]
7	[illegible]	[illegible]
8	[illegible]	[illegible]
9	[illegible]	[illegible]
10	[illegible]	[illegible]

PUNTOS TOMADOS CON GPS
DATUM WGS84
COORDENADAS UTM
ZONA 17 SUR

INFORME DE LINDERACION

Norte:
Con Lote: 3 Gomez Figueroa Gregoria, en 210.64mts.

Sur:
Con Lote: 5 Gomez Figueroa Terencia, en 36.16mts
Con Lote: 6 Gomez Figueroa Julio, en 30.15mts
Con Lote: 7 Gomez Figueroa Luis, en 35.52mts
Con Lote: 8 Gomez Figueroa Cleotilde, en 35.85mts
Con Lote: 9 Gomez Figueroa Filadelfia, en 41.99mts
Con Lote: 10 de Gomez Figueroa Gregoria, en 34.98mts

Este:
Con: Gomez Candelario Ramon, en 85.47mts.

Oeste:
Con Litardo Aspiazu Paulino Antonio y camino de por medio en 178.26mts.

PROPIETARIO:

SUPERFICIE: 4[illegible]ha. ESCALA: 1-1.500 FECHA: Agosto, 2011

UBICACION:

RESP. TECNICA:

Ing. Carlos Granado Garcia
Reg. [illegible]

PROVINCIA:
CANTON:
PARROQUIA:

Escaneado con CamScanner

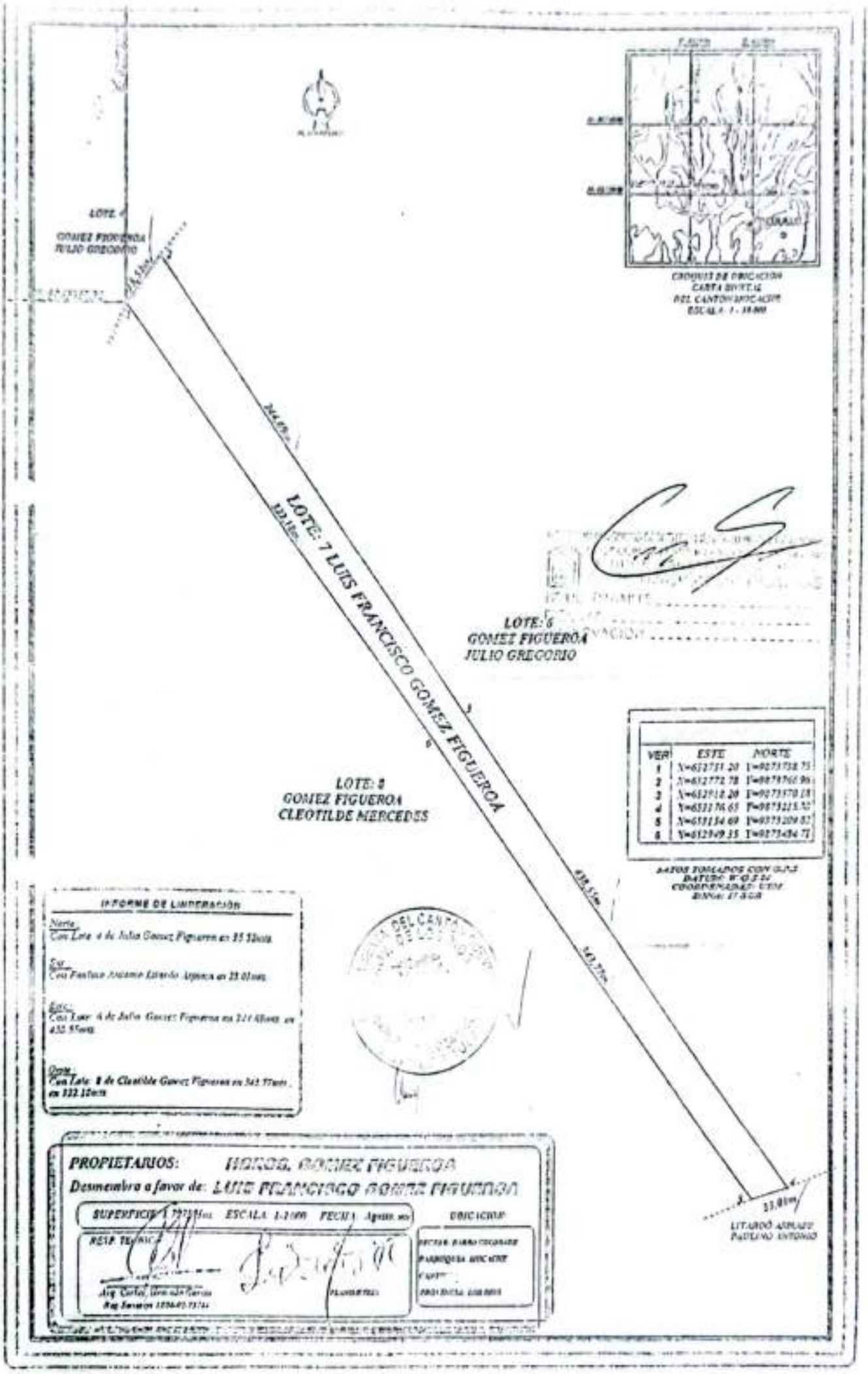

Escaneado con CamScanner

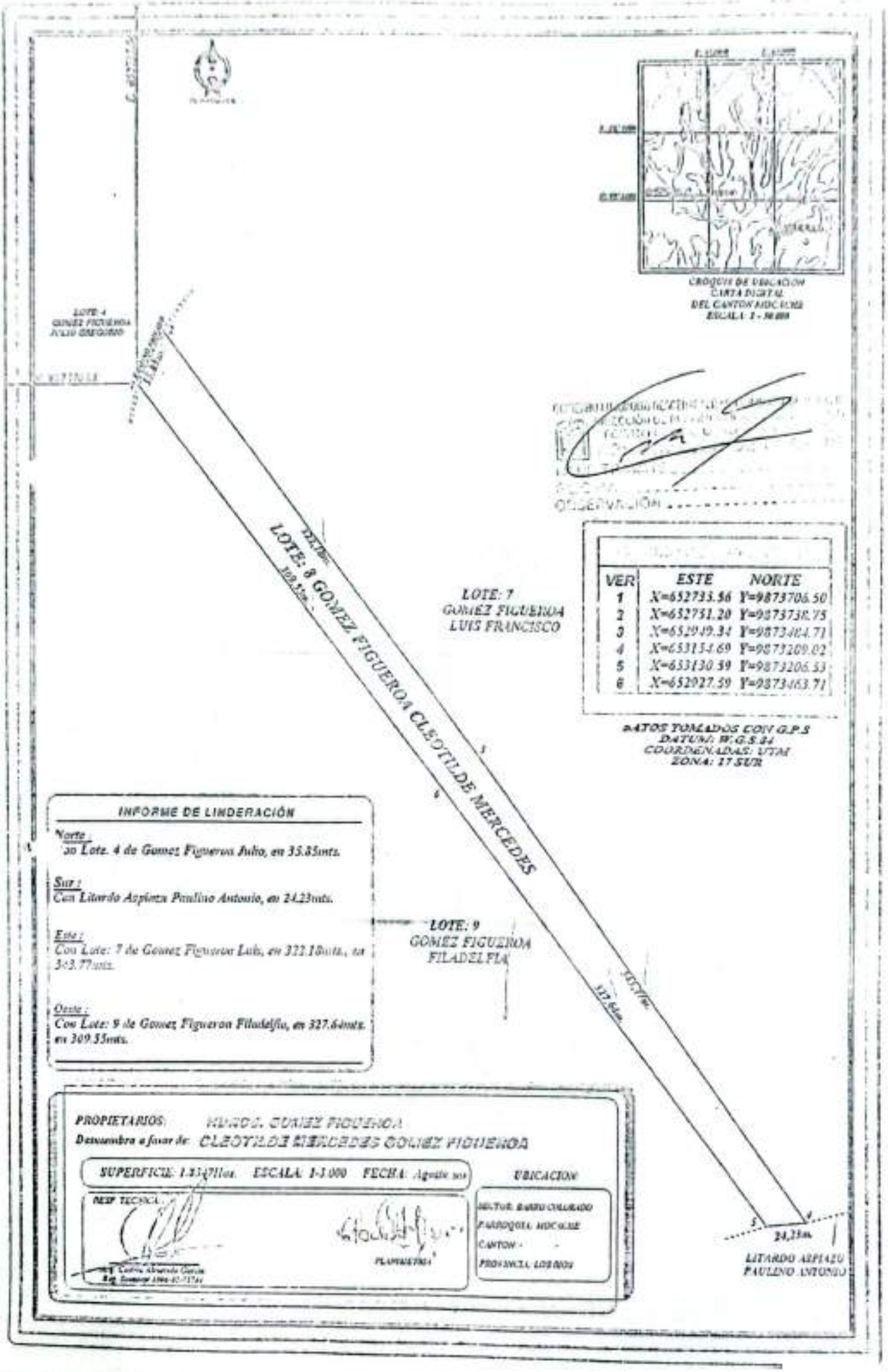

VER	ESTE	NORTE
1	X=652733.56	Y=9873706.50
2	X=652751.20	Y=9873738.75
3	X=652949.34	Y=9873404.71
4	X=653153.69	Y=9873209.02
5	X=653130.59	Y=9873206.53
6	X=652927.59	Y=9873463.71

Escaneado con CamScanner

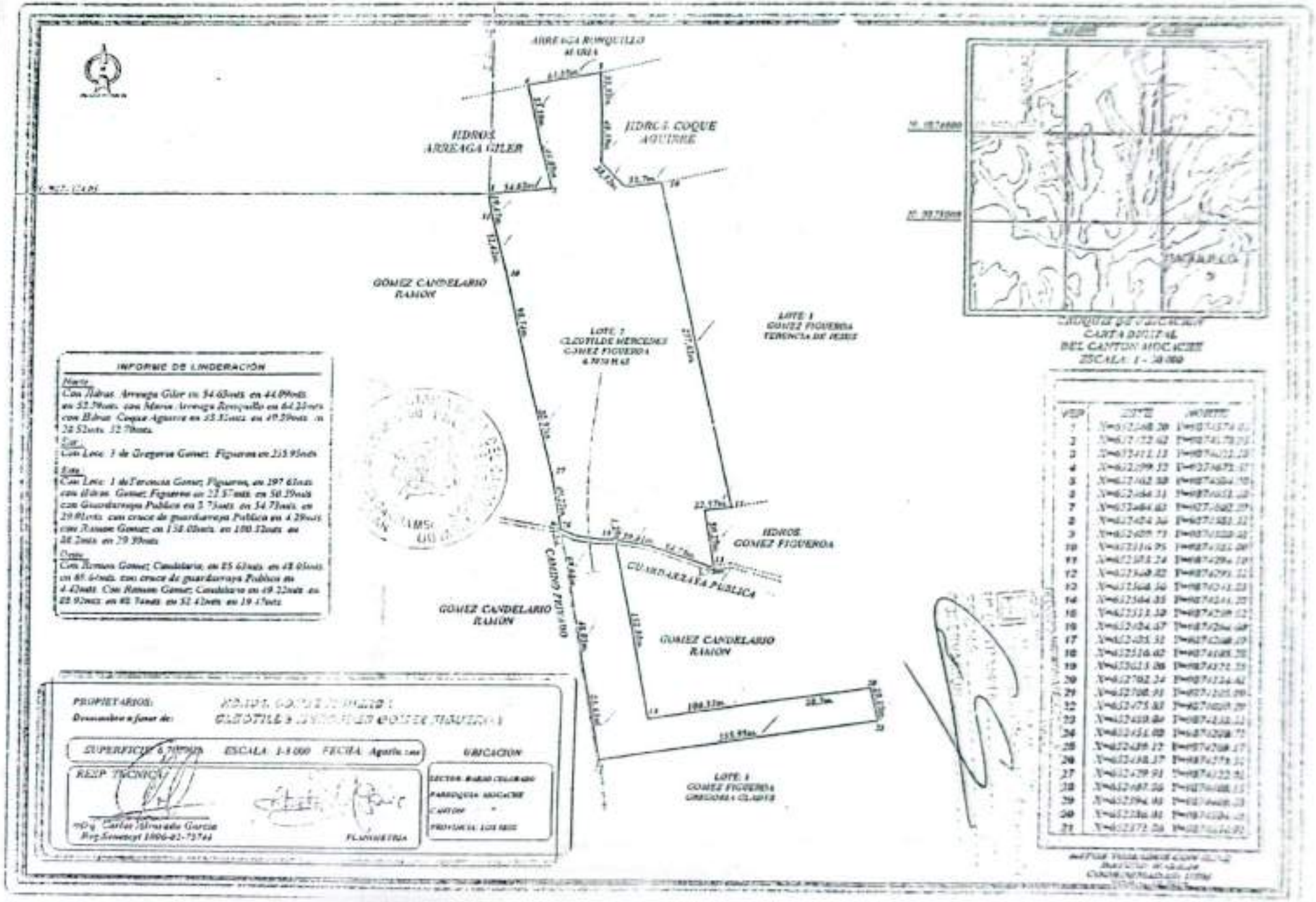

Escaneado con CamScanner

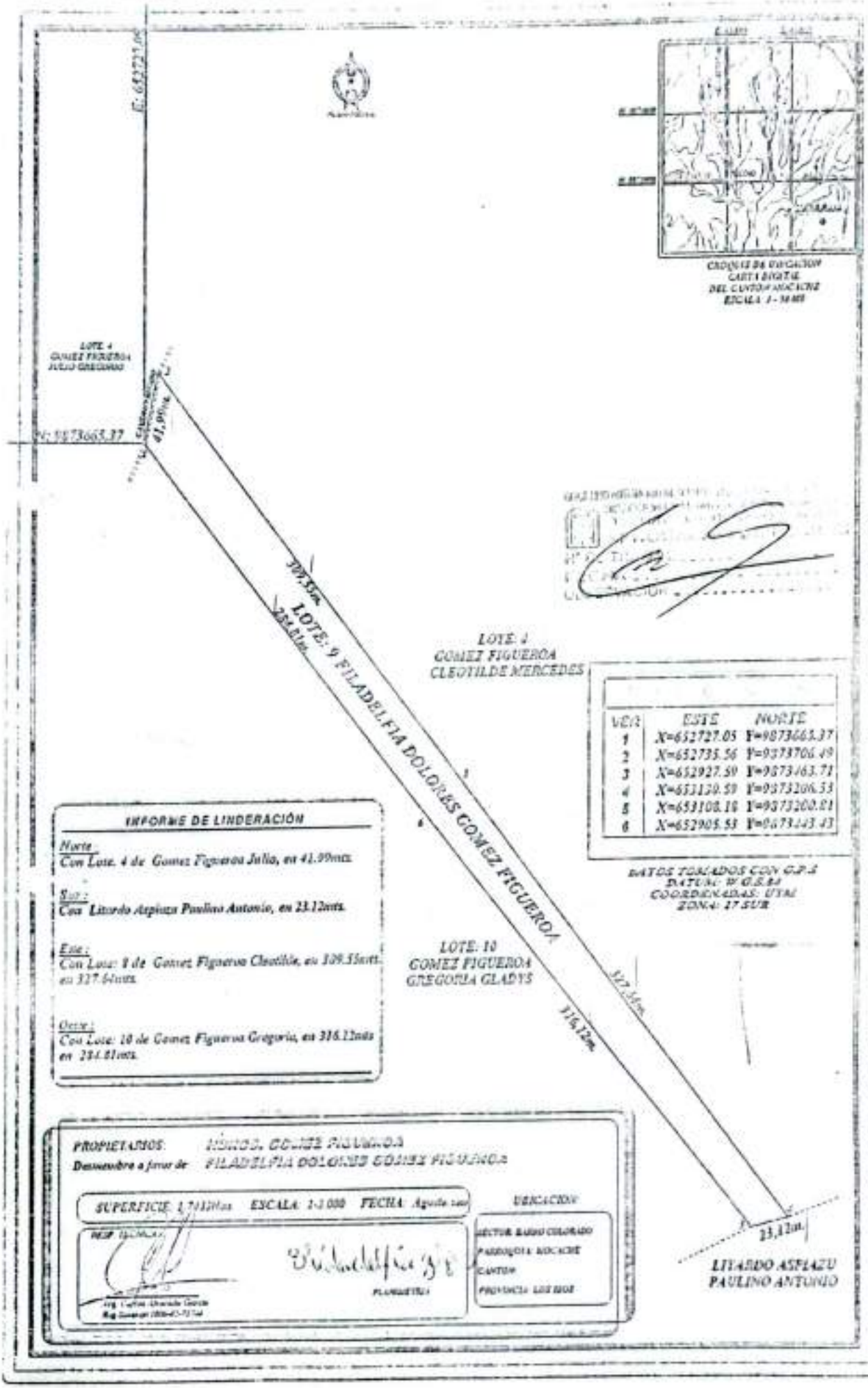

VERT.	ESTE	NORTE
1	X=652727.05	Y=9973663.37
2	X=652735.56	Y=9973706.49
3	X=652927.59	Y=9973763.71
4	X=653120.59	Y=9973206.53
5	X=653108.16	Y=9973200.81
6	X=652905.53	Y=9973143.43

DATOS TOMADOS CON GPS
DATUM: W.G.S.84
COORDENADAS: UTM
ZONA: 17 SUR

Escaneado con CamScanner

VER	ESTE	NORTE
1	X=652475.83	Y=9874069.29
2	X=652708.91	Y=9874106.00
3	X=652719.51	Y=9874060.57
4	X=652727.18	Y=9874027.66
5	X=652745.40	Y=9873954.10
6	X=652762.97	Y=9873906.93
7	X=652757.61	Y=9873903.42
8	X=652770.99	Y=9873884.05
9	X=652595.74	Y=9873767.20
10	X=652527.21	Y=9873843.73
11	X=652513.28	Y=9873843.21
12	X=652507.68	Y=9873865.53
13	X=652503.44	Y=9873901.97
14	X=652500.97	Y=9873923.33
15	X=652495.31	Y=9873965.62
16	X=652485.45	Y=9874007.51
17	X=652479.91	Y=9874048.89

DATOS TOMADOS CON G.P.S
DATUM: W.G.S.84
COORDENADAS: UTM
ZONA: 17 SUR

CROQUIS DE UBICACION
CARTA DIGITAL
DEL CANTON MOCACHE
ESCALA: 1 - 50.000

INFORME DE LINDERACION

Norte:
Con Lote: 2 de Gomez Figueroa Cleotilde, en 235.95mts.

Sur:
Con Lote. 4 de Gomez Figueroa Julio, en 210.64 mts.

Este:
Con Gomez, Candelario Ramon, en 46.64mts. en 33.79mts. en 75.72mts. en 14.14mts. en 6.43mts. en 23.53mts.

Oeste:
Con Gomez Ramon, en 102.73mts. en 13.93mts. en 22.01mts. en 36.69mts. en 21.30mts. en 42.87mts. en 43.04mts. en 41.75mts. en 20.8mts.

PROPIETARIO: GREGORIA GLADYS GOMEZ FIGUEROA

SUPERFICIE: 6.7020Ha. ESCALA: 1-3-000 FECHA: Agosto 2018

UBICACION
SECTOR: BARRIO COLORADO
PARROQUIA: MOCACHE
CANTON
PROVINCIA: LOS RIOS

RESP. TECNICA
Arq. Carlos Alvarado Garcia
Reg. Senescyt 1006-02-75744
PLANIMETRIA

Escaneado con CamScanner



CROQUIS DE UBICACION
CARTA INIETAL
DEL CANTON MOCACHE
ESCALA: 1:50.000

LOTE: 4
GOMEZ FIGUEROA
JULIO GREGORIO

34,90m.

284,81m.

LOTE: 10 GREGORIA GLADYS GOMEZ FIGUEROA

273,83m.

LOTE: 9
GOMEZ FIGUEROA
FILADELFIA DOLORES

LITARDO ASPIAZU
PAULINO ANTONIO

316,12m.

305,65m.

22,00m.

LITARDO ASPIAZU
PAULINO ANTONIO

FECHA: .....
OBSERVACION: .....

VER	ESTE	NORTE
1	X=652713.34	Y=9873633.20
2	X=652727.09	Y=9873665.37
3	X=652905.57	Y=9873443.43
4	X=653108.23	Y=9873200.81
5	X=653087.48	Y=9873193.46
6	X=652886.44	Y=9873421.03

DATOS TOMADOS CON G.P.S
DATUM: W.G.S.84
COORDENADAS: UTM
ZONA: 17 SUR

INFORME DE LINDERACIÓN

Norte:
Con Lote: 4 de Gomez Figueroa Julio, en 34.90mts.

Sur:
Con Litardo Aspiazu Paulino Antonio, en 22mts.

Este:
Con Lote: 9 de Gomez Figueroa Filadelfia, en 284.81mts en 316.12mts.

Oeste:
Con Litardo Aspiazu Paulino Antonio, en 305.65mts, en 273.83mts.

PROPIETARIOS: HDROS. GOMEZ FIGUEROA
Desmembra a favor de: GREGORIA GLADYS GOMEZ FIGUEROA

SUPERFICIE: 1.605Hás. ESCALA: 1-3.000 FECHA: Agosto [illegible]

UBICACION:
SECTOR: BARRIO COLORADO
PARROQUIA: MOCACHE
CANTON:
PROVINCIA: LOS RIOS

RESP. TECNICA:

PLANIMETRIA

Escaneado con CamScanner

REPUBLICA DEL ECUADOR

Dirección General de Registro Civil, Identificación y Cedulación

CERTIFICADO DIGITAL DE DATOS DE IDENTIDAD

Número único de identificación: 0912754009

Nombres del ciudadano: GOMEZ FIGUEROA FILADELFIA DOLORES

Condición del cedulado: CIUDADANO

Lugar de nacimiento: ECUADOR/LOS RIOS/QUEVEDO/QUEVEDO

Fecha de nacimiento: 13 DE NOVIEMBRE DE 1973

Nacionalidad: ECUATORIANA

Sexo: MUJER

Instrucción: BASICA

Profesión: ESTUDIANTE

Estado Civil: SOLTERO

Cónyuge: No Registra

Fecha de Matrimonio: No Registra

Datos del Padre: GOMEZ JULIO

Nacionalidad: ECUATORIANA

Datos de la Madre: FIGUEROA VITA

Nacionalidad: ECUATORIANA

Fecha de expedición: 24 DE FEBRERO DE 2016

Condición de donante: SI DONANTE

Información certificada a la fecha: 19 DE DICIEMBRE DE 2023

Emisor: CARLOS ARMANDO MENDOZA GARCIA - LOS RIOS-QUEVEDO-NT 6 - LOS RIOS - QUEVEDO

N° de certificado: 237-965-63769

237-965-63769

Ing. Carlos Echeverría.
Director General del Registro Civil, Identificación y Cedulación
Documento firmado electrónicamente

La institución o persona ante quien se presente este certificado deberá validarlo en https://validar.registrocivil.gob.ec, conforme a la LOGIDAC Art. 4, numeral 1 y a la LCE. Vigencia del documento 3 validaciones o 2 meses desde el día de su emisión. En caso de presentar inconvenientes con este documento escriba a soporte@registrocivil.gob.ec

Escaneado con CamScanner

REPUBLICA DEL ECUADOR

REPUBLICA DEL ECUADOR
Dirección General de Registro Civil, Identificación y Cedulación

Dirección General de Registro Civil, Identificación y Cedulación

CERTIFICADO DIGITAL DE DATOS DE IDENTIDAD

Número único de identificación: 1203580491

Nombres del ciudadano: GOMEZ FIGUEROA GREGORIA GLADYS

Condición del cedulado: CIUDADANO

Lugar de nacimiento: ECUADOR/LOS RIOS/QUEVEDO/QUEVEDO

Fecha de nacimiento: 28 DE NOVIEMBRE DE 1974

Nacionalidad: ECUATORIANA

Sexo: MUJER

Instrucción: BACHILLERATO

Profesión: EMPLEADO

Estado Civil: CASADO

Cónyuge: TOAPANTA JUCA HERNAN FREDY

Fecha de Matrimonio: 28 DE DICIEMBRE DE 2002

Datos del Padre: GOMEZ CANDELARIO JULIO ALBERTO

Nacionalidad: ECUATORIANA

Datos de la Madre: FIGUEROA ARANA VITA SALUTINA

Nacionalidad: ECUATORIANA

Fecha de expedición: 13 DE JUNIO DE 2023

Condición de donante: NO DONANTE

NOTARIA SEXTA EL CANTON QUEVEDO PROVINCIA DE LOS RIOS
Lic. Carlos Mendoza García
NOTARIO TITULAR

Información certificada a la fecha: 19 DE DICIEMBRE DE 2023

Emisor: CARLOS ARMANDO MENDOZA GARCIA - LOS RIOS-QUEVEDO-NT 6 - LOS RIOS - QUEVEDO

N° de certificado: 236-965-63859

236-965-63859

Ing. Carlos Echeverría
Director General del Registro Civil, Identificación y Cedulación
Documento firmado electrónicamente

La institución o persona ante quien se presenta este certificado deberá validarlo en https://validar.registrocivil.gob.ec, conforme a la LOGIDAC Art. 4, numeral 1 y a la LCE.
Vigencia del documento 3 validaciones o 2 meses desde el día de su emisión. En caso de presentar inconvenientes con este documento escriba a enlinea@registrocivil.gob.ec

Escaneado con CamScanner

CERTIFICADO DIGITAL DE DATOS DE IDENTIDAD

Número único de identificación: 0912753903

Nombres del ciudadano: GOMEZ FIGUEROA CLEOTILDE MERCEDES

Condición del cedulado: CIUDADANO

Lugar de nacimiento: ECUADOR/LOS RIOS/MOCACHE/MOCACHE

Fecha de nacimiento: 29 DE SEPTIEMBRE DE 1971

Nacionalidad: ECUATORIANA

Sexo: MUJER

Instrucción: BASICA

Profesión: QUEHACER. DOMESTICOS

Estado Civil: CASADO

Cónyuge: ARRIAGA RONQUILLO TEODORO CRUZ

Fecha de Matrimonio: 20 DE OCTUBRE DE 1989

Datos del Padre: GOMEZ CANDELARIO JULIO ALBERTO

Nacionalidad: ECUATORIANA

Datos de la Madre: FIGUEROA ARANA VITA SALUTINA

Nacionalidad: ECUATORIANA

Fecha de expedición: 7 DE NOVIEMBRE DE 2022

Condición de donante: NO DONANTE

Información certificada a la fecha: 19 DE DICIEMBRE DE 2023

Emisor: CARLOS ARMANDO MENDOZA GARCIA - LOS RIOS-QUEVEDO-NT 5 - LOS RIOS - QUEVEDO

N° de certificado: 233-965-63931

233-965-63931

Ing. Carlos Echeverría
Director General del Registro Civil, Identificación y Cedulación
Documento firmado electrónicamente

La institución o persona ante quien se presente este certificado podrá validarlo en https://validar.registrocivil.gob.ec, conforme a la LOGIDAC Art. 4, numeral 1 y a la LCE. Vigencia del documento 3 validaciones o 2 meses desde el día de su emisión. En caso de presentar inconvenientes con este documento escriba a enlinea@registrocivil.gob.ec

Escaneado con CamScanner

REPUBLICA DEL ECUADOR
Dirección General de Registro Civil, Identificación y Cedulación

Identificación y Cedulación

CERTIFICADO DIGITAL DE DATOS DE IDENTIDAD

Número único de identificación: 0909786535

Nombres del ciudadano: GOMEZ FIGUEROA TERENCIA DE JESUS

Condición del cedulado: CIUDADANO

Lugar de nacimiento: ECUADOR/GUAYAS/EL EMPALME/VELASCO IBARRA

Fecha de nacimiento: 9 DE ABRIL DE 1966

Nacionalidad: ECUATORIANA

Sexo: MUJER

Instrucción: BASICA

Profesión: QUEHACER. DOMESTICOS

Estado Civil: SOLTERO

Cónyuge: No Registra

Fecha de Matrimonio: No Registra

Datos del Padre: GOMEZ CANDELARIO JULIO ALBERTO

Nacionalidad: ECUATORIANA

Datos de la Madre: FIGUEROA ARANA VITA SALUTINA

Nacionalidad: ECUATORIANA

Fecha de expedición: 26 DE OCTUBRE DE 2015

Condición de donante: SI DONANTE

Información certificada a la fecha: 19 DE DICIEMBRE DE 2023

Emisor: CARLOS ARMANDO MENDOZA GARCIA - LOS RIOS-QUEVEDO-NT 6 - LOS RIOS - QUEVEDO

N° de certificado: 235-965-64029

235-965-64029

Ing. Carlos Echeverría,
Director General del Registro Civil, Identificación y Cedulación
Documento firmado electrónicamente

La institución o persona ante quien se presente este certificado deberá validarlo en https://virtual.registrocivil.gob.ec, conforme a la LOGIDAC Art. 4, numeral 1 y a la LCE. Vigencia del documento 3 validaciones o 2 meses desde el día de su emisión. En caso de presentar inconvenientes con este documento escriba a enlinea@registrocivil.gob.ec

Escaneado con CamScanner

REPUBLICA DEL ECUADOR
Dirección General de Registro Civil, Identificación y Cedulación

Dirección General de Registro Civil, Identificación y Cedulación

CERTIFICADO DIGITAL DE DATOS DE IDENTIDAD

Número único de identificación: 1202559686

Nombres del ciudadano: GOMEZ FIGUEROA LUIS FRANCISCO

Condición del cedulado: CIUDADANO

Lugar de nacimiento: ECUADOR/LOS RIOS/MOCACHE/MOCACHE

Fecha de nacimiento: 30 DE AGOSTO DE 1939

Nacionalidad: ECUATORIANA

Sexo: HOMBRE

Instrucción: BASICA

Profesión: AGRICULTOR

Estado Civil: CASADO

Cónyuge: MENDOZA AGUIRRE GLEIDA ISABEL

Fecha de Matrimonio: 27 DE FEBRERO DE 2007

Datos del Padre: GOMEZ CANDELARIO JULIO

Nacionalidad: ECUATORIANA

Datos de la Madre: FIGUEROA ARANA VITA SALUTINA

Nacionalidad: ECUATORIANA

Fecha de expedición: 27 DE JUNIO DE 2022

Condición de donante: SI DONANTE

Información certificada a la fecha: 10 DE DICIEMBRE DE 2023

Emisor: CARLOS ARMANDO MENDOZA GARCIA - LOS RIOS-QUEVEDO-NT 6 - LOS RIOS - QUEVEDO

N° de certificado: 237-965-64310

237-965-64310

Ing. Carlos Solevería
Director General del Registro Civil, Identificación y Cedulación
Documento firmado electrónicamente

La institución o persona ante quien se presenta este certificado deberá validarlo en http://validar.registrocivil.gob.ec, conforme a la LOGIDAC Art. 4, numeral 1 y a la LCE. Vigencia del documento 3 validaciones o 2 meses desde el día de su emisión. En caso de presentar inconvenientos con este documento escriba a enlinea@registrocivil.gob.ec

Escaneado con CamScanner

CERTIFICADO DIGITAL DE DATOS DE IDENTIDAD

Número único de identificación: 0912744240

Nombres del ciudadano: GOMEZ FIGUEROA JULIO GREGORIO

Condición del cedulado: CIUDADANO

Lugar de nacimiento: ECUADOR/GUAYAS/EL EMPALME/VELASCO IBARRA

Fecha de nacimiento: 16 DE FEBRERO DE 1968

Nacionalidad: ECUATORIANA

Sexo: HOMBRE

Instrucción: BASICA

Profesión: ALBAÑIL

Estado Civil: SOLTERO

Cónyuge: No Registra

Fecha de Matrimonio: No Registra

Datos del Padre: GOMEZ JULIO

Nacionalidad: ECUATORIANA

Datos de la Madre: FIGUEROA VITA SALUTINA

Nacionalidad: ECUATORIANA

Fecha de expedición: 4 DE SEPTIEMBRE DE 2013

Condición de donante: SI DONANTE

Información certificada a la fecha: 19 DE DICIEMBRE DE 2023

Emisor: CARLOS ARMANDO MENDOZA GARCIA - LOS RIOS-QUEVEDO-NT 6 - LOS RIOS - QUEVEDO

N° de certificado: 236-965-64415

236-965-64415

Ing. Carlos Echeverría.
Director General del Registro Civil, Identificación y Cedulación
Documento firmado electrónicamente

La institución o persona ante quien se presente este certificado deberá validarlo en https://virtual.registrocivil.gob.ec, conforme a la LOGIDAC Art. 4, numeral 1 y a la LCE.
Vigencia del documento 3 validaciones o 2 meses desde el día de su emisión. En caso de presentar inconvenientes con este documento escriba a enlinea@registrocivil.gob.ec

Escaneado con CamScanner

REPÚBLICA DEL ECUADOR

APELLIDOS
GOMEZ
FIGUEROA
NOMBRES
CLEOTILDE MERCEDES
NACIONALIDAD
ECUATORIANA
FECHA DE NACIMIENTO
29 SEP 1971
LUGAR DE NACIMIENTO
LOS RIOS MOCACHE
MOCACHE
FECHA DE EXPIRACIÓN
07 NOV 2022

SEXO
MUJER
No. DOCUMENTO
042311183
FECHA DE VENCIMIENTO
07 NOV 2022
PATRIA
[illegible]

MUL0912753993

APELLIDOS Y NOMBRES DEL PADRE
GOMEZ CANDELARIO JULIO ALBERTO
APELLIDOS Y NOMBRES DE LA MADRE
FIGUEROA ARAUJA VIVA SALUTRIA
ESTADO CIVIL
CASADO
APELLIDOS Y NOMBRES DEL CONYUGE O CONVIVIENTE
ARRIAGA RONQUILLO TEODORO CRUZ
LUGAR Y FECHA DE EMISIÓN
MACHALA 07 NOV 2022

V1343V1232
TIPO SANGRE
DONANTE
No donante

DIRECTOR GENERAL

I<ECU0423111833<<<<<091275399
7109290F3211072ECU<NO<DONANTE
GOMEZ<FIGUEROA<<CLEOTILDE<MER

GOMEZ FIGUEROA CLEOTILDE MERCEDES

[illegible]

CIUDADANO:

ESTE DOCUMENTO ACREDITA QUE USTED SUFRAGÓ EN LAS ELECCIONES DEL 15 DE OCTUBRE DE 2023.

La ciudadanía que altere cualquier documento electoral será sancionado de acuerdo a lo que establece el artículo 275 y el numeral 3 del artículo de la LOEOP - Código de la Democracia.

[illegible]
PRESIDENTE DE LA JRV

REPÚBLICA DEL ECUADOR
DIRECTORIO GENERAL DE REGISTRO CIVIL, IDENTIFICACIÓN Y CUPULACIÓN

[illegible] 0909785535

[illegible]

GOMEZ FIGUEROA TERENCIA DE JESUS

[illegible]

CIUDADANO:

ESTE DOCUMENTO ACREDITA QUE USTED SUFRAGÓ EN LAS ELECCIONES DEL 15 DE OCTUBRE DE 2023.

La ciudadanía que altere cualquier documento electoral será sancionado de acuerdo a lo que establece el artículo 275 y el numeral 3 del artículo de la LOEOP - Código de la Democracia.

[illegible]
PRESIDENTE DE LA JRV

[illegible] CANTON DURVEDO. De acuerdo con la facultad prevista [illegible] numeral 5, literal a) de la Ley Notarial, doy fe que la(s) COPIA(S) que antecede(n), es igual al (los) documento(s) exhibido(s) en original (es) ante mí. En [illegible] foja(s).

[illegible]

DR. CARLOS [illegible]
NOTARIO [illegible]

Escaneado con CamScanner

REPÚBLICA DEL ECUADOR
DIRECCIÓN GENERAL DE REGISTRO CIVIL, IDENTIFICACIÓN Y CEDULACIÓN

N° 091275400-9

CÉDULA DE CIUDADANÍA
CIUDADANO/A PRIMERO
GOMEZ FIGUEROA FILADELFIA DOLORES
LUGAR DE NACIMIENTO
LOS RIOS
QUEVEDO
QUEVEDO
FECHA DE NACIMIENTO 1973-11-13
NACIONALIDAD ECUATORIANA
SEXO F
ESTADO CIVIL SOLTERO

BASICA ESTUDIANTE VENCIMIENTO
GOMEZ JULIO
FIGUEROA VITA
GUAYAQUIL
2016-03-24
2016-03-24

GOMEZ FIGUEROA FILADELFIA DOLORES
N° 45134019
PROVINCIA GUAYAS
CIRCUNSCRIPCIÓN 2
CANTÓN GUAYAQUIL
PARROQUIA PASCUALES
ZONA 8
JUNTA No. 0027 FEMENINO
091275400

CIUDADANO/A
ESTE DOCUMENTO ACREDITA QUE USTED SUFRAGÓ EN LAS ELECCIONES DEL 19 DE OCTUBRE DE 2025.
La ciudadana/o que altere cualquier documento electoral será sancionado de acuerdo a lo que establece el artículo 275 y el numeral 3 del artículo de la LOEOP - Código de la Democracia.
FIRMA DEL TITULAR DE LA JEV

REPÚBLICA DEL ECUADOR
FIRMA DEL TITULAR
NUM. 1203580491

I<ECU0531161040<<<<<1203580491
7411283F3306138ECU<NO<DOMANTEG
GOMEZ<FIGUEROA<<GREGORIA<GLADY

GOMEZ FIGUEROA GREGORIA GLADYS
PROVINCIA PICHINCHA
CIRCUNSCRIPCIÓN 1
CANTÓN QUITO
PARROQUIA CARCELÉN
ZONA 3
JUNTA No. 0004 FEMENINO

NOTARIA SEXTA DEL CANTÓN QUEVEDO. De acuerdo con la facultad prevista en el Art. 18 numeral 5, literal a) de la Ley Notarial, doy fe que la (s) COPIA(S) que antecede(n), es igual al (los) documentos(s) exhibido(s) en original (es) ante mí. En (1) foja(s).

Quevedo, a ____

DR. CARLOS MENDOZA GARCÍA MSC
NOTARIO SEXTO DEL CANTÓN QUEVEDO

Escaneado con CamScanner

REPÚBLICA DEL ECUADOR

I<ECU0289371549<<<<<1202559686
6908304M3206272ECU<SI<<<<<<<<8
GOMEZ<FIGUEROA<<LUIS<FRANCISCO

GOMEZ FIGUEROA LUIS
FRANCISCO

La ciudadanía que altere cualquier documento electoral será sancionado de acuerdo a lo que establece el artículo 275 y el numeral 3 del artículo de la LOEOP - Código de la Democracia.

REPÚBLICA DEL ECUADOR

GOMEZ FIGUEROA JULIO
GREGORIO

CIUDADANÍA:

ESTE DOCUMENTO ACREDITA QUE USTED SUFRAGÓ EN LAS ELECCIONES DEL 15 DE OCTUBRE DE 2023.

La ciudadanía que altere cualquier documento electoral será sancionado de acuerdo a lo que establece el artículo 275 y el numeral 3 del artículo de la LOEOP - Código de la Democracia.

NOTARIA SEXTA DEL CANTÓN QUEVEDO. De acuerdo con la facultad prevista en el Art. 18 numeral 5, literal a) de la Ley Notarial, doy fe que la(s) COPIA(S) que antecede(n), es igual al (los) documentos(s) exhibido(s) en original (es) ante mí. En ( ) foja(s).

DR. CARLOS HERNÁN GUEVARA
NOTARIO SEXTO DEL CANTÓN QUEVEDO

Escaneado con CamScanner

uno, y cuarenta y uno de la Ley de Registro.- Usted señor Notario sírvase agregar las demás cláusulas de estilo para la completa validez de esta escritura.- Firma Abogada Nuris Arévalo Zamora. Registro número cero ocho guion dos mil trece guion treinta y cinco. Foro de Abogados del Ecuador.- Es copia de la minuta inserta, la misma que queda elevada a Escritura Pública para que surta sus efectos legales.- Se agregan los impuestos de alcabalas, y sus adicionales, mas documentos habilitantes de ley, etc. Leída esta Escritura de principio a fin, por mí, El Notario en alta voz a los otorgantes, la aprueban en todas sus partes, se afirman, se ratifican, y firman en unidad de acto conmigo. - Doy fe.

TERENCIA DE JESUS GOMEZ FIGUEROA
C.C. N° 090978653-5

JULIO GREGORIO GOMEZ FIGUEROA
C.C. N° 091274424-0

LUIS FRANCISCO GOMEZ FIGUEROA
C.C. N° 120255968-6

Escaneado con CamScanner

CLEOTILDE MERCEDES GOMEZ FIGUEROA

C.C. N° 091275399-3

GREGORIA GLADYS GOMEZ FIGUEROA

C.C. N° 120358049-1

FILADELFIA DOLORES GOMEZ FIGUEROA

C.C. N° 091275400-9

Dr. CARLOS ARMANDO MENDOZA GARCIA, MSc.

NOTARIO SEXTO DE ESTE CANTON

Se otorgó ante mí, en fe de ello confiero este **SEXTO TESTIMONIO**, que sello, firmo y rubrico, a los diecinueve días del mes de diciembre del dos mil veintitrés. -

NOTARIA SEXTA
CANTÓN QUEVEDO
LOS RIOS – ECUADOR

Dr. CARLOS ARMANDO MENDOZA GARCIA, MSc

NOTARIO SEXTO DEL CANTON QUEVEDO

Escaneado con CamScanner